RÉPUBLIQUE FRANÇAISE
Liberté Égalité Fraternité

METEO FRANCE
À VOS CÔTÉS, DANS UN CLIMAT QUI CHANGE

Bulletin d'estimation du risque d'avalanche
(valable en dehors des pistes balisées et ouvertes)
MASSIF : Embrunais Parpaillon

Rédigé le mardi 17 Février 2026 à 16h

Estimation des risques pour le : MERCREDI 18 FÉVRIER

FRÉQUENTES INSTABILITÉS DANS LA NEIGE FRAÎCHE FORTEMENT VENTÉE

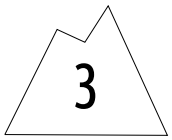

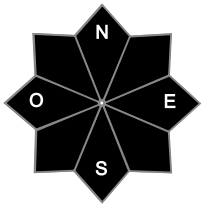

Indice de risque marqué.

Départs spontanés : quelques départs de neige fraîches s'humidifiant au soleil en cours de journée.

Déclenchements provoqués : plaques fréquentes dans la neige fraiche, même à moyenne altitude.

Indices de risque : 5 très fort - 4 fort - 3 marqué - 2 limité - 1 faible -- En noir : les pentes les plus dangereuses

Stabilité du manteau neigeux

Situation avalancheuse typique : neige ventée couche fragile persistante

Déclenchements provoqués : des plaques encore sensibles sont en place en toutes orientations dans la neige fraîche, fortement ventées jusqu'en basse montagne. Ces instabilités sont plus fréquentes à moyenne altitude, même dans des secteurs plutôt abrités des vents habituellement (forêts peu denses par exemple). Près des crêtes et sommets, ces plaques sont plus dures et difficiles à déclencher, et sont réparties de façon plus hétérogène, avec des accumulations localement épaisses qui côtoient des secteurs décapés par le vent tempétueux. Avalanches de taille petite à moyenne (taille 1 à 2). De rares grandes voir très grande avalanche (taille 3 à 4) sont possibles en cas de sollicitation d'une couche fragile persistante enfouie en ubac, emportant une grande partie du manteau neigeux en place. Ce type de départ peut être initié par la surcharge liée au passage d'une première avalanche de surface.

Départs spontanés : Départs ponctuels en neige fraiche s'humidifiant, rares au levé du jour, puis de plus en plus nombreux en fil de l'ensoleillement. Avalanche de taille petite à moyenne (taille 1 à 2) plutôt en versant ensoleillés, mais possible aussi dans les ubacs noyés dans les nuages bas. Des départs linéaires de taille moyenne voir grande (taille 2 à 3) sont aussi possibles en cas de déstabilisation d'une plaque en place.

Qualité de la neige

L'enneigement est légèrement excédentaire pour un mois de février.
Hauteurs de neige observées : 94 cm à la Nivôse du Parpaillon à 2550 m, secteur soufflé par le vent.

Limite d'enneigement skiable : dès 1200/1400 m en ubacs sur la plupart des itinéraires, plutôt 1400/1500 m en adrets favorables.

État de la neige de surface : petite couche de neige fraiche en surface fortement travaillée par le vent dans la plupart des pentes au-dessus de 1800/2000. Crêtes décapées par le vent de nord-ouest alternant avec de grosses accumulations/corniches. Neige restant localement plus légère et froide le matin en toutes orientations dans les secteurs bien abrités du vent. Elle devient humide à collante au soleil en journée en dessous de 2000/2200 m.

Aperçu météo pour le mercredi 18 février

Ciel voilé mais lumineux, avec quelques nuages bas en vallées.

	nuit	matin	après-midi	soir
Pluie-Neige				1 500 m
Iso 0 °C	1 500 m	2 000 m	2 100 m	1 900 m
Vent 2000 m	↘ 15 km/h	↗ 15 km/h	↗ 15 km/h	↗ 20 km/h
Vent 3000 m	↘ 45 km/h	↘ 40 km/h	→ 35 km/h	↗ 60 km/h

Épaisseur de neige hors-piste

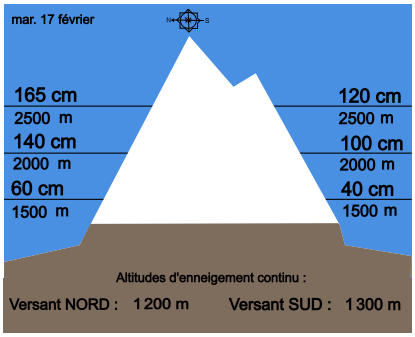

Précipitations à 1800 m

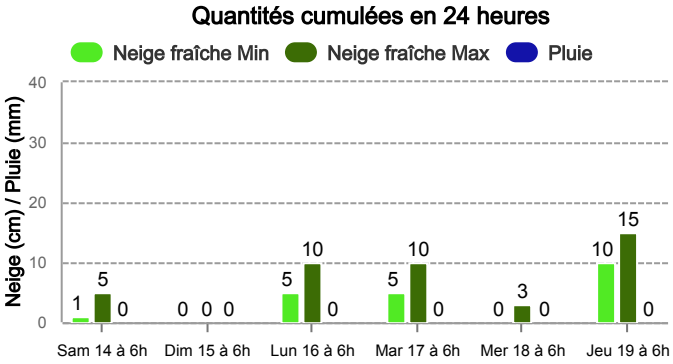

Tendance du jeudi 19 février

Indice de risque fort

Risque en hausse, devenant fort, avec l'arrivée de nouvelles chutes de neige parfois intenses dans la nuit de mercredi à jeudi. Nombreux départs spontanés attendus, pouvant être de grande ampleur.

Pour consulter la vigilance en cours, veuillez vous rendre sur le site https://vigilance.meteofrance.fr/fr

Météo-France - 73 avenue de Paris, 94165 Saint-Mandé cedex - Contact : contact@meteo.fr

Bulletin neige & avalanches par téléphone au **0 892 68 10 20** Service 0,35 € / min + prix appel

Rédigé par Météo-France avec la contribution des observateurs du réseau nivo-météorologiques. Partenariat : ANMSM (Maires de Stations de Montagne), DSF (Domaines Skiables de France), ADSP (Directeurs de Pistes et de la Sécurité des Stations de Sports d'Hiver) et autres acteurs de la montagne.

RÉPUBLIQUE FRANÇAISE
Liberté Égalité Fraternité

METEO FRANCE
À VOS CÔTÉS, DANS UN CLIMAT QUI CHANGE

Bulletin d'estimation du risque d'avalanche

(valable en dehors des pistes balisées et ouvertes)

MASSIF : Embrunais Parpaillon

Rédigé le mardi 17 février 2026 à 16h

Conditions nivo-météo des 7 derniers jours

	mer. 11/02				jeu. 12/02				ven. 13/02				sam. 14/02				dim. 15/02				lun. 16/02				mar. 17/02			
	03h	09h	15h	21h	03h	09h	15h	21h	03h	09h	15h	21h	03h	09h	15h	21h	03h	09h	15h	21h	03h	09h	15h	21h	03h	09h	15h	21h
Météo																												
Vent (km/h)	70	65	60	40	90	70	90	60	50	30	30	50	60	60	40	70	60	80	50	45	70	110	130	110	95	85	75	70
à 3000m																												
Vent (km/h)	20	25	30	25	30	35	45	35	20	10	15	20	25	25	25	30	30	30	20	20	20	60	75	65	55	40	35	20
à 2000m																												

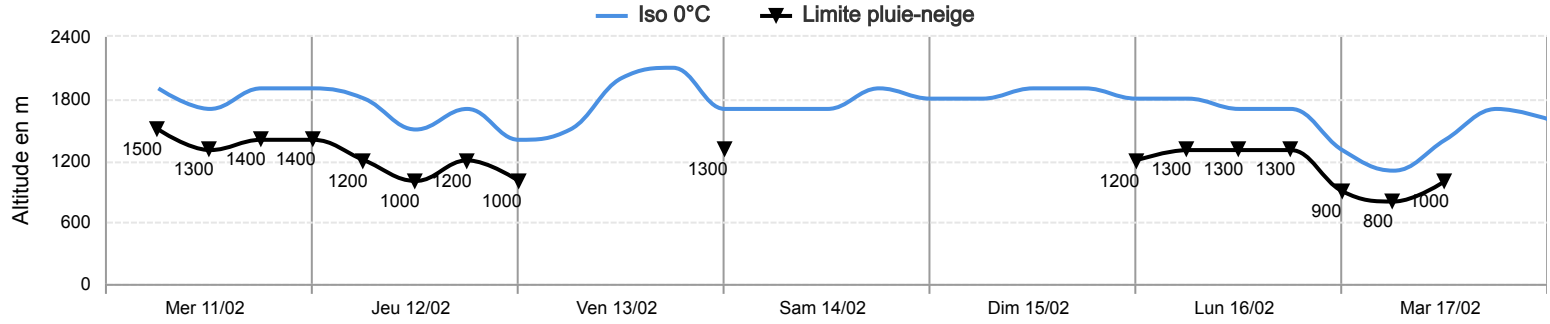

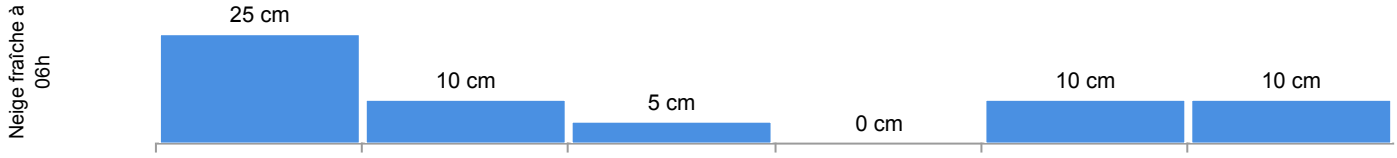

Risque d'avalanche	mer. 11/02	jeu. 12/02	ven. 13/02	sam. 14/02	dim. 15/02	lun. 16/02	mar. 17/02
	4	4	4	4	3	3	3

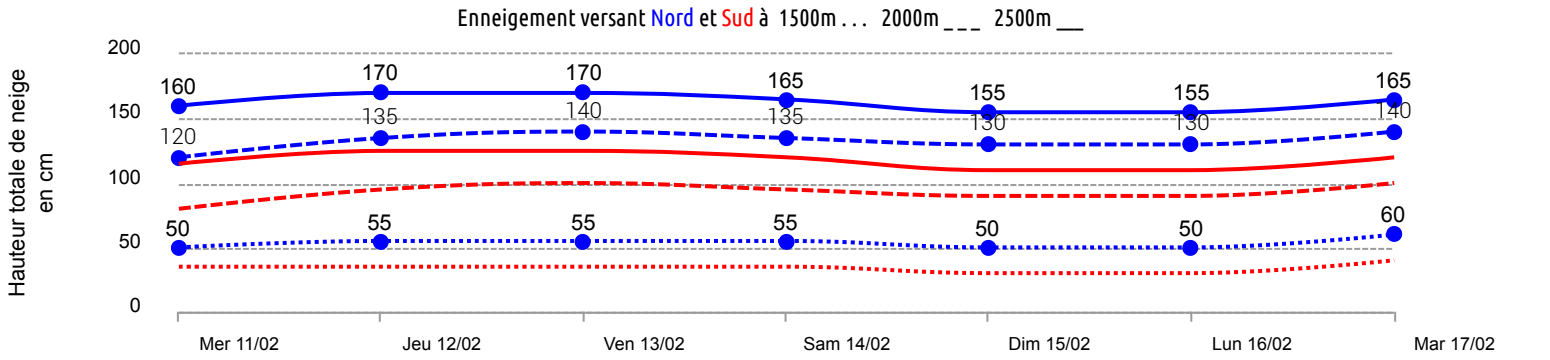

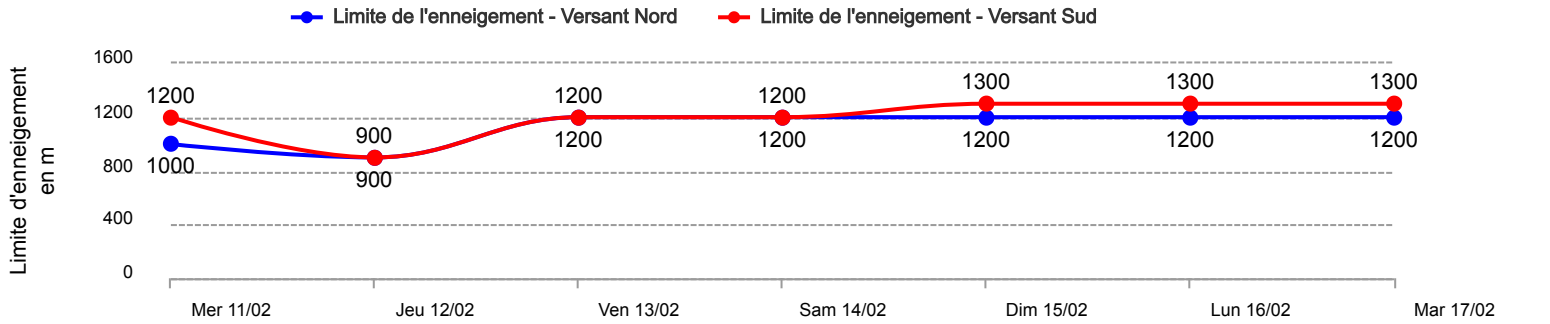

Pour consulter la vigilance en cours, veuillez vous rendre sur le site https://vigilance.meteofrance.fr/fr

Météo-France - 73 avenue de Paris, 94165 Saint-Mandé cedex - Contact : contact@meteo.fr

Rédigé par Météo-France avec la contribution des observateurs du réseau nivo-météorologiques. Partenariat : ANMSM (Maires de Stations de Montagne), DSF (Domaines Skiables de France), ADSP (Directeurs de Pistes et de la Sécurité des Stations de Sports d'Hiver) et autres acteurs de la montagne.

Bulletin neige & avalanches par téléphone au

0 892 68 10 20 Service 0,35 € / min + prix appel