RÉPUBLIQUE FRANÇAISE
Liberté Égalité Fraternité

METEO FRANCE
À VOS CÔTÉS, DANS UN CLIMAT QUI CHANGE

Bulletin d'estimation du risque d'avalanche

(valable en dehors des pistes balisées et ouvertes)

MASSIF : Grandes-Rousses

Rédigé le mardi 17 Février 2026 à 16h

Estimation des risques pour le : MERCREDI 18 FÉVRIER

ENCORE UN FORT RISQUE ACCIDENTEL EN ALTITUDE, PARFOIS A DISTANCE DE PENTES RAIDES. LOCALEMENT, DES AVALANCHES SPONTANEES AU SOLEIL, DEVALANT DE LONGS COULOIRS...

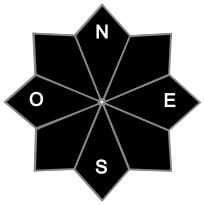

Altitude+ au soleil

Indice de risque fort.

Départs spontanés : Mercredi, près des rochers lors d'éclaircies des avalanches de neige récente, parfois très conséquentes et descendant les couloirs jusqu'en moyenne montagne ? En pentes herbeuses de modeste altitude, rare avalanche de fond...

Déclenchements provoqués : Risque accidentel encore fort en altitude, parfois à distance de pentes raides ! Risque de très larges ruptures en "cascade"...

Indices de risque : 5 très fort - 4 fort - 3 marqué - 2 limité - 1 faible -- En noir : les pentes les plus dangereuses

Stabilité du manteau neigeux

Situation avalancheuse typique : neige ventée couche fragile persistante

Grosses quantités de neige fraîche/récente très peu stabilisée en altitude avec risque de déclenchement à distance. Noter aussi un redoux probable lors d'éclaircies, risque d'avalanche spontanée aussi vers les rochers, dans les couloirs...
En résumé la haute montagne à peine pentue et les couloirs sont infréquentables...

Départs spontanés :
Mercredi avec un redoux relatif en mi-journée/l'après-midi, on peut s'attendre à de nombreuses avalanches de surface de taille moyenne, notamment près des rochers. Localement ces avalanches peuvent prendre de l'ampleur (pentes récemment chargées par le vent de Nord-Ouest). Une avalanche pourrait dévaler un long couloir avec de gros dépôts jusqu'en moyenne montagne, près des routes (vers Vaujany par exemple ?)... Enfin dans certaines pentes herbeuses de modeste altitude, on peut redouter une avalanche de fond (glissement au terrain), plutôt le soir.

Déclenchements provoqués :
En haute montagne, les récentes épaisses plaques (formées par flux de Nord-Ouest) ne sont pas bien stabilisées. Ce risque accidentel est aussi présent loin des crêtes, au passage d'une personne... Par déclenchement en cascade une énorme avalanche n'est pas exclue en contrebas (configuration aggravante : présence de couches fragiles enfouies en versants froids). Mardi une large cassure accidentelle a été déclenchée à distance en Oisans.
Sous 1800m environ les sous couches se sont un peu tassées, risque accidentel a priori plus localisé, près des crêtes. En pentes ensoleillées, risque de départ humide ponctuel sous les skis...
Mercredi soir le vent de Sud-Sud-Ouest va se lever en altitude et formera de nouvelles plaques bien instables !

Qualité de la neige

Qualification de l'enneigement : L'enneigement est très bon pour la saison dès la moyenne altitude puis abondant dès 1600/1800m et dans toutes les combes... Hautes crêtes parfois dégarnies/ grosses congères et corniches...
Limites skiables : vers 1100/1300 m...
Qualité de la neige mercredi : Le matin neige fraîche poudreuse en combes abritées, épaisse en altitude.
Lors des éclaircies, sous 2000/2200m environ neige collante puis humide en surface. A l'abord des croupes/crêtes d'altitude neige très chahutée, irrégulière, de grosses corniches...

Aperçu météo pour le mercredi 18 février

	nuit	matin	après-midi	soir

Passages nuageux le matin, puis des éclaircies l'après-midi, rafales de Sud mercredi soir, avant une nouvelle perturbation...

Pluie-Neige				1 700 m
Iso 0 °C	1 400 m	2 000 m	2 300 m	2 200 m
Vent 2000 m	↘ 20 km/h	↘ 20 km/h	↑ 20 km/h	↗ 65 km/h
Vent 3000 m	↘ 45 km/h	→ 30 km/h	↗ 40 km/h	↗ 90 km/h

Épaisseur de neige hors-piste

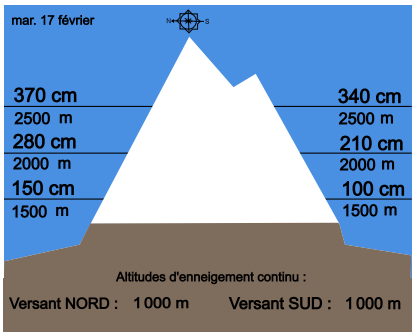

Précipitations à 1800 m

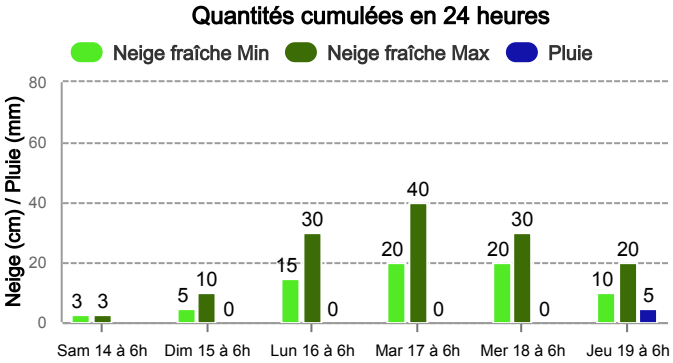

Tendance du jeudi 19 février

Indice de risque très fort

Risque d'avalanche en hausse, devenant très fort jeudi soir ou vendredi matin ?
Jeudi 20 cm de fraîche le matin, 50 voire 60 cm le soir sous le vent de Nord Ouest.
Risque de rupture de corniches/épaisses plaques. Nombreux couloirs impactés/voire certaines routes.

Pour consulter la vigilance en cours, veuillez vous rendre sur le site https://vigilance.meteofrance.fr/fr

Météo-France - 73 avenue de Paris, 94165 Saint-Mandé cedex - Contact : contact@meteo.fr

Bulletin neige & avalanches par téléphone au **0 892 68 10 20** Service 0,35 € / min + prix appel

Rédigé par Météo-France avec la contribution des observateurs du réseau nivo-météorologiques. Partenariat : ANMSM (Maires de Stations de Montagne), DSF (Domaines Skiables de France), ADSP (Directeurs de Pistes et de la Sécurité des Stations de Sports d'Hiver) et autres acteurs de la montagne.

RÉPUBLIQUE FRANÇAISE
Liberté Égalité Fraternité

METEO FRANCE
À VOS CÔTÉS, DANS UN CLIMAT QUI CHANGE

Bulletin d'estimation du risque d'avalanche

(valable en dehors des pistes balisées et ouvertes)

MASSIF : Grandes-Rousses

Rédigé le mardi 17 février 2026 à 16h

Conditions nivo-météo des 7 derniers jours

	mer. 11/02				jeu. 12/02				ven. 13/02				sam. 14/02				dim. 15/02				lun. 16/02				mar. 17/02			
	03h	09h	15h	21h	03h	09h	15h	21h	03h	09h	15h	21h	03h	09h	15h	21h	03h	09h	15h	21h	03h	09h	15h	21h	03h	09h	15h	21h
Météo																												
Vent (km/h)	100	85	85	100	100	100	90	40	35	25	35	15	25	20	50	45	50	45	45	55	70	85	110	120	100	80	60	40
à 3000m																												
Vent (km/h)	80	65	50	50	50	50	55	15	10	10	10	20	25	5	20	10	5	10	25	30	40	60	80	80	70	55	45	25
à 2000m																												

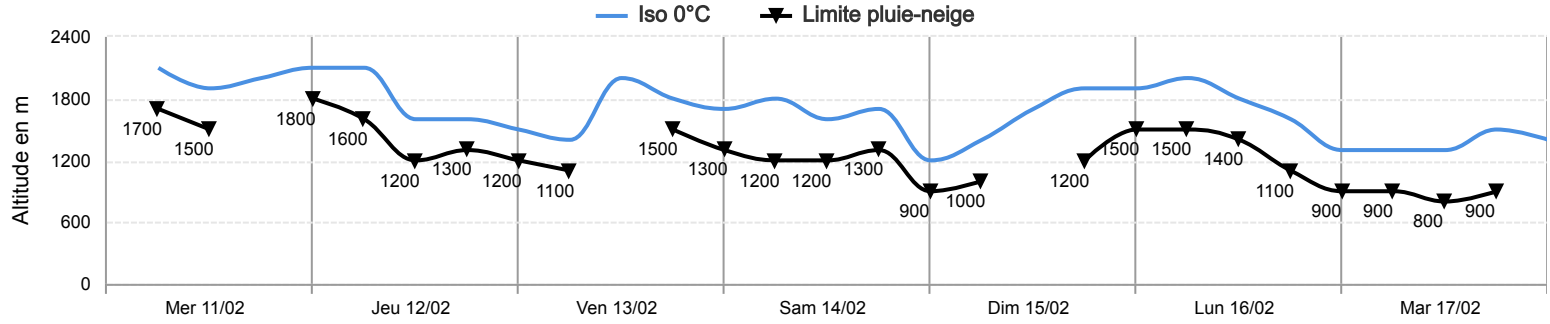

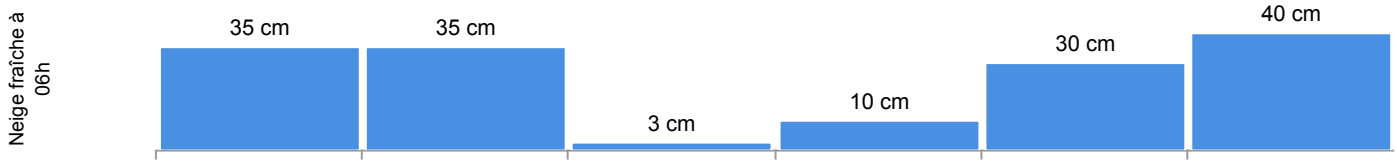

Risque d'avalanche	mer. 11/02	jeu. 12/02	ven. 13/02	sam. 14/02	dim. 15/02	lun. 16/02	mar. 17/02
	4	5	4	4	3	4	4

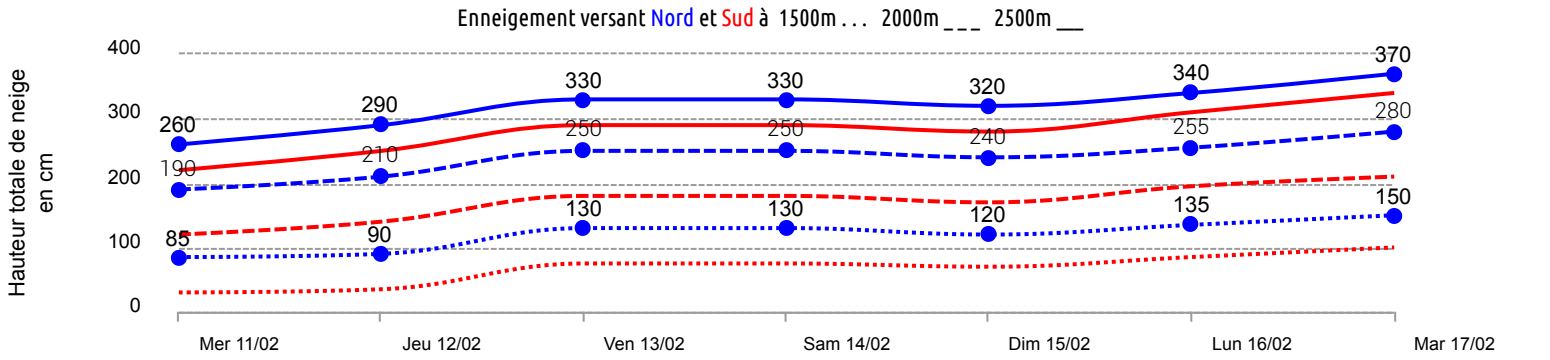

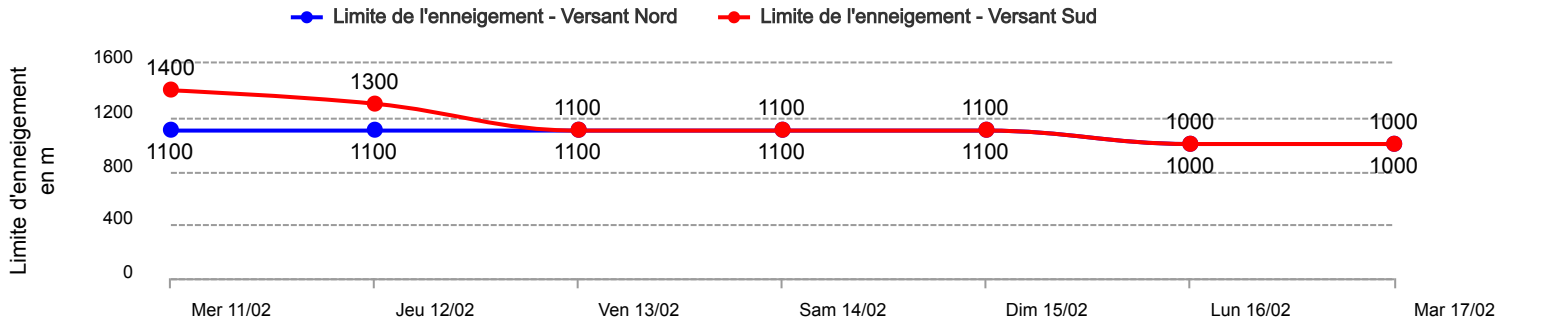

Pour consulter la vigilance en cours, veuillez vous rendre sur le site https://vigilance.meteofrance.fr/fr

Météo-France - 73 avenue de Paris, 94165 Saint-Mandé cedex - Contact : contact@meteo.fr

Bulletin neige & avalanches par téléphone au **0 892 68 10 20** Service 0,35 € / min + prix appel

Rédigé par Météo-France avec la contribution des observateurs du réseau nivo-météorologiques. Partenariat : ANMSM (Maires de Stations de Montagne), DSF (Domaines Skiables de France), ADSP (Directeurs de Pistes et de la Sécurité des Stations de Sports d'Hiver) et autres acteurs de la montagne.