Bulletin d'estimation du risque d'avalanche

(valable en dehors des pistes balisées et ouvertes)

MASSIF : Haut-Var Haut-Verdon

Rédigé le mardi 17 Février 2026 à 16h

Estimation des risques pour le : MERCREDI 18 FÉVRIER

INSTABILITÉ RESTANT MARQUÉE DANS LA NEIGE RÉCENTE VENTÉE

3

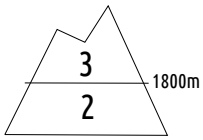

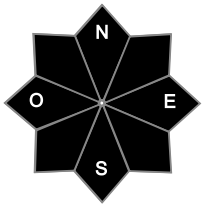

Au-dessus de 1800m indice de risque marqué, plus bas indice limité.

Départs spontanés : ponctuels en neige récente humide au soleil, nombreux et parfois volumineux en Haut Verdon

Déclenchements provoqués : nombreuses instabilités facilement déclenchables dans la neige récente

Indices de risque : 5 très fort - 4 fort - 3 marqué - 2 limité - 1 faible -- En noir : les pentes les plus dangereuses

Stabilité du manteau neigeux

Situation avalancheuse typique : neige fraîche couche fragile persistante

Déclenchements provoqués : manteau neigeux instable en altitude. Instabilités dans la neige récente possibles en toutes orientations au-dessus de 1800/2000 m environ. Elles se présentent sous forme de plaques d'aspect friable, souvent fortement durcies par le vent en Haut Var, localisées même loin des crêtes et déclenchables par un seul skieur. Ces instabilités mobilisent parfois l'ensemble de la neige récente tombée depuis une semaine, engendrant des avalanches de taille moyenne (taille 2), rarement grandes (taille 3) dans les zones de forte accumulation par le vent.
En orientation ouest, nord ou est d'altitude supérieure à 2000/2200 m environ, grandes avalanches (taille 3) sont plus probables, une très grande (taille 4) n'est pas exclue dans les pentes d'un large secteur nord de haute altitude du Haut Verdon. La couche fragile persistante enfouie à la base du manteau neigeux est encore localement sollicitable et peut engendrer des départs linéaires de grande largeur. Déclenchement direct peu probable (mais aléatoire) par un skieur isolé, souvent rendu possible, en cascade, par une première avalanche de surface.
Sous 1800/2000 m, et jusque 2200/2400 m en pentes bien ensoleillées, les instabilités sont moins fréquentes et moins volumineuses (taille 1 le plus souvent), mais déclenchables par un seul skieur. La neige de surface prenant temporairement une bonne cohésion avec le redoux.

Départs spontanés : surtout en neige humide. Nombreux départs ponctuels au soleil, restant superficiels et généralement de taille 1 à 2. Une grande avalanche n'est cependant pas exclue, notamment en Haut Verdon; l'ensoleillement accompagné d'un net réchauffement de la masse d'air entraîne une humidification dans les pentes sud raides où l'enneigement est particulièrement abondant. Une grande avalanche par départ de plaque à vent en large versant nord de haute altitude n'est pas exclue à haute altitude en fin de journée, avec le net renforcement du vent de secteur sud.

Qualité de la neige

Enneigement très excédentaire pour un mois de février. Il faut remonter à 2014 pour trouver un enneigement encore plus abondant à cette période de l'année.
Données observées : en ubacs, 1 m dès 1600/1700 m, 1m 50 à 2 m vers 2000 m, 2 m à 2m 50 vers 2400 m.

Enneigement skiable dès 1200 m en terrains favorables, 1500 m en adrets.

État de la neige en surface : 10/30 cm de neige récente souvent fortement travaillée par le vent en altitude, restée légère et poudreuse en ubacs abrités du vent, notamment en forêts au-dessus de 1800 m ; elle est plus tassée voire finement croûtée sous 1600/1800 m. En journée, humidification superficielle au soleil jusque 2200/2400 m.

Aperçu météo pour le mercredi 18 février

	nuit	matin	après-midi	soir

Très beau et peu venté, avant une nouvelle perturbation active la nuit suivante.

Pluie-Neige				
Iso 0 °C	1 800 m	2 000 m	2 200 m	2 000 m
Vent 2000 m	↘ 30 km/h	↘ 30 km/h	→ 15 km/h	↖ 40 km/h
Vent 3000 m	↘ 45 km/h	↘ 40 km/h	↘ 35 km/h	↑ 65 km/h

Épaisseur de neige hors-piste

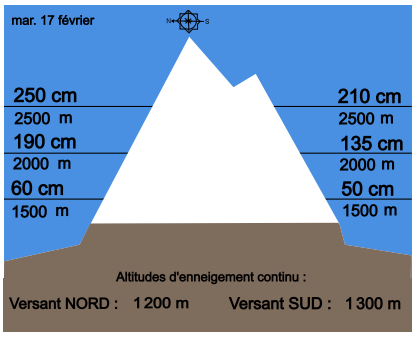

Précipitations à 1800 m

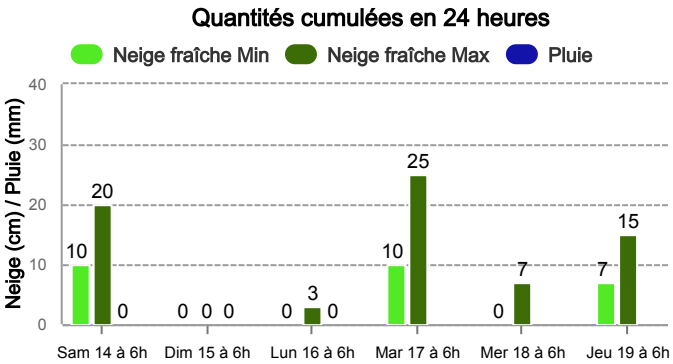

Tendance du jeudi 19 février

Indice de risque fort

Risque en hausse. Bref passage perturbé actif en fin de nuit de mercredi à jeudi : chutes de neige peu ventées ~20 cm, suivies d'un renforcement du vent de nord-ouest et d'une reprise des chutes de neige en journée de jeudi. Nombreuses instabilités facilement déclenchables, mobilisant encore d'importants volumes de neige en altitude. Risque fort.

Pour consulter la vigilance en cours, veuillez vous rendre sur le site https://vigilance.meteofrance.fr/fr

Météo-France - 73 avenue de Paris, 94165 Saint-Mandé cedex - Contact : contact@meteo.fr

Rédigé par Météo-France avec la contribution des observateurs du réseau nivo-météorologiques. Partenariat : ANMSM (Maires de Stations de Montagne), DSF (Domaines Skiables de France), ADSP (Directeurs de Pistes et de la Sécurité des Stations de Sports d'Hiver) et autres acteurs de la montagne.

Bulletin neige & avalanches par téléphone au

0 892 68 10 20 Service 0,35 € / min + prix appel

RÉPUBLIQUE FRANÇAISE
Liberté Égalité Fraternité

METEO FRANCE
À VOS CÔTÉS, DANS UN CLIMAT QUI CHANGE

Bulletin d'estimation du risque d'avalanche

(valable en dehors des pistes balisées et ouvertes)

MASSIF : Haut-Var Haut-Verdon

Rédigé le mardi 17 Février 2026 à 16h

Conditions nivo-météo des 7 derniers jours

	mer. 11/02				jeu. 12/02				ven. 13/02				sam. 14/02				dim. 15/02				lun. 16/02				mar. 17/02			
	03h	09h	15h	21h	03h	09h	15h	21h	03h	09h	15h	21h	03h	09h	15h	21h	03h	09h	15h	21h	03h	09h	15h	21h	03h	09h	15h	21h
Météo																												
Vent (km/h)	100	110	60	70	80	100	140	130	90	30	40	55	70	70	60	40	35	45	45	55	65	85	110	100	90	75	70	60
à 3000m																												
Vent (km/h)	20	20	30	40	80	90	120	115	60	15	20	25	35	45	40	35	5	5	15	35	50	50	80	70	65	50	50	40
à 2000m																												

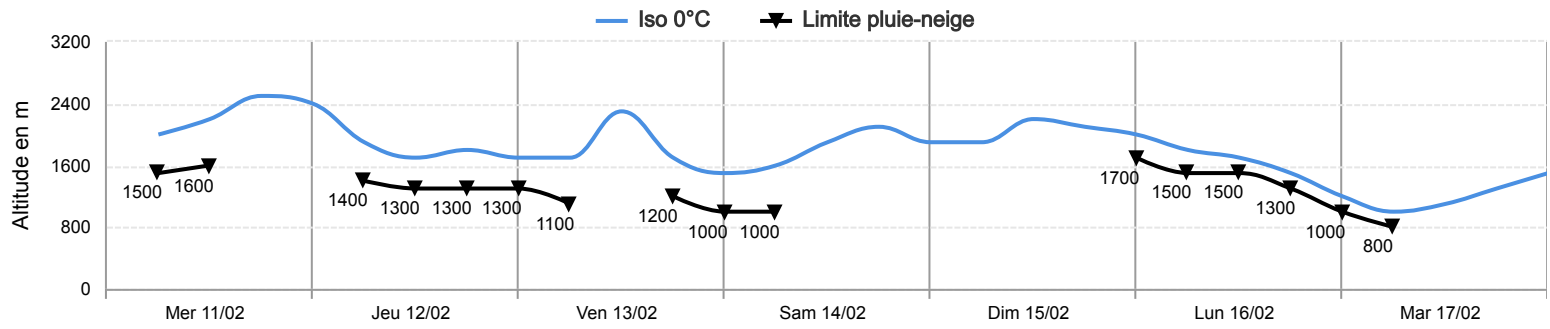

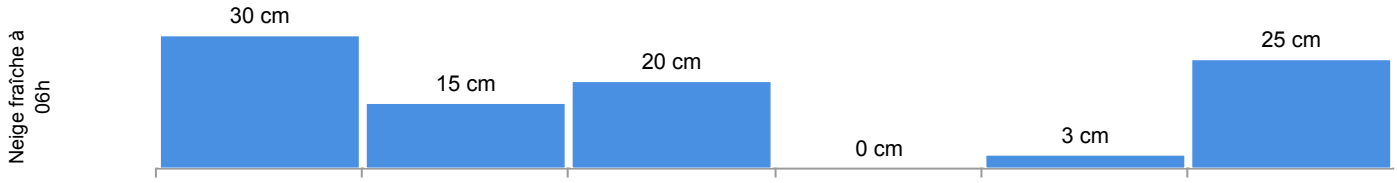

Risque d'avalanche	mer. 11/02	jeu. 12/02	ven. 13/02	sam. 14/02	dim. 15/02	lun. 16/02	mar. 17/02
	3	4	4	3	3	3	3

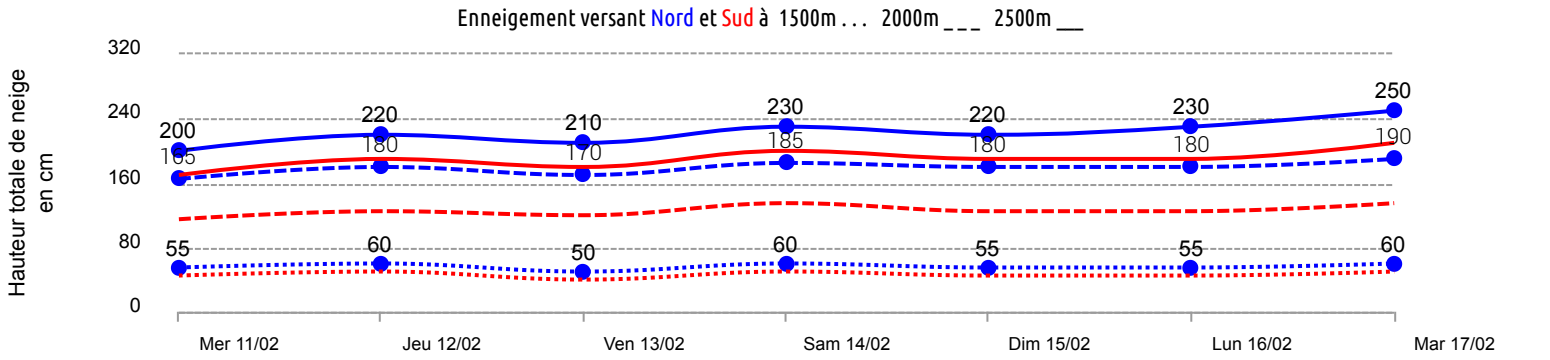

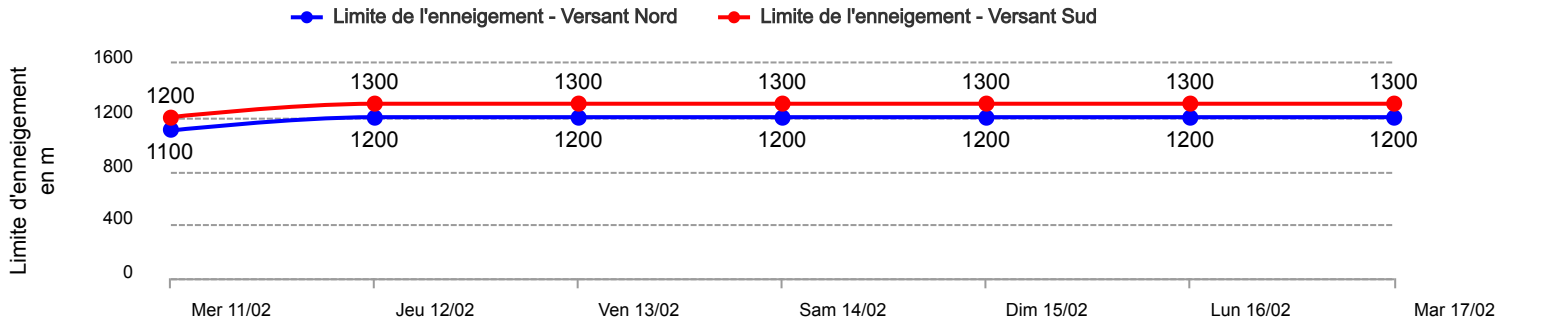

Pour consulter la vigilance en cours, veuillez vous rendre sur le site https://vigilance.meteofrance.fr/fr

Météo-France - 73 avenue de Paris, 94165 Saint-Mandé cedex - Contact : contact@meteo.fr

Bulletin neige & avalanches par téléphone au

0 892 68 10 20 Service 0,35 € / min + prix appel

Rédigé par Météo-France avec la contribution des observateurs du réseau nivo-météorologiques. Partenariat : ANMSM (Maires de Stations de Montagne), DSF (Domaines Skiables de France), ADSP (Directeurs de Pistes et de la Sécurité des Stations de Sports d'Hiver) et autres acteurs de la montagne.