RÉPUBLIQUE FRANÇAISE
Liberté Égalité Fraternité

METEO FRANCE
À VOS CÔTÉS, DANS UN CLIMAT QUI CHANGE

Bulletin d'estimation du risque d'avalanche

(valable en dehors des pistes balisées et ouvertes)

MASSIF : Haute-Bigorre

Rédigé le mardi 17 Février 2026 à 16h

Estimation des risques pour le : MERCREDI 18 FÉVRIER

PLAQUES INSTABLES EN ALTITUDE, NEIGE HUMIDE AU SOLEIL.

3

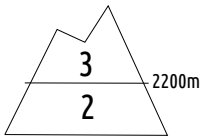

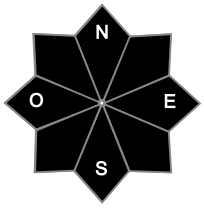

Au-dessus de 2200m indice de risque marqué, plus bas indice limité.

Départs spontanés : en neige humide.

Déclenchements provoqués : plaques instables au-dessus de 2200m.

Indices de risque : 5 très fort - 4 fort - 3 marqué - 2 limité - 1 faible -- En noir : les pentes les plus dangereuses

Stabilité du manteau neigeux

Situation avalancheuse typique : neige ventée neige humide

Déclenchements provoqués :
Risque **marqué au-dessus de 2200m** :
- dans un **large secteur nord-est/sud-est/sud-ouest**, avalanches de **plaques friables facilement déclenchables** par un seul skieur ou randonneur. Les chutes de neige faibles depuis lundi soir, sous le vent d'ouest à nord-ouest modéré, ont formé des plaques de **faibles épaisseurs**, en général **friables et peu identifiables,** mais posées sur des plaques plus épaisses formées en fin de semaine dernière et pas impactées ni stabilisées par les pluies de lundi dernier. Ces empilements de plaques récentes et plus anciennes restent **sensibles à une faible sollicitation**. Le pratiquant peut ainsi déclencher des avalanches de **taille 2 à 3**.
- dans les **autres secteurs**, plus exposés au vent, les plaques sont un peu **plus minces, légèrement plus dures** mais **plus facilement identifiables**, elles-aussi posées sur les plaques plus anciennes, le tout restant sensible à de **faibles sollicitations** et susceptible de **propager facilement une cassure**. Au vu de l'épaisseur de neige mobilisable, avalanches de **taille 2 à localement 3** possiblement déclenchables sous les skis, pieds ou raquettes.

Risque **limité en dessous de 2200m,** surtout **l'après-midi dans les versants sud-est à sud-ouest doux et ensoleillés** : il sera aisé pour un skieur ou randonneur de déclencher une **petite avalanche de neige humide en pente raide**.

Départs spontanés : en **neige humide** et en **pentes raides** est à sud et sud-ouest qui **prennent le soleil**. Départs souvent ponctuels de taille petite à moyenne, rares au petit matin, plus nombreux au fil des heures et de l'ensoleillement.
Avalanches de **taille moyenne à rarement grande possibles** au **plus chaud de la journée sous le soleil** direct, en partant d'une **pente raide d'altitude** (supérieure à 2200m) avec **accumulation**; le **déclenchement des plaques décrites ci-dessus**, par effet de cascade, peut entraîner **tout ou partie de la neige en contrebas**, générant **localement une avalanche de fond**.

Qualité de la neige

Enneigement : toujours en léger retrait, les chutes de neige de mardi ayant été faibles. Crêtes, cols et sommets en expositions ouest souvent pelés ou en neige très dure ou en glace. Manteau neigeux débutant vers 1200m, encore assez épais entre 1500 et 2000m en zones déventées. Répartition plus hétérogène de la neige au-dessus de 2000m.
Limites skiables : à partir de 1300m en nord, 1400 à 1500m en sud.
État de la neige : manteau neigeux humidifié, tassé et plus ou moins regelé selon l'altitude, recouvert de quelques centimètres de neige fraîche et sèche au petit matin, frittée à cartonnée dans les pentes ouest à nord au-dessus de 2000m. Le temps doux et ensoleillé de la journée ramollira les pentes sud, humidifiera les pentes ombragées sous 1800m, la neige de ces mêmes pentes restera en l'état au-dessus de 1800m.

Aperçu météo pour le mercredi 18 février

	nuit	matin	après-midi	soir
	Temps sec, beau en journée, venté de sud-ouest à sud		l'après-midi, dégradation neigeuse et vent d'ouest à nord-ouest soutenu la nuit suivante.	
Pluie-Neige			1 900 m	1 100 m
Iso 0 °C	2 400 m	2 600 m	2 200 m	1 400 m
Vent 2000 m	↑ 10 km/h	↗ 35 km/h	↗ 45 km/h	↓ 30 km/h
Vent 3000 m	→ 55 km/h	↗ 80 km/h	↗ 95 km/h	→ 85 km/h

Pour consulter la vigilance en cours, veuillez vous rendre sur le site https://vigilance.meteofrance.fr/fr

Météo-France - 73 avenue de Paris, 94165 Saint-Mandé cedex - Contact : contact@meteo.fr

Rédigé par Météo-France avec la contribution des observateurs du réseau nivo-météorologiques. Partenariat : ANMSM (Maires de Stations de Montagne), DSF (Domaines Skiables de France), ADSP (Directeurs de Pistes et de la Sécurité des Stations de Sports d'Hiver) et autres acteurs de la montagne.

Bulletin neige & avalanches par téléphone au
0 892 68 10 20 Service 0,35 € / min + prix appel

Bulletin d'estimation du risque d'avalanche

(valable en dehors des pistes balisées et ouvertes)

MASSIF : Haute-Bigorre

Rédigé le mardi 17 février 2026 à 16h

Épaisseur de neige hors-piste

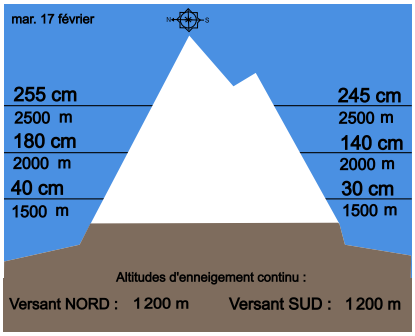

Précipitations à 1800 m

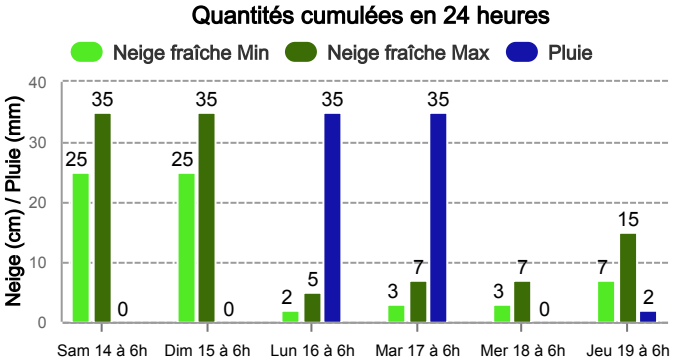

Tendance du jeudi 19 février

Indice de risque marqué

Les chutes de neige ventées d'ouest à nord-ouest attendues jeudi maintiendront un risque accidentel marqué, avec une limite d'altitude certainement plus basse.

Pour consulter la vigilance en cours, veuillez vous rendre sur le site https://vigilance.meteofrance.fr/fr

Météo-France - 73 avenue de Paris, 94165 Saint-Mandé cedex - Contact : contact@meteo.fr

Rédigé par Météo-France avec la contribution des observateurs du réseau nivo-météorologiques. Partenariat : ANMSM (Maires de Stations de Montagne), DSF (Domaines Skiables de France), ADSP (Directeurs de Pistes et de la Sécurité des Stations de Sports d'Hiver) et autres acteurs de la montagne.

Bulletin neige & avalanches par téléphone au

0 892 68 10 20 Service 0,35 € / min + prix appel

RÉPUBLIQUE FRANÇAISE
Liberté Égalité Fraternité

METEO FRANCE
À VOS CÔTÉS, DANS UN CLIMAT QUI CHANGE

Bulletin d'estimation du risque d'avalanche

(valable en dehors des pistes balisées et ouvertes)

MASSIF : Haute-Bigorre

Rédigé le mardi 17 Février 2026 à 16h

Conditions nivo-météo des 7 derniers jours

	mer. 11/02				jeu. 12/02				ven. 13/02				sam. 14/02				dim. 15/02				lun. 16/02				mar. 17/02			
	03h	09h	15h	21h	03h	09h	15h	21h	03h	09h	15h	21h	03h	09h	15h	21h	03h	09h	15h	21h	03h	09h	15h	21h	03h	09h	15h	21h
Météo																												
Vent (km/h)	90	110	110	120	120	120	90	70	85	75	100	115	85	60	65	40	35	40	80	90	95	85	75	80	60	55	60	65
à 3000m																												
Vent (km/h)	40	60	80	100	100	100	70	40	60	50	45	75	55	55	55	40	40	15	35	50	55	35	60	60	55	45	25	10
à 2000m																												

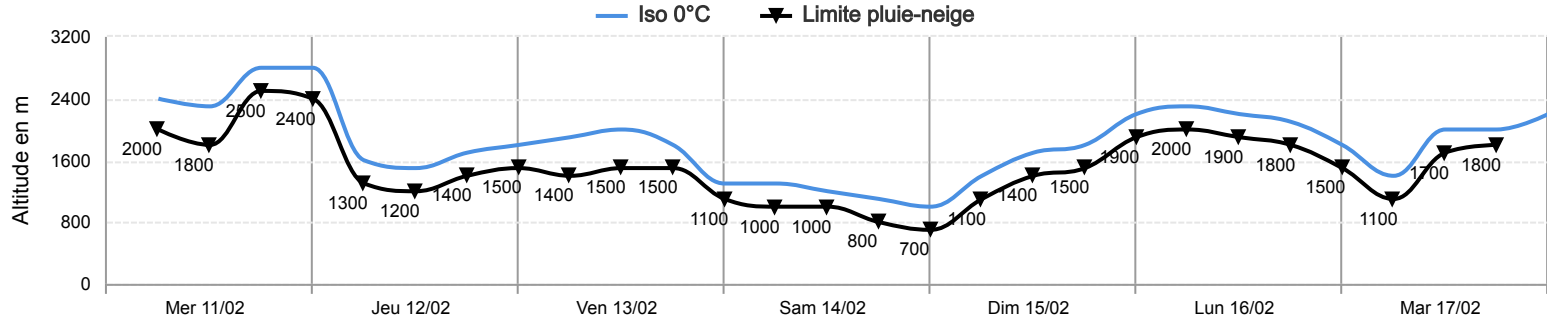

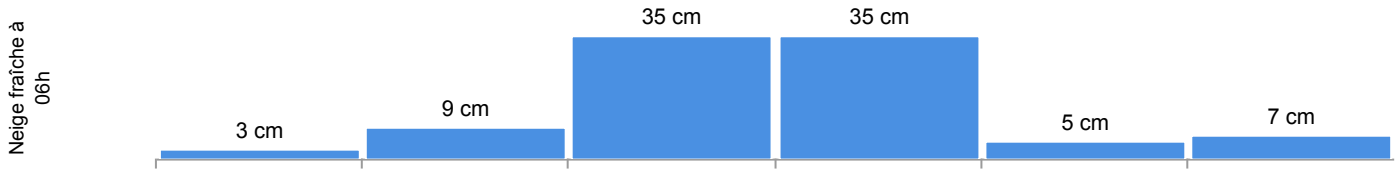

Risque d'avalanche	mer. 11/02	jeu. 12/02	ven. 13/02	sam. 14/02	dim. 15/02	lun. 16/02	mar. 17/02
	4	3	2	3	4	4	4

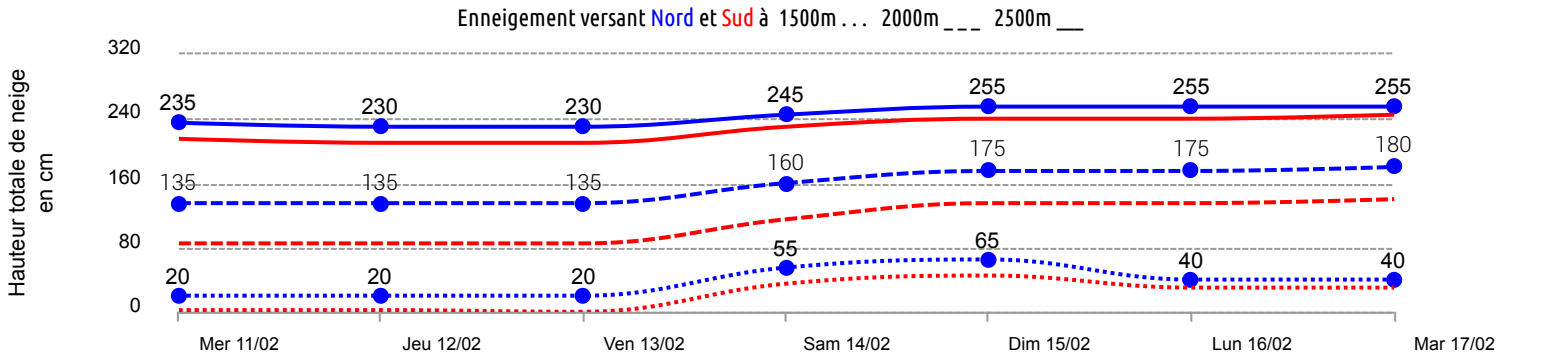

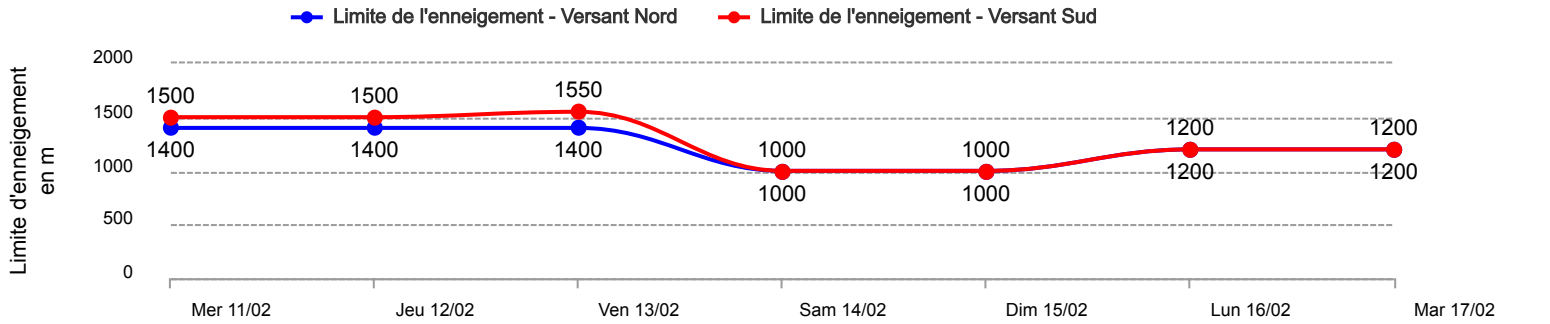

Pour consulter la vigilance en cours, veuillez vous rendre sur le site https://vigilance.meteofrance.fr/fr

Météo-France - 73 avenue de Paris, 94165 Saint-Mandé cedex - Contact : contact@meteo.fr

Bulletin neige & avalanches par téléphone au

0 892 68 10 20 Service 0,35 € / min + prix appel

Rédigé par Météo-France avec la contribution des observateurs du réseau nivo-météorologiques. Partenariat : ANMSM (Maires de Stations de Montagne), DSF (Domaines Skiables de France), ADSP (Directeurs de Pistes et de la Sécurité des Stations de Sports d'Hiver) et autres acteurs de la montagne.