Bulletin d'estimation du risque d'avalanche

(valable en dehors des pistes balisées et ouvertes)

MASSIF : Mercantour

Rédigé le mardi 17 Février 2026 à 16h

Estimation des risques pour le : MERCREDI 18 FÉVRIER

INSTABILITÉS PERSISTANT DANS LA NEIGE FORTEMENT VENTÉE

3

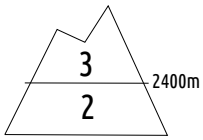

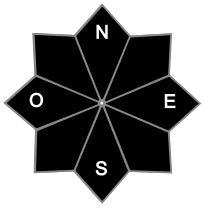

Au-dessus de 2400m indice de risque marqué, plus bas indice limité.

Départs spontanés : ponctuels en neige récente humide au soleil, nombreux et parfois volumineux

Déclenchements provoqués : nombreux et parfois volumineux dans la neige ventée

Indices de risque : 5 très fort - 4 fort - 3 marqué - 2 limité - 1 faible -- En noir : les pentes les plus dangereuses

Stabilité du manteau neigeux

Situation avalancheuse typique : neige ventée neige humide

Déclenchements provoqués : manteau neigeux localement instable en altitude, au-dessus de 2200 m. Instabilités possibles en toutes orientations, plutôt disséminées en orientations ouest à nord, plus fréquentes et parfois épaisses loin des crêtes d'un large secteur est, et sud au-delà de 2600/2700 m. Parfois déclenchables par un seul skieur, elles engendrent des avalanches de taille petite à moyenne (taille 1 à 2), rarement grandes (taille 3) dans les zones de forte accumulation par le vent. Généralement d'aspect dur et plutôt bien identifiables, ces instabilités mobilisent surtout la neige tombée depuis vendredi soir. Le déclenchement des couches fragiles persistantes situées à la base de l'épais manteau neigeux est très peu probable par un seul skieur ; on ne peut cependant l'exclure en cascade, par une avalanche de neige ventée particulièrement volumineuse, ce qui peut engendrer alors une avalanche de très grande taille (taille 4).

Départs spontanés : surtout en neige humide. Nombreux départs ponctuels au soleil, restant superficiels et généralement de taille 1 à 2. Une grande avalanche n'est cependant pas exclue, notamment en Vésubie / Roya; l'ensoleillement accompagné d'un net réchauffement de la masse d'air entraîne une humidification dans les pentes sud raides où l'enneigement est particulièrement abondant. Une grande avalanche par départ de plaque à vent en large versant nord de haute altitude n'est pas exclue à haute altitude en fin de journée, avec le net renforcement du vent de secteur sud.

Qualité de la neige

Enneigement très excédentaire pour un mois de février. Il faut remonter à 2015 pour trouver un enneigement encore plus abondant à cette période de l'année.
Données observées : 154 cm à la nivôse de Millefonts, 126 cm à Isola 2000.

Enneigement skiable dès 1300 m en ubacs en terrains favorables et 1600 m en adrets

État de la neige en surface : fortement durcie par le vent en altitude, y compris en Haute Tinée vers la Bonette où il est tombé 10/20 cm de neige lundi. Encore meuble en ubacs forestiers de moyenne altitude, localement profonde en Vésubie et Roya. Poursuite de l'humidification au soleil en adrets, s'humidifiant au soleil ce mardi : superficiellement jusque 2200/2400 m, en profondeur sous 1800 m.

Aperçu météo pour le mercredi 18 février

nuit	matin	après-midi	soir

Très beau et peu venté, avant une nouvelle perturbation active la nuit suivante.

Pluie-Neige				
Iso 0 °C	2 100 m	2 200 m	2 400 m	2 200 m
Vent 2000 m	↘ 15 km/h	↘ 15 km/h	→ 20 km/h	↗ 40 km/h
Vent 3000 m	↘ 35 km/h	→ 25 km/h	→ 35 km/h	↗ 75 km/h

Épaisseur de neige hors-piste

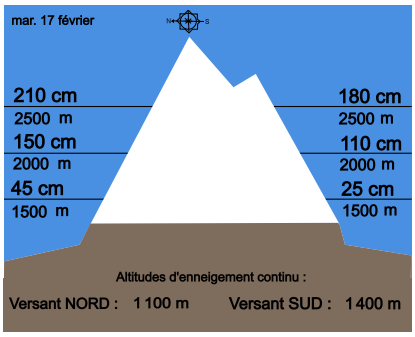

Précipitations à 1800 m

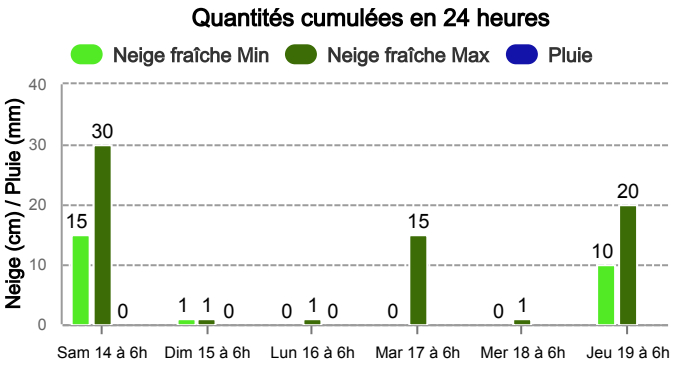

Tendance du jeudi 19 février

Indice de risque fort

Risque en hausse. Passage perturbé très actif jeudi matin : chutes de neige peu ventées ~30/40 cm, suivies d'un renforcement du vent de nord-ouest. Nombreuses instabilités facilement déclenchables, mobilisant encore d'importants volumes de neige en altitude. Risque fort.

Pour consulter la vigilance en cours, veuillez vous rendre sur le site https://vigilance.meteofrance.fr/fr

Météo-France - 73 avenue de Paris, 94165 Saint-Mandé cedex - Contact : contact@meteo.fr

Rédigé par Météo-France avec la contribution des observateurs du réseau nivo-météorologiques. Partenariat : ANMSM (Maires de Stations de Montagne), DSF (Domaines Skiables de France), ADSP (Directeurs de Pistes et de la Sécurité des Stations de Sports d'Hiver) et autres acteurs de la montagne.

Bulletin neige & avalanches par téléphone au 0 892 68 10 20 Service 0,35 € / min + prix appel

RÉPUBLIQUE FRANÇAISE
Liberté Égalité Fraternité

METEO FRANCE
À VOS CÔTÉS, DANS UN CLIMAT QUI CHANGE

Bulletin d'estimation du risque d'avalanche

(valable en dehors des pistes balisées et ouvertes)

MASSIF : Mercantour

Rédigé le mardi 17 février 2026 à 16h

Conditions nivo-météo des 7 derniers jours

	mer. 11/02				jeu. 12/02				ven. 13/02				sam. 14/02				dim. 15/02				lun. 16/02				mar. 17/02			
	03h	09h	15h	21h	03h	09h	15h	21h	03h	09h	15h	21h	03h	09h	15h	21h	03h	09h	15h	21h	03h	09h	15h	21h	03h	09h	15h	21h
Météo																												
Vent (km/h)	80	75	50	70	85	95	90	85	55	30	40	50	80	90	75	65	45	30	40	50	55	75	100	80	75	70	50	40
à 3000m																												
Vent (km/h)	30	40	35	25	40	65	45	40	30	20	25	20	50	75	65	50	30	10	20	30	30	40	65	40	60	50	20	20
à 2000m																												

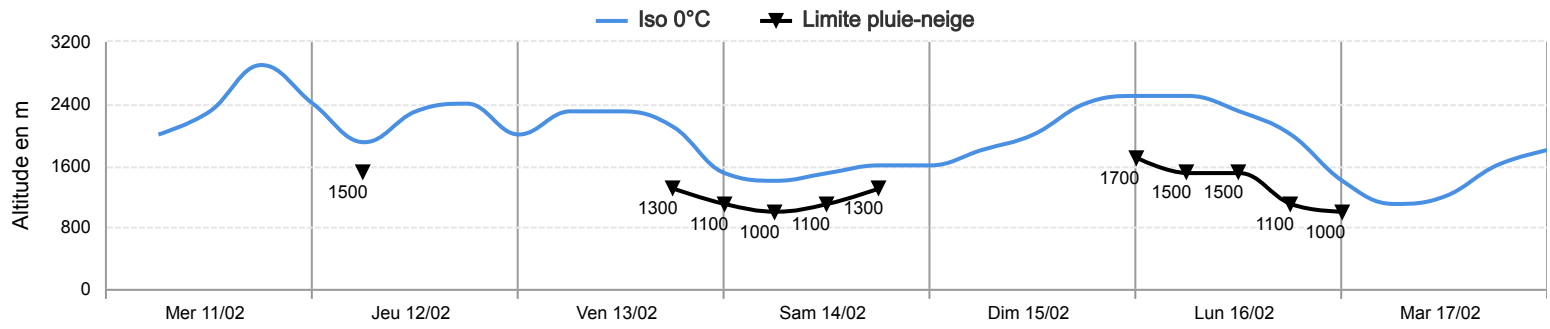

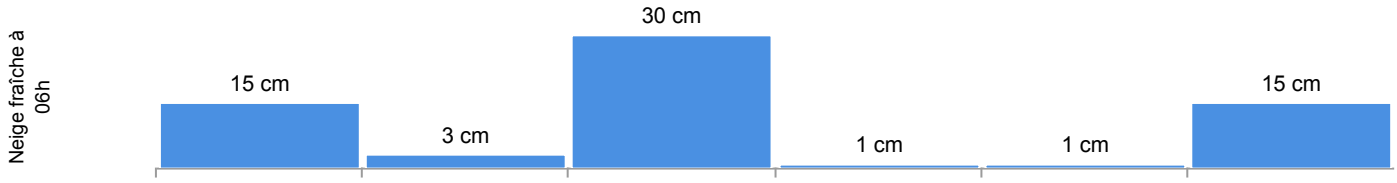

Risque d'avalanche	mer. 11/02	jeu. 12/02	ven. 13/02	sam. 14/02	dim. 15/02	lun. 16/02	mar. 17/02
	3	2	2	3	3	3	3

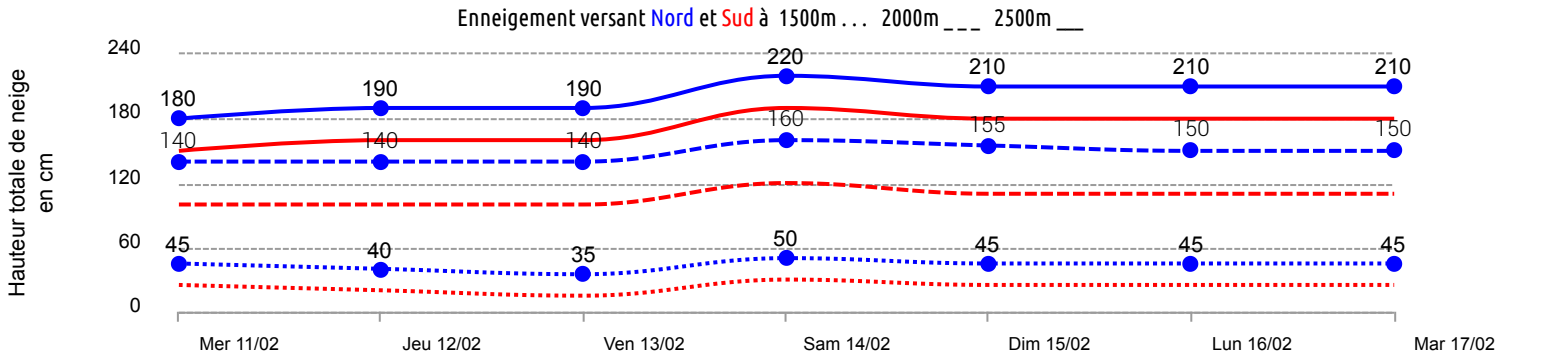

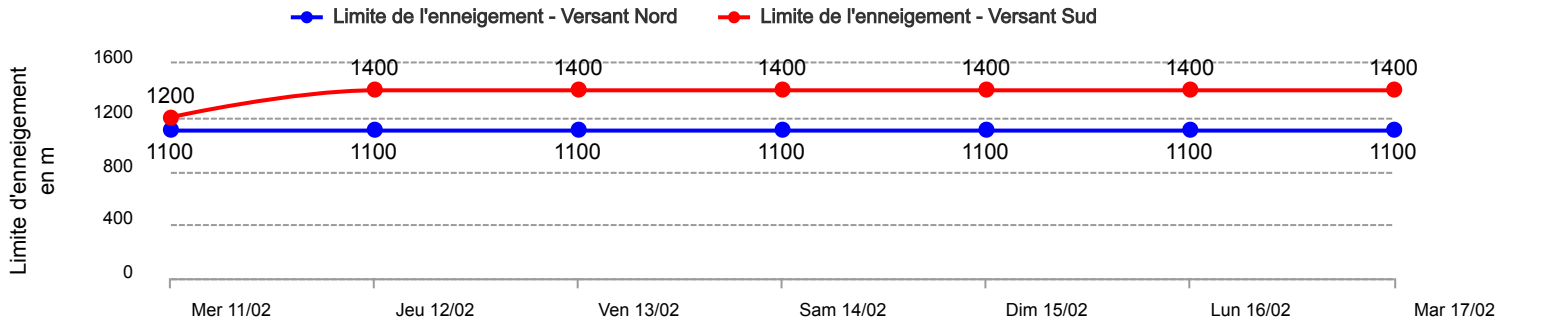

Pour consulter la vigilance en cours, veuillez vous rendre sur le site https://vigilance.meteofrance.fr/fr

Météo-France - 73 avenue de Paris, 94165 Saint-Mandé cedex - Contact : contact@meteo.fr

Bulletin neige & avalanches par téléphone au

0 892 68 10 20 Service 0,35 € / min + prix appel

Rédigé par Météo-France avec la contribution des observateurs du réseau nivo-météorologiques. Partenariat : ANMSM (Maires de Stations de Montagne), DSF (Domaines Skiables de France), ADSP (Directeurs de Pistes et de la Sécurité des Stations de Sports d'Hiver) et autres acteurs de la montagne.