# Bulletin d'estimation du risque d'avalanche
(valable en dehors des pistes balisées et ouvertes)

# MASSIF : Pays-Basque

Rédigé le mardi 17 Février 2026 à 16h

## Estimation des risques pour le : MERCREDI 18 FÉVRIER

**PLAQUES INSTABLES PEU EPAISSES, NEIGE HUMIDE AU SOLEIL.**

2

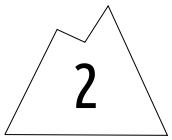


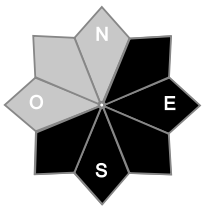


Indice de risque limité.

**Départs spontanés :** ponctuels en neige humide.

**Déclenchements provoqués :** plaques instables minces.

Indices de risque : 5 très fort - 4 fort - 3 marqué - 2 limité - 1 faible -- En noir : les pentes les plus dangereuses

## Stabilité du manteau neigeux

**Situation avalancheuse typique :** neige ventée neige humide

**Déclenchements provoqués** : **au-dessus de 1800/1900m** risque limité.
- dans un **large secteur nord-est/sud-est/sud-ouest**, avalanches de **plaques friables facilement déclenchables** par un seul skieur ou randonneur. Les chutes de neige faibles depuis lundi soir, sous le vent d'ouest à nord-ouest modéré, ont formé des plaques de **faibles épaisseurs**, en général **friables et peu identifiables, sensibles à une faible sollicitation**. Le pratiquant peut ainsi déclencher des avalanches de **taille 2, très localement taille 3 dans les zones restreintes d'accumulations en secteur est à sud-est**.
- dans les **autres secteurs**, plus exposés au vent, les plaques sont un peu **plus minces, légèrement plus dures et mais plus facilement identifiables**, elles-aussi sensibles à de **faibles sollicitations** et susceptibles de **propager facilement une cassure**. Au vu de l'épaisseur de neige mobilisable, avalanches de **taille 1 à parfois 2** possiblement déclenchables sous les skis, pieds ou raquettes.

**En dessous de 1800/1900m**, risque **faible**, surtout l'**après-midi dans les versants sud-est à sud-ouest doux et ensoleillés**, pour un skieur ou randonneur de déclencher une **petite avalanche de neige humide en pente raide**.

**Départs spontanés** : en **neige humide** et en **pentes raides** est à sud et sud-ouest qui **prennent le soleil**. Coulée ou petite avalanche le matin, petite à quelques fois moyenne en plein après-midi en sud à sud-ouest sous le soleil en partant des quelques accumulations encore en place au plus haut du massif.

## Qualité de la neige

**Enneigement** : toujours en léger retrait, les chutes de neige de mardi ayant été faibles. Crêtes, cols et sommets en expositions ouest souvent pelés ou à présent en glace. Manteau neigeux débutant vers 1200m, encore assez épais entre 1500 et 1800m en zones déventées.
**Limites skiables** : à partir de 1300 à 1500m respectivement en nord et sud.
**État de la neige** : manteau neigeux humidifié, tassé et plus ou moins regelé selon l'altitude, recouvert de quelques centimètres de neige fraîche et sèche au petit matin, frittée à cartonnée dans les pentes ouest à nord. Le temps doux et ensoleillé de la journée, ramollira les pentes sud, humidifiera les pentes ombragées sous 1800m, la neige de ces mêmes pentes restera en l'état au-dessus de 1800m.

## Aperçu météo pour le mercredi 18 février

| nuit | matin | après-midi | soir |
|---|---|---|---|
| | | | |
| Temps sec, beau en journée, venté de sud-ouest à sud d'ouest à nord-ouest soutenu la nuit suivante. | | l'après-midi, dégradation neigeuse et vent | |

| | | | | |
|---|---|---|---|---|
| **Pluie-Neige** | | | 1 900 m | 1 100 m |
| **Iso 0 °C** | 2 400 m | 2 600 m | 2 200 m | 1 400 m |
| **Vent 1000 m** | ↑ 20 km/h | ↑ 30 km/h | ↑ 50 km/h | → 35 km/h |
| **Vent 2000 m** | ↗ 45 km/h | ↗ 80 km/h | ↗ 110 km/h | → 90 km/h |

## Épaisseur de neige hors-piste

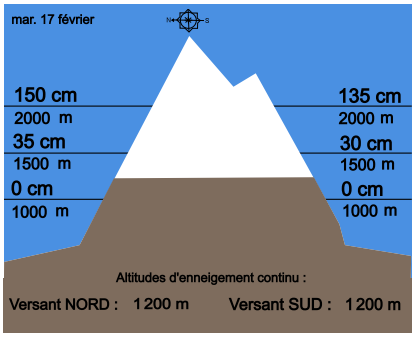


## Précipitations à 1800 m

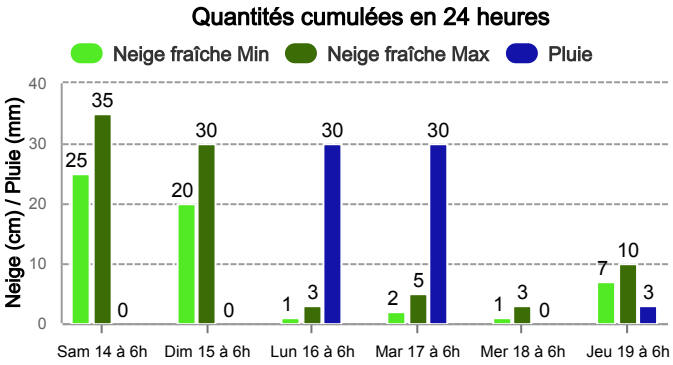


## Tendance du jeudi 19 février

3

**Indice de risque marqué**

Risque accidentel en hausse avec les chutes de neige ventées d'ouest à nord-ouest attendues.

Pour consulter la vigilance en cours, veuillez vous rendre sur le site https://vigilance.meteofrance.fr/fr

Météo-France - 73 avenue de Paris, 94165 Saint-Mandé cedex - Contact : contact@meteo.fr

Rédigé par Météo-France avec la contribution des observateurs du réseau nivo-météorologiques. Partenariat : ANMSM (Maires de Stations de Montagne), DSF (Domaines Skiables de France), ADSP (Directeurs de Pistes et de la Sécurité des Stations de Sports d'Hiver) et autres acteurs de la montagne.

Bulletin neige & avalanches par téléphone au 0 892 68 10 20 Service 0,35 € / min + prix appel

RÉPUBLIQUE FRANÇAISE
*Liberté Égalité Fraternité*

METEO FRANCE
À VOS CÔTÉS, DANS UN CLIMAT QUI CHANGE

# Bulletin d'estimation du risque d'avalanche

## (valable en dehors des pistes balisées et ouvertes)

# MASSIF : Pays-Basque

Rédigé le mardi 17 février 2026 à 16h

## Conditions nivo-météo des 7 derniers jours

| | mer. 11/02 | | | | jeu. 12/02 | | | | ven. 13/02 | | | | sam. 14/02 | | | | dim. 15/02 | | | | lun. 16/02 | | | | mar. 17/02 | | | |
|---|---|---|---|---|---|---|---|---|---|---|---|---|---|---|---|---|---|---|---|---|---|---|---|---|---|---|---|---|
| | 03h | 09h | 15h | 21h | 03h | 09h | 15h | 21h | 03h | 09h | 15h | 21h | 03h | 09h | 15h | 21h | 03h | 09h | 15h | 21h | 03h | 09h | 15h | 21h | 03h | 09h | 15h | 21h |
| Météo | | | | | | | | | | | | | | | | | | | | | | | | | | | | |
| Vent (km/h) | 70 | 80 | 100 | 120 | 120 | 110 | 80 | 75 | 110 | 110 | 85 | 90 | 100 | 75 | 80 | 60 | 40 | 70 | 80 | 85 | 80 | 80 | 70 | 75 | 85 | 50 | 60 | 40 |
| à 2000m | ↗ | ↗ | ↗ | ↗ | ↗ | → | ↘ | ↗ | ↑ | ↑ | → | ↘ | ↓ | ↓ | ↘ | ↓ | ↘ | ↘ | ↘ | ↘ | ↘ | ↘ | ↘ | ↘ | ↘ | → | ↘ | → |
| Vent (km/h) | 40 | 50 | 70 | 80 | 80 | 70 | 40 | 35 | 50 | 65 | 55 | 55 | 60 | 40 | 45 | 25 | 15 | 15 | 20 | 25 | 35 | 35 | 30 | 35 | 25 | 15 | 20 | 10 |
| à 1000m | → | ↑ | ↑ | ↗ | ↗ | → | ↘ | ↗ | ↗ | ↑ | ↗ | ↘ | ↓ | ↓ | ↓ | ↓ | ↙ | ↘ | → | ↗ | ↗ | → | ↘ | ↓ | ↘ | ↘ | ↓ | ↑ |

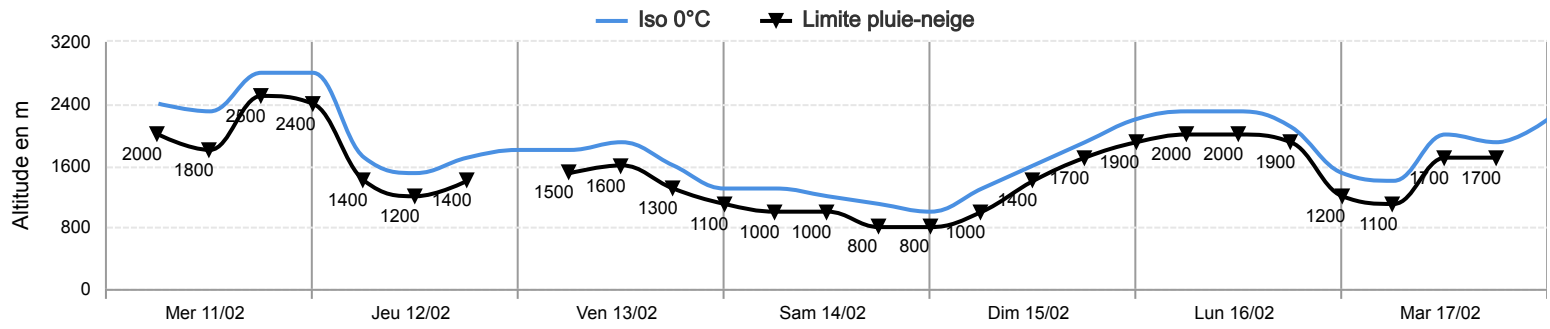


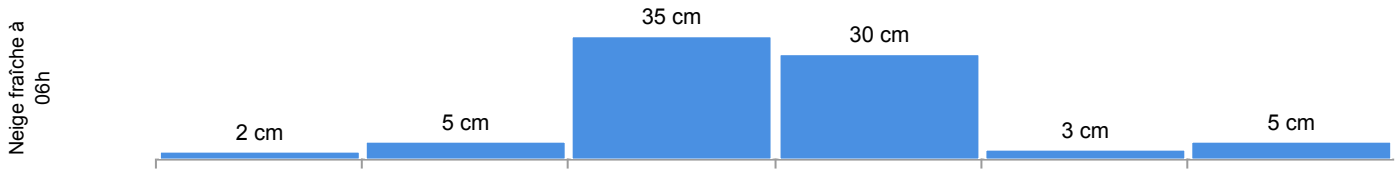


| Risque d'avalanche | mer. 11/02 | jeu. 12/02 | ven. 13/02 | sam. 14/02 | dim. 15/02 | lun. 16/02 | mar. 17/02 |
|---|---|---|---|---|---|---|---|
| | 3 | 2 | 2 | 3 | 3 | 3 | 3 |

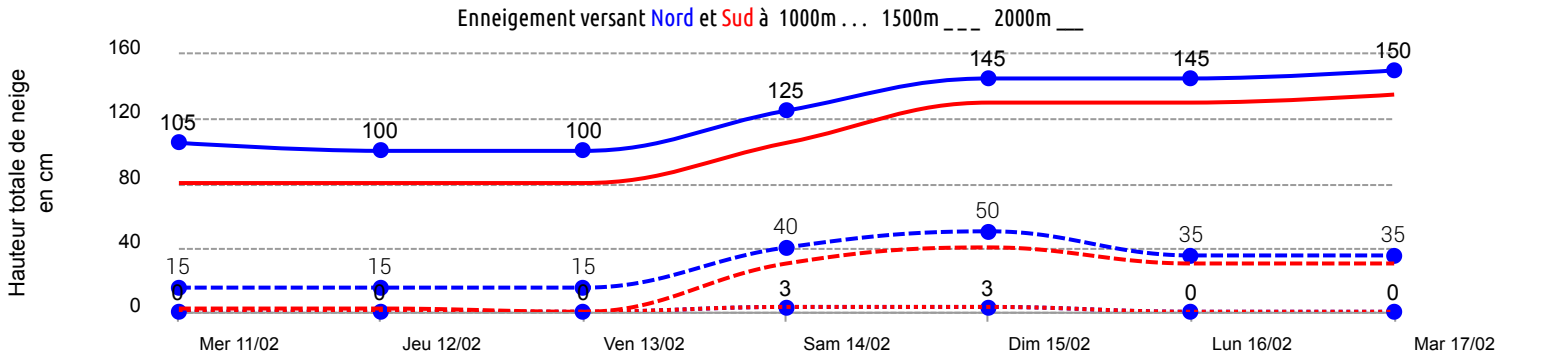


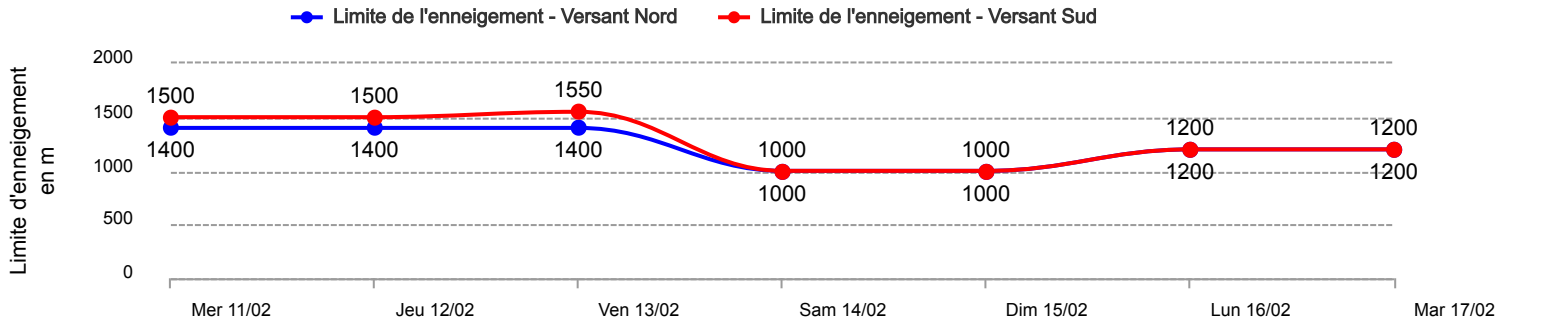


Pour consulter la vigilance en cours, veuillez vous rendre sur le site https://vigilance.meteofrance.fr/fr


Météo-France - 73 avenue de Paris, 94165 Saint-Mandé cedex - Contact : contact@meteo.fr


Bulletin neige & avalanches par téléphone au **0 892 68 10 20** Service 0,35 € / min + prix appel


Rédigé par Météo-France avec la contribution des observateurs du réseau nivo-météorologiques. Partenariat : ANMSM (Maires de Stations de Montagne), DSF (Domaines Skiables de France), ADSP (Directeurs de Pistes et de la Sécurité des Stations de Sports d'Hiver) et autres acteurs de la montagne.