Bulletin d'estimation du risque d'avalanche

(valable en dehors des pistes balisées et ouvertes)

MASSIF : Cerdagne Canigou

Rédigé le mardi 17 Février 2026 à 17h

Estimation des risques pour le : MERCREDI 18 FÉVRIER

PERSISTANCE DE STRUCTURES DE PLAQUES EN ALTITUDE

3

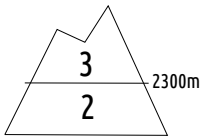

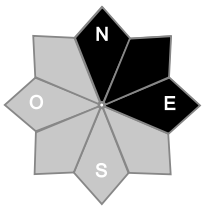

Au-dessus de 2300m indice de risque marqué, plus bas indice limité.

Départs spontanés : Possibles avalanches de fond à basse altitude

Déclenchements provoqués : Plaques à vent en altitude en cours de stabilisation

Indices de risque : 5 très fort - 4 fort - 3 marqué - 2 limité - 1 faible -- En noir : les pentes les plus dangereuses

Stabilité du manteau neigeux

Situation avalancheuse typique : neige ventée

Déclenchements provoqués :
En altitude, au-dessus de 2200 à 2400m en général, des structures de plaques souvent dures, mais parfois friables, se sont formées ces derniers jours sous le vent de nord-ouest. Des accumulations de l'ordre de 30 à 50 cm peuvent céder au passage d'un skieur. Elles sont surtout présentes dans un large secteur nord à est et pourront conduire à des avalanches de moyenne taille (T2).
Observables : zone d'accumulations dures sous le vent, neige travaillée par le vent en surface.

Départs spontanés :Peu probables.
En dessous de 1800m environ, à la faveur du redoux, des avalanches de fond peuvent encore se produire plutôt dans les pentes raides. Elles pourront générer des avalanches de taille petite à moyenne (taille 1 à 2).
Observables : Large fissure d'apparition récente en pentes herbeuses / dalles rocheuses.

Qualité de la neige

Enneigement :
L'enneigement reste largement supérieur à celui des cinq dernières années et se situe à niveau remarquable par rapport aux statistiques plus anciennes. L'enneigement débute vers 1500m et devient rapidement conséquent avec l'altitude. La barre des 2m de neige est souvent atteinte dès 2000m d'altitude.

État de la neige :
Sous 2200m, on trouvera des conditions de neige de printemps.
À partir de 2200m, on pourra trouver une neige poudreuse dans les vallons et secteurs abrités du vent, une neige travaillée par le vent ailleurs. Les crêtes et sommets peuvent se retrouver décapés par le vent violent.

Aperçu météo pour le mercredi 18 février

	nuit	matin	après-midi	soir

Redoux et retour du soleil ce mercredi

Pluie-Neige				
Iso 0 °C	2 300 m	2 900 m	3 100 m	2 600 m
Vent 2000 m	30 km/h	25 km/h	35 km/h	50 km/h
Vent 3000 m	65 km/h	55 km/h	70 km/h	80 km/h

Épaisseur de neige hors-piste

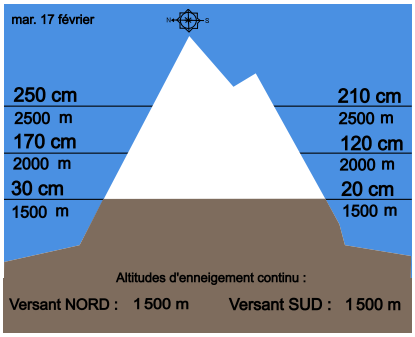

Précipitations à 1800 m

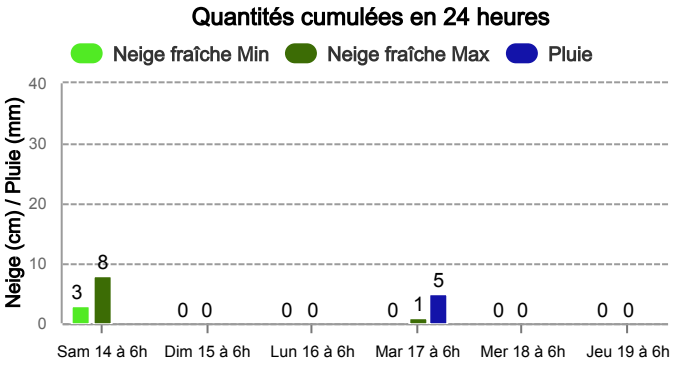

Tendance du jeudi 19 février

3 **Indice de risque marqué**

Niveau de risque a priori maintenu jeudi par un nouvel épisode de transport de neige par le vent, et les quelques chutes de neige attendues

Pour consulter la vigilance en cours, veuillez vous rendre sur le site https://vigilance.meteofrance.fr/fr

Météo-France - 73 avenue de Paris, 94165 Saint-Mandé cedex - Contact : contact@meteo.fr

Rédigé par Météo-France avec la contribution des observateurs du réseau nivo-météorologiques. Partenariat : ANMSM (Maires de Stations de Montagne), DSF (Domaines Skiables de France), ADSP (Directeurs de Pistes et de la Sécurité des Stations de Sports d'Hiver) et autres acteurs de la montagne.

Bulletin neige & avalanches par téléphone au
0 892 68 10 20 Service 0,35 € / min + prix appel

RÉPUBLIQUE FRANÇAISE
Liberté Égalité Fraternité

METEO FRANCE
À VOS CÔTÉS, DANS UN CLIMAT QUI CHANGE

Bulletin d'estimation du risque d'avalanche
(valable en dehors des pistes balisées et ouvertes)
MASSIF : Cerdagne Canigou

Rédigé le mardi 17 février 2026 à 17h

Conditions nivo-météo des 7 derniers jours

	mer. 11/02				jeu. 12/02				ven. 13/02				sam. 14/02				dim. 15/02				lun. 16/02				mar. 17/02			
	03h	09h	15h	21h	03h	09h	15h	21h	03h	09h	15h	21h	03h	09h	15h	21h	03h	09h	15h	21h	03h	09h	15h	21h	03h	09h	15h	21h
Météo																												
Vent (km/h)	75	75	60	70	90	120	115	80	75	85	60	90	90	90	100	100	95	60	65	65	95	100	105	120	120	110	90	75
à 3000m																												
Vent (km/h)	45	45	35	50	65	90	90	55	45	50	35	60	70	70	80	80	60	40	35	40	50	65	80	85	85	65	50	40
à 2000m																												

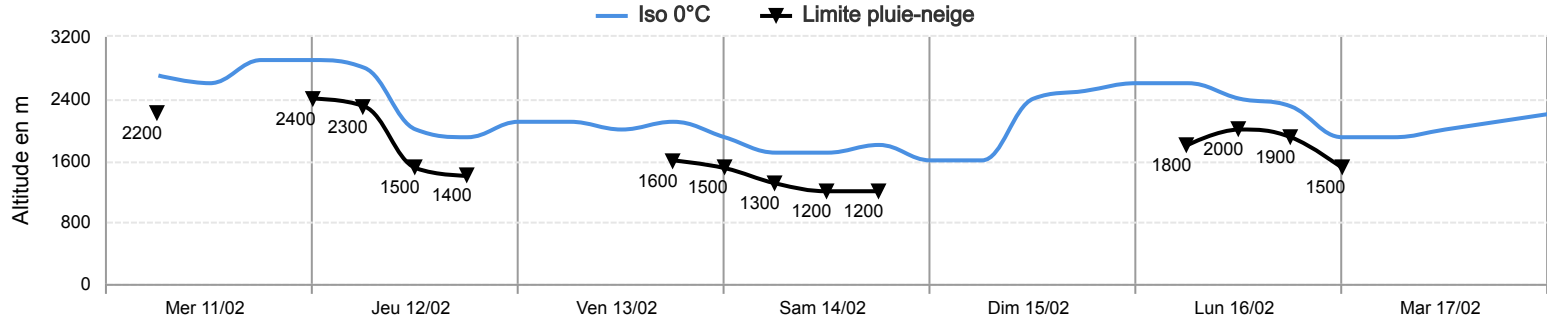

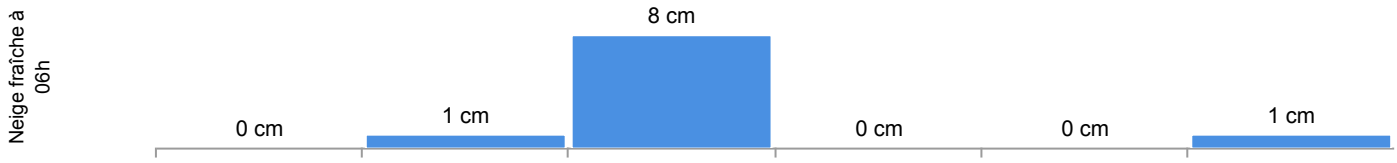

Risque d'avalanche	mer. 11/02	jeu. 12/02	ven. 13/02	sam. 14/02	dim. 15/02	lun. 16/02	mar. 17/02
	3	2	2	2	3	3	3

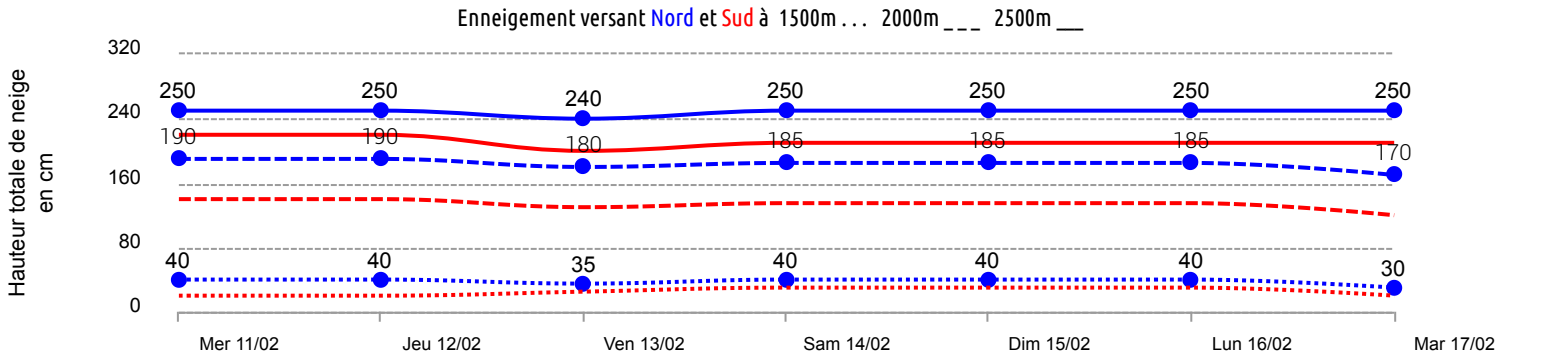

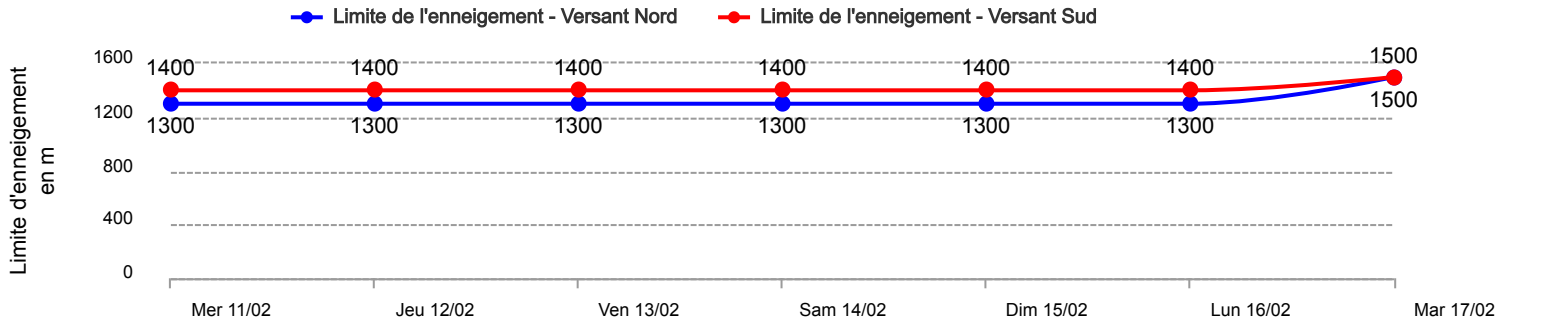

Pour consulter la vigilance en cours, veuillez vous rendre sur le site https://vigilance.meteofrance.fr/fr

Météo-France - 73 avenue de Paris, 94165 Saint-Mandé cedex - Contact : contact@meteo.fr

Rédigé par Météo-France avec la contribution des observateurs du réseau nivo-météorologiques. Partenariat : ANMSM (Maires de Stations de Montagne), DSF (Domaines Skiables de France), ADSP (Directeurs de Pistes et de la Sécurité des Stations de Sports d'Hiver) et autres acteurs de la montagne.

Bulletin neige & avalanches par téléphone au
0 892 68 10 20 Service 0,35 € / min + prix appel