Bulletin d'estimation du risque d'avalanche

(valable en dehors des pistes balisées et ouvertes)

MASSIF : Cinto Rotondo

Rédigé le mardi 17 Février 2026 à 17h

Estimation des risques pour le : MERCREDI 18 FÉVRIER

NOUVELLES STRUCTURES DE PLAQUES DANS LA NEIGE RÉCENTE

3

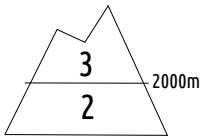

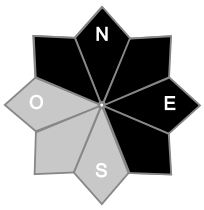

Au-dessus de 2000m indice de risque marqué, plus bas indice limité.

Départs spontanés : Coulées et avalanches en neige récente

Déclenchements provoqués : Plaques à vent présentes en toutes orientations

Indices de risque : 5 très fort - 4 fort - 3 marqué - 2 limité - 1 faible -- En noir : les pentes les plus dangereuses

Stabilité du manteau neigeux

Situation avalancheuse typique : neige ventée

Déclenchements provoqués : au-dessus de 1800 à 2000 m, le manteau neigeux demeure instable. Le vent d'Ouest accompagnant les dernières chutes de neige a pu générer de nombreuses structures de plaques dans la neige récente parfois loin des crêtes. Ces plaques se situent en plus grand nombre dans les secteurs orientés à l'Est mais peuvent persister dans toutes les orientations de pentes. Elles sont par endroits dures à cause du vent fort, par endroits friables plus à l'abri du vent. Elles sont parfois difficilement identifiables en gardant un aspect poudreux ou en étant recouvertes d'une couche de neige fraîche. Reposant souvent sur une couche de neige récente plus légère faisant office de sous-couche fragile, ces plaques sont faciles à déclencher à l'abri des vents d'Ouest à Nord-Ouest, plus difficilement déclenchables dans les secteurs exposés au vent. Elles pourraient générer des avalanches de taille petite à moyenne (taille 1 à 2). Une grande avalanche (taille 3) n'est pas à exclure, notamment dans une zone de forte accumulation par le vent ou en cas de déstabilisation de "vieilles" plaques plus épaisses, présentes en orientations Nord et Est, au-dessus de 2000 m.

Départs spontanés : des coulées et avalanches de neige récente sont attendues dans les pentes exposées au soleil en journée de mercredi mais également par surcharge due au transport par le vent. Compte tenu des volumes de neige récente mobilisable, on pourrait attendre de grandes avalanches (taille 3) partant des accumulations constituées à l'abri des vents d'Ouest à Nord, plutôt des avalanches de taille 1 à 2 dans les autres secteurs.

Autres : Risque de glissade en neige dure ou glacée aux abords des crêtes et sommets balayés par les vents.

Qualité de la neige

Qualification de l'enneigement : L'enneigement est excellent pour la saison à toutes altitudes. On relève plus de 2 mètres dans les combes abritées.
Limite d'enneigement skiable : 1300 à 1500 m selon le versant.
État de la neige : On trouve en surface une couche de neige fraîche de plus en plus significative en montant mais le vent d'Ouest à Nord-ouest soutenu rend l'enneigement très hétérogène : les orientations Nord et Est sont souvent plus garnies que les pentes Ouest rapidement pelées ou verglacées dès que l'on se rapproche des crêtes et sommets. La neige est froide et poudreuse à l'abri du vent dès 1800 à 2000 m d'altitude, elle devient plus compacte, voire cartonnée dans les secteurs ventés. On trouve localement des accumulations de neige roulée. Corniches et accumulations parfois volumineuses sont en place.

Aperçu météo pour le mercredi 18 février

	nuit	matin	après-midi	soir
	Temps sec et ensoleillé malgré un ciel voilé se densifiant au fil des heures et annonçant l'arrivée d'une nouvelle perturbation			
Pluie-Neige	1 100 m	1 400 m		
Iso 0 °C	2 100 m	2 400 m	2 500 m	2 600 m
Vent 1500 m	→ 45 km/h	↗ 50 km/h	↗ 40 km/h	↗ 40 km/h
Vent 3000 m	↗ 60 km/h	↗ 65 km/h	→ 55 km/h	↗ 50 km/h

Épaisseur de neige hors-piste

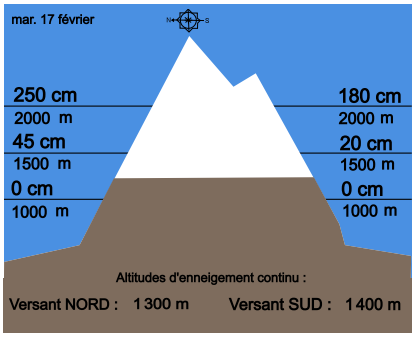

Précipitations à 1800 m

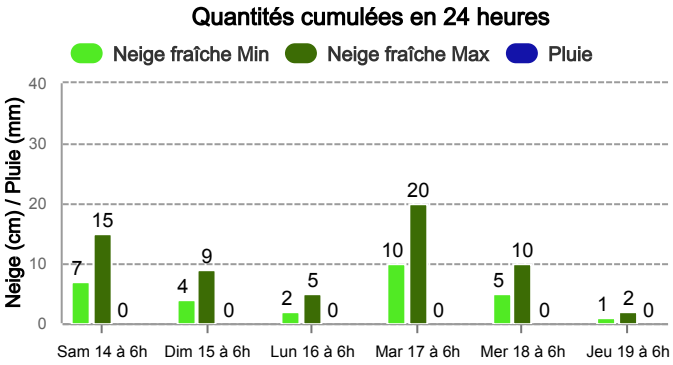

Tendance du jeudi 19 février

3 **Indice de risque marqué**

Temps perturbé surtout en versants occidentaux. Maintien au minimum d'un risque marqué de niveau 3 sur 5 sur le massif Cinto-Rotondo.

Pour consulter la vigilance en cours, veuillez vous rendre sur le site https://vigilance.meteofrance.fr/fr

Météo-France - 73 avenue de Paris, 94165 Saint-Mandé cedex - Contact : contact@meteo.fr

Rédigé par Météo-France avec la contribution des observateurs du réseau nivo-météorologiques. Partenariat : ANMSM (Maires de Stations de Montagne), DSF (Domaines Skiables de France), ADSP (Directeurs de Pistes et de la Sécurité des Stations de Sports d'Hiver) et autres acteurs de la montagne.

Bulletin neige & avalanches par téléphone au **0 892 68 10 20** Service 0,35 € / min + prix appel

Bulletin d'estimation du risque d'avalanche

(valable en dehors des pistes balisées et ouvertes)

MASSIF : Cinto Rotondo

Rédigé le mardi 17 février 2026 à 17h

Conditions nivo-météo des 7 derniers jours

	mer. 11/02				jeu. 12/02				ven. 13/02				sam. 14/02				dim. 15/02				lun. 16/02				mar. 17/02			
	03h	09h	15h	21h	03h	09h	15h	21h	03h	09h	15h	21h	03h	09h	15h	21h	03h	09h	15h	21h	03h	09h	15h	21h	03h	09h	15h	21h
Météo																												
Vent (km/h)	80	100	100	90	80	120	100	100	60	55	35	70	50	20	50	50	40	70	50	50	80	90	120	130	100	80	70	60
à 3000m																												
Vent (km/h)	50	90	90	90	70	80	80	70	50	40	20	40	30	15	30	30	20	30	30	40	70	70	90	90	80	50	50	40
à 1500m																												

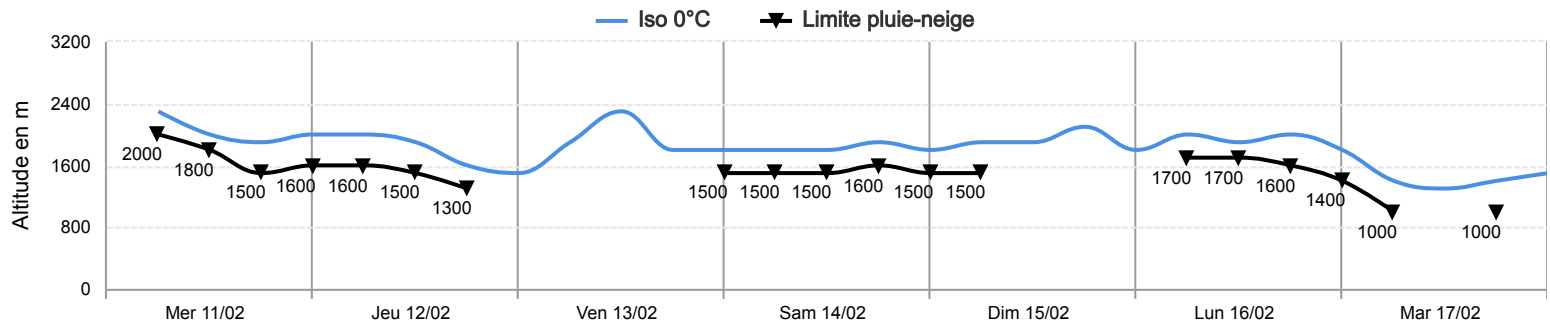

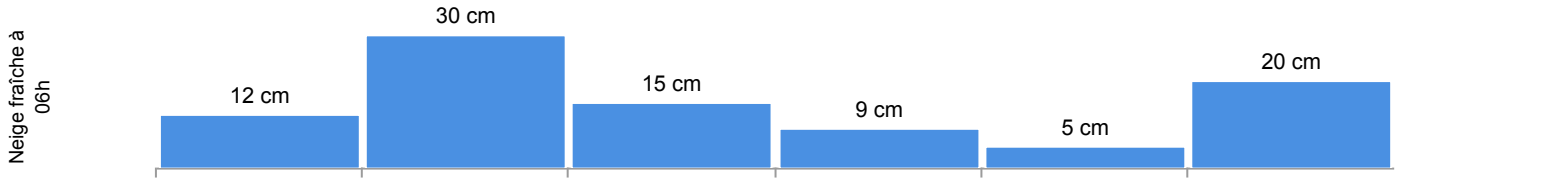

Risque d'avalanche	mer. 11/02	jeu. 12/02	ven. 13/02	sam. 14/02	dim. 15/02	lun. 16/02	mar. 17/02
	3	4	3	3	2	3	3

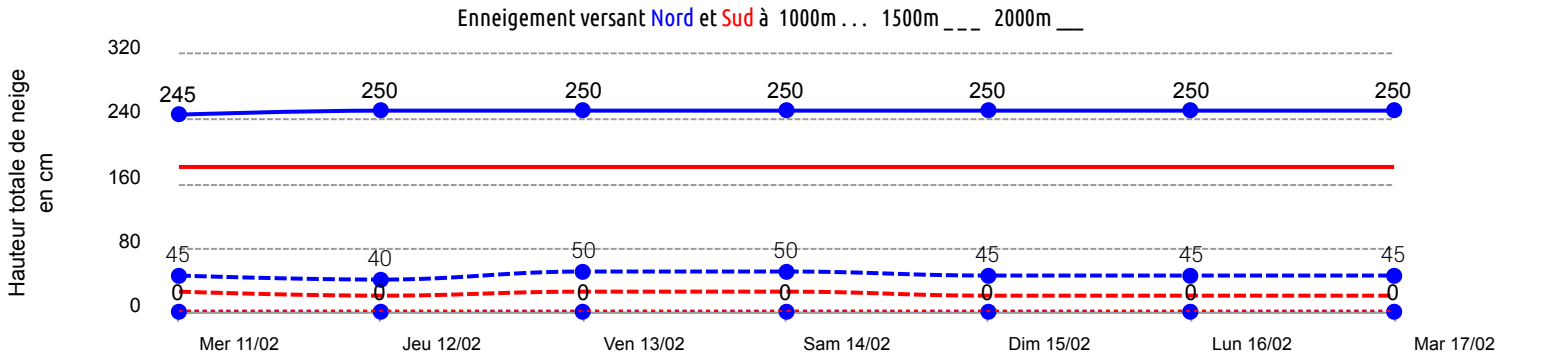

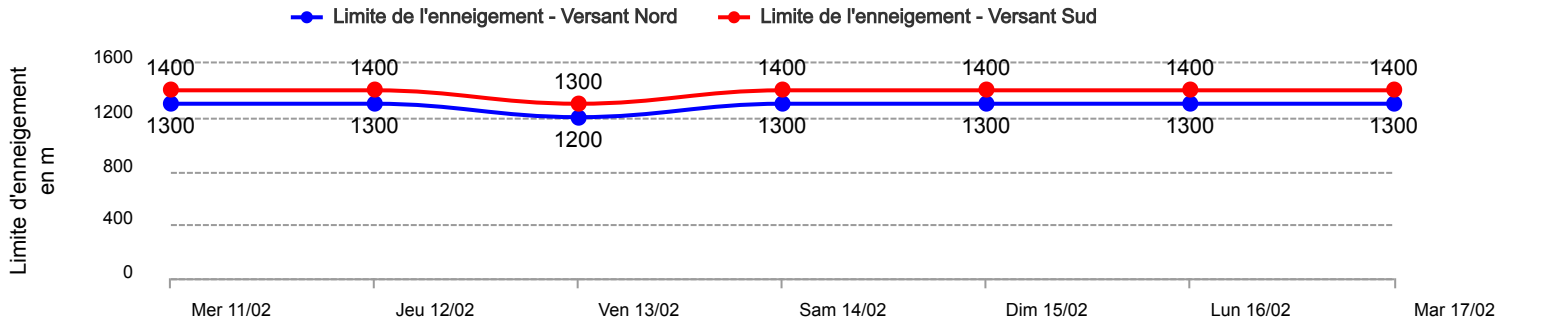

Pour consulter la vigilance en cours, veuillez vous rendre sur le site https://vigilance.meteofrance.fr/fr

Météo-France - 73 avenue de Paris, 94165 Saint-Mandé cedex - Contact : contact@meteo.fr

Rédigé par Météo-France avec la contribution des observateurs du réseau nivo-météorologiques. Partenariat : ANMSM (Maires de Stations de Montagne), DSF (Domaines Skiables de France), ADSP (Directeurs de Pistes et de la Sécurité des Stations de Sports d'Hiver) et autres acteurs de la montagne.

Bulletin neige & avalanches par téléphone au

0 892 68 10 20 Service 0,35 € / min + prix appel