RÉPUBLIQUE FRANÇAISE
Liberté Égalité Fraternité

METEO FRANCE
À VOS CÔTÉS, DANS UN CLIMAT QUI CHANGE

Bulletin d'estimation du risque d'avalanche
(valable en dehors des pistes balisées et ouvertes)
MASSIF : Haute-Ariege

Rédigé le mardi 17 Février 2026 à 17h

Estimation des risques pour le : MERCREDI 18 FÉVRIER

AU-DESSUS DE 2200M, RISQUE MARQUÉ DE DÉCLENCHEMENTS PROVOQUÉS DANS LA NEIGE RÉCENTE

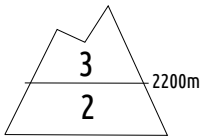

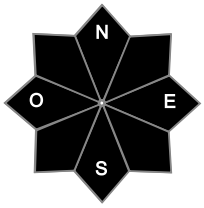

Au-dessus de 2200m indice de risque marqué, plus bas indice limité.

Départs spontanés : Départs ponctuels en neige humide

Déclenchements provoqués : Encore des instabilités temporaires dans la neige récente ventée en altitude, cassures importantes avec propagation

Indices de risque : 5 très fort - 4 fort - 3 marqué - 2 limité - 1 faible -- En noir : les pentes les plus dangereuses

Stabilité du manteau neigeux

Situation avalancheuse typique : neige ventée neige humide

Déclenchements provoqués :
* Au-dessus de 2200m, dans les pentes où le manteau neigeux est resté froid et sec, de nombreuses plaques friables se sont formées au cours de ces derniers jours. Elles sont en cours de stabilisation, mais sont encore déclenchables au passage d'un simple skieur ou randonneur. Les avalanches de taille 2 à 3 peuvent présenter des cassures importantes jusqu'à 70 cm, voire 1m dans les pentes d'un large secteur sud-est à nord, favorables aux accumulations. Ces plaques y sont d'un aspect friable et sont difficilement détectables. Dans les autres orientations au vent d'ouest à nord-ouest, le travail du vent a rendu les plaques plus dures et plus facilement identifiables.
Observables : quantité de neige fraiche critique (>50 cm), fissures sous les skis, "Whoumf", couverture de neige hétérogène en surface, corniches.
* En dessous de 2000/2200m, on pourra trouver des quantités variables de neige encore légère en surface mais reposant sur un manteau neigeux plus ou moins humidifié, ce qui limitera l'ampleur d'un éventuel déclenchement. Des coulées pouvant déstabiliser un pratiquant, et seulement dans de rares cas des avalanches de taille moyenne, sont possibles.

Départs spontanés :
* Au-dessus de 2000/2200m, dans les secteurs ensoleillés, des départs ponctuels en neige humide d'avalanches de taille 2 sont attendus au fil de la course du soleil, par humidification de la couche de neige tombée depuis samedi.
* Sous 1800/2000m le manteau neigeux est fortement humidifié même si en surface on pourra trouver un peu de neige fraîche. La reprise de l'humidification par le radoucissement et l'ensoleillement pourra conduire à des départs en surface voire à de rares avalanches de fond.

Qualité de la neige

Enneigement :
Malgré l'épisode de fonte de lundi, l'enneigement reste largement supérieur à celui des cinq dernières années et se situe à un très bon niveau par rapport aux statistiques plus anciennes. L'enneigement débute vers 1300m et devient conséquent dès 1500m. La barre des 2m de neige est souvent atteinte dès 2000m d'altitude.

Qualité de la neige :
Sous 2000/2200m, on pourra trouver par endroits un peu de neige fraîche plus ou moins humidifiée. Cette neige repose sur un manteau généralement fortement humidifié.
En altitude, dans les pentes à l'ombre, on trouve une neige poudreuse dans les vallons et secteurs abrités du vent, une neige travaillée par le vent ailleurs. Dans les versants ensoleillés, l'humidification opère jusque très haut. Les crêtes et sommets peuvent se retrouver décapés par le vent violent.

Aperçu météo pour le mercredi 18 février

	nuit	matin	après-midi	soir

Redoux et retour du soleil ce mercredi, avant l'arrivée d'une nouvelle perturbation en soirée

Pluie-Neige				1 500 m
Iso 0 °C	2 100 m	2 700 m	2 800 m	1 900 m
Vent 2000 m	↗ 15 km/h	↗ 25 km/h	↗ 70 km/h	→ 45 km/h
Vent 3000 m	↓ 40 km/h	↗ 55 km/h	↗ 65 km/h	↗ 65 km/h

Pour consulter la vigilance en cours, veuillez vous rendre sur le site https://vigilance.meteofrance.fr/fr

Météo-France - 73 avenue de Paris, 94165 Saint-Mandé cedex - Contact : contact@meteo.fr

Rédigé par Météo-France avec la contribution des observateurs du réseau nivo-météorologiques. Partenariat : ANMSM (Maires de Stations de Montagne), DSF (Domaines Skiables de France), ADSP (Directeurs de Pistes et de la Sécurité des Stations de Sports d'Hiver) et autres acteurs de la montagne.

Bulletin neige & avalanches par téléphone au
0 892 68 10 20 Service 0,35 € / min + prix appel

Bulletin d'estimation du risque d'avalanche

(valable en dehors des pistes balisées et ouvertes)

MASSIF : Haute-Ariege

Rédigé le mardi 17 février 2026 à 17h

Épaisseur de neige hors-piste

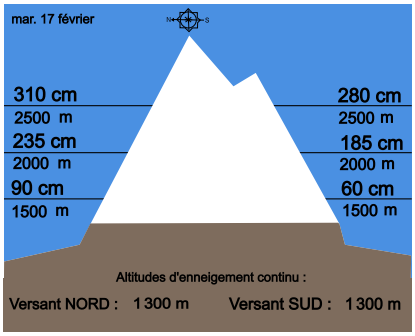

Précipitations à 1800 m

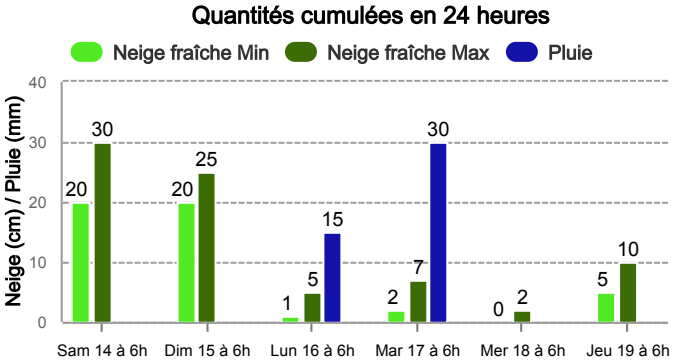

Tendance du jeudi 19 février

Indice de risque marqué

Le risque avalancheux restera au moins marqué jeudi avec le nouvel apport neigeux venté dans la nuit de mercredi à jeudi qui perdurera en journée de jeudi.

Pour consulter la vigilance en cours, veuillez vous rendre sur le site https://vigilance.meteofrance.fr/fr

Météo-France - 73 avenue de Paris, 94165 Saint-Mandé cedex - Contact : contact@meteo.fr

Rédigé par Météo-France avec la contribution des observateurs du réseau nivo-météorologiques. Partenariat : ANMSM (Maires de Stations de Montagne), DSF (Domaines Skiables de France), ADSP (Directeurs de Pistes et de la Sécurité des Stations de Sports d'Hiver) et autres acteurs de la montagne.

Bulletin neige & avalanches par téléphone au

0 892 68 10 20 Service 0,35 € / min + prix appel

RÉPUBLIQUE FRANÇAISE
Liberté Égalité Fraternité

METEO FRANCE
À VOS CÔTÉS, DANS UN CLIMAT QUI CHANGE

Bulletin d'estimation du risque d'avalanche

(valable en dehors des pistes balisées et ouvertes)

MASSIF : Haute-Ariege

Rédigé le mardi 17 février 2026 à 17h

Conditions nivo-météo des 7 derniers jours

	mer. 11/02				jeu. 12/02				ven. 13/02				sam. 14/02				dim. 15/02				lun. 16/02				mar. 17/02			
	03h	09h	15h	21h	03h	09h	15h	21h	03h	09h	15h	21h	03h	09h	15h	21h	03h	09h	15h	21h	03h	09h	15h	21h	03h	09h	15h	21h
Météo																												
Vent (km/h)	65	50	60	80	90	100	100	75	65	75	65	85	90	90	90	80	90	60	50	50	65	75	80	90	90	75	50	40
à 3000m	↘	↘	↗	→	↘	↘	↘	↘	↘	↗	↗	↓	↘	↓	↓	↓	↓	↓	↓	↓	↓	↘	↘	↓	↘	↘	↘	↘
Vent (km/h)	45	35	35	45	60	75	75	50	45	65	40	65	70	65	70	60	55	35	30	35	40	60	70	75	70	45	35	25
à 2000m	↘	↘	↗	→	↘	↘	↘	↘	↗	↑	↓	↓	↘	↓	↓	↓	↓	↓	↘	↘	↘	↘	↘	↘	↓	↘	↘	↘

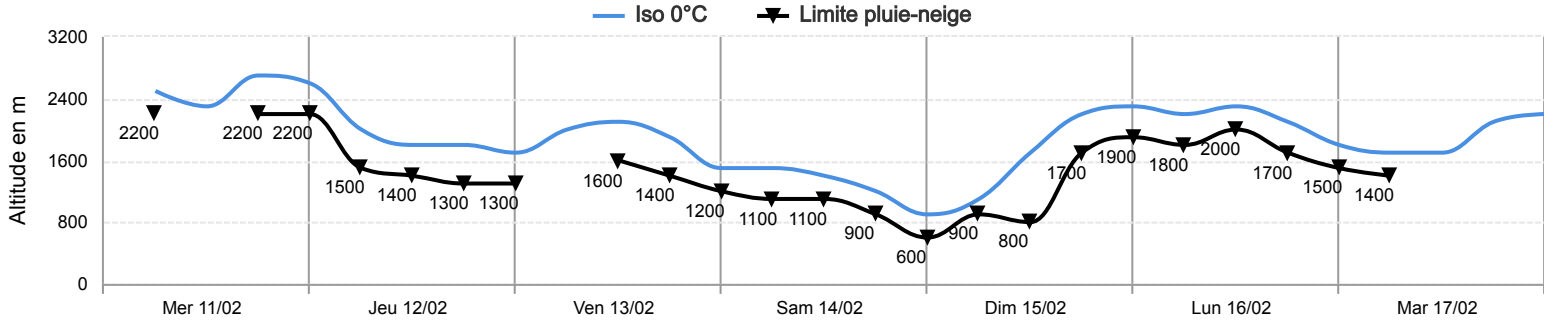

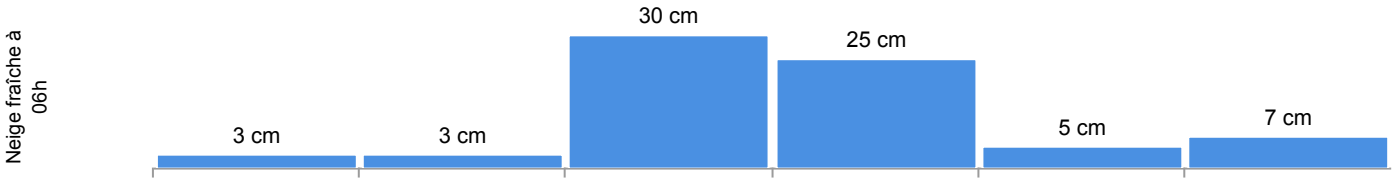

Risque d'avalanche	mer. 11/02	jeu. 12/02	ven. 13/02	sam. 14/02	dim. 15/02	lun. 16/02	mar. 17/02
	4	3	2	3	4	4	4

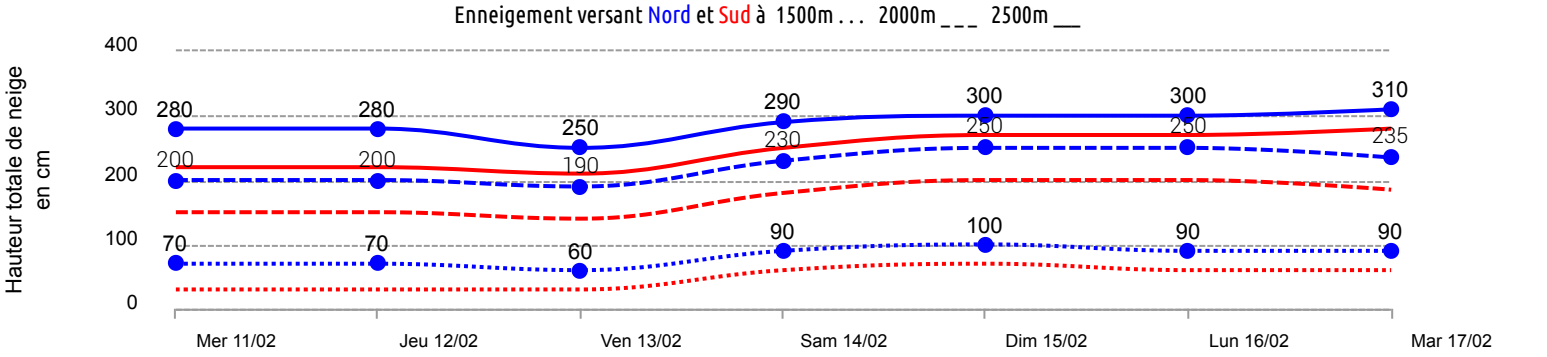

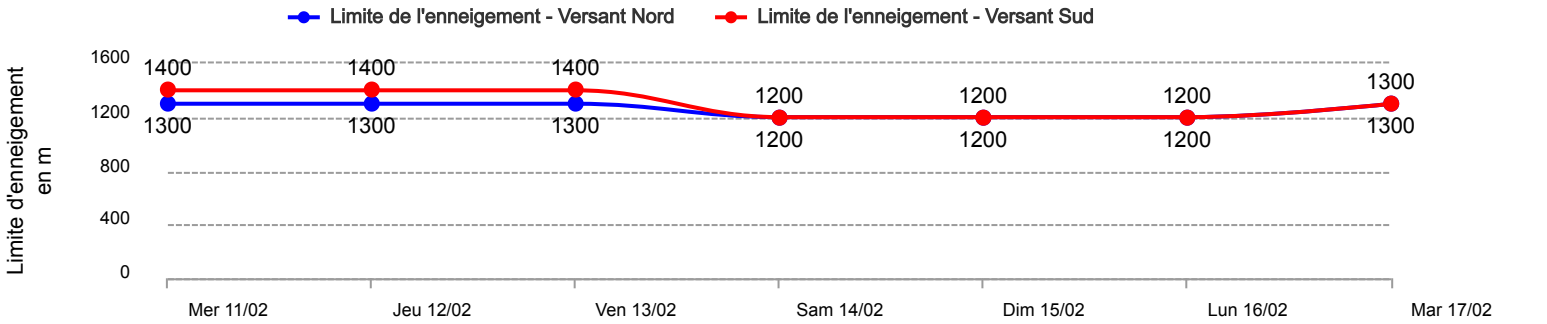

Pour consulter la vigilance en cours, veuillez vous rendre sur le site https://vigilance.meteofrance.fr/fr

Météo-France - 73 avenue de Paris, 94165 Saint-Mandé cedex - Contact : contact@meteo.fr

Bulletin neige & avalanches par téléphone au

0 892 68 10 20 Service 0,35 € / min + prix appel

Rédigé par Météo-France avec la contribution des observateurs du réseau nivo-météorologiques. Partenariat : ANMSM (Maires de Stations de Montagne), DSF (Domaines Skiables de France), ADSP (Directeurs de Pistes et de la Sécurité des Stations de Sports d'Hiver) et autres acteurs de la montagne.