GOBIERNO DE ESPAÑA
VICEPRESIDENCIA TERCERA DEL GOBIERNO
MINISTERIO PARA LA TRANSICIÓN ECOLÓGICA Y EL RETO DEMOGRÁFICO

Boletín de información nivológica y de peligro de aludes

Pirineo Catalán

aemet Agencia Estatal de Meteorología

miércoles, 18 de febrero de 2026

Pronóstico hasta las 24 horas del jueves, día 19 de febrero

(Válido fuera de pistas de esquí balizadas y abiertas)

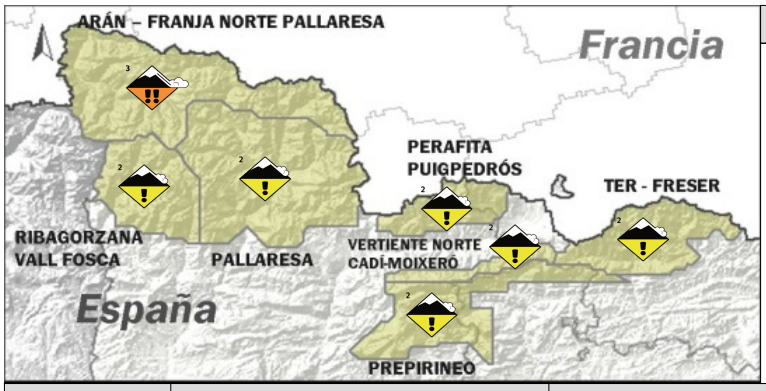

Problemas de aludes

Placas de viento

Nieve reciente

Macizo	Peligro	Problemas de aludes, cota, orientación, tamaño	Innivación observada (m)
Arán - Franja norte Pallaresa	3 / 3 / 2 / 2100 Notable	Placas de viento: 2100; N E S O; 3 Nieve reciente: N E S O; 2	2026-02-18 N S Cotas bajas
Ribagorzana - Vall Fosca	2 / 2 Limitado	Placas de viento: 2100; N E S O; 2 Nieve reciente: N E S O; 2	2026-02-18 N S Cotas bajas
Pallaresa	2 / 2 Limitado	Placas de viento: 2100; N E S O; 2 Nieve reciente: N E S O; 2	2026-02-18 N S Cotas bajas

AEMET. Se autoriza la reproducción de su contenido citando la fuente.

Boletín de información nivológica y de peligro de aludes

Pirineo Catalán

Perafita - Puigpedrós	2 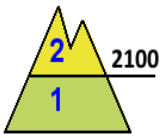 **Limitado**	**Placas de viento** **Nieve reciente** 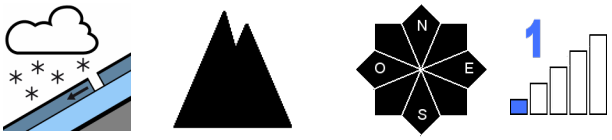	2026-02-18 Cotas bajas
Ter - Freser	2 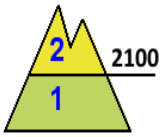 **Limitado**	**Placas de viento** 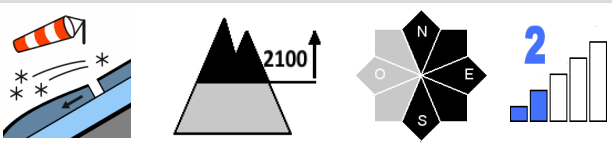 **Nieve reciente** 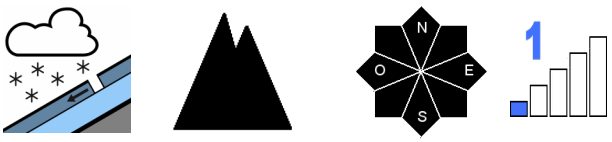	2026-02-18 Cotas bajas
Vertiente norte Cadí - Moixeró	2 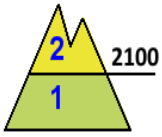 **Limitado**	**Placas de viento** 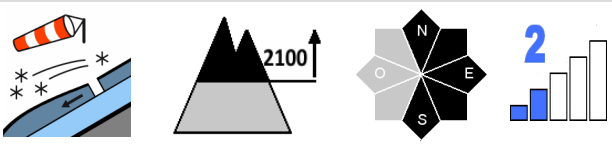 **Nieve reciente** 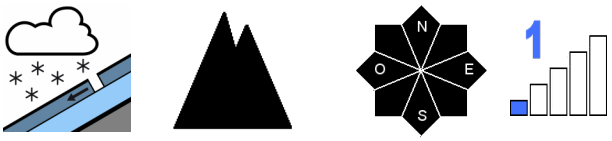	2026-02-18 Cotas bajas
Prepirineo	2 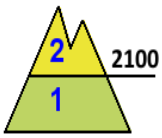 **Limitado**	**Placas de viento** 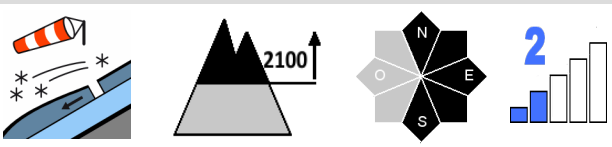 **Nieve reciente** 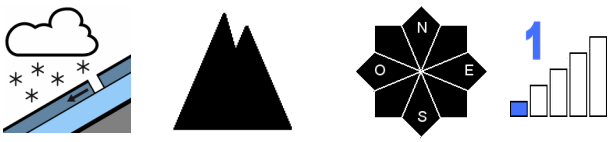	2026-02-18 Cotas bajas

Estado del manto y observaciones recientes

Pese a que en las últimas 24 h han menguado en torno a 5 cm los espesores medidos en la red de observación el manto es continuo desde cotas bajas, con espesores que en la mayor parte de la cordillera se encuentran en máximos, muy por encima de lo que cabría esperar a estas alturas de la temporada, superándose los 150 a 200 cm por encima de 2200 metros en numerosas áreas.

AEMET. Se autoriza la reproducción de su contenido citando la fuente.

Las cotas medias y bajas constan de un perfil bastante humedecido, en algunos sectores hasta la base, y con costra de rehielo en superficie. En cotas altas también se ha formado costra en muchos puntos, confiriéndole una importante estabilización. Más arriba, en la alta montaña, la nieve permanece más seca y muy venteada, con una distribución muy irregular a causa de los intensos vientos. Además, las antiguas capas débiles persistentes todavía pueden estar presentes en niveles subyacentes en las umbrías.

Evolución del manto y peligro de aludes para el jueves, día 19

Problema de placas de viento en cotas altas. Problema de nieve reciente.

Hoy a últimas horas y mañana jueves se esperan nevadas significativas en la vertiente norte del Pirineo de Lleida y el valle de Arán, con acumulaciones de 5-10 cm por encima de 1000-1100 m que en cotas altas podrán alcanzar los 15-20 cm.
Se podrán formar nuevas placas con los fuertes vientos del W y NW, principalmente por encima de los 2100 m, en un amplio sector E, bajo collados y cordales. Estas placas serán pequeñas por lo general, pero podrán ser reactivas y romper fácilmente al paso de una sola persona. Los aludes de placa que se puedan desencadenar serán pequeños si involucran la nevada reciente, o hasta tamaño mediano si afectan a niveles de manto viejo o placas antiguas. En laderas umbrías de cotas altas con poco espesor del Arán-Franja Norte Pallaresa su rotura es capaz de desencadenar aludes de tamaño grande.
En la alta montaña, habrá que extremar la precaución con las probables ventiscas, que podrán ser intensas.
En sectores resguardados o poco afectados por el viento, en vertientes propicias, son probables aludes de nieve reciente de pequeño tamaño, localmente mediano en las zonas de mayores acumulaciones. La probabilidad de aludes será mayor con el paso de las horas.

Predicción meteorológica para el jueves, día 19

Muy nuboso o cubierto, con visibilidad localmente reducida.
Precipitaciones débiles o moderadas, en ocasiones en forma de chubascos, más frecuentes en el Arán y norte de la Pallaresa, donde podrán ser localmente persistentes. Cota de nieve: fluctuante, entre 800 y 1300 metros aproximadamente.
Temperaturas mínimas en ligero o moderado descenso. Máximas en moderado descenso, localmente notable. Heladas débiles o moderadas, fuertes y persistentes en la alta montaña.
Viento fuerte del oeste y noroeste, con rachas muy fuertes, que en cotas altas y zonas expuestas podrán superar los 90 km/h.

Datos en la atmósfera libre:

Altitud de la isoterma de 0 ºC: 1600 m
Altitud de la isoterma de -10 ºC: 3200 m

Viento a 1500 m: W 40 km/h
Viento a 3000 m: NW 110 km/h

Evolución para el viernes día 20

Nivel de peligro en ligero descenso.

AEMET. Se autoriza la reproducción de su contenido citando la fuente.

Boletín de información nivológica y de peligro de aludes

Pirineo Catalán

Escala europea de peligro de aludes

Débil | Limitado | Notable | Fuerte | Muy Fuerte

Problemas de aludes

Nieve reciente | Placas de viento | Capas débiles persistentes | Nieve húmeda | Deslizamientos basales | Sin problema evidente

Nota1: Se recuerda que, siempre que haya nieve, la ausencia total de peligro no existe. Hay que tener presente que en circunstancias desfavorables, con aludes de tamaño 1 (alud pequeño o colada) y tamaño 2 (alud mediano), se pueden sufrir severos daños personales.

Nota2: Los BPA se elaboran en base a información meteorológica así como al estado del manto nivoso a través de sondeos puntuales. Se advierte a los usuarios de la variabilidad de esta información al extrapolarla a zonas extensas de montaña. Por ello, AEMET no se hace responsable de su uso para la toma de decisiones que conciernen a la seguridad personal, ni de los riesgos físicos o materiales de ellas derivadas.

AEMET. Se autoriza la reproducción de su contenido citando la fuente.