GOBIERNO DE ESPAÑA
VICEPRESIDENCIA TERCERA DEL GOBIERNO
MINISTERIO PARA LA TRANSICIÓN ECOLÓGICA Y EL RETO DEMOGRÁFICO

Boletín de información nivológica y de peligro de aludes

Pirineo Navarro y Aragonés

aemet Agencia Estatal de Meteorología

miércoles, 18 de febrero de 2026

Pronóstico hasta las 24 horas del jueves, día 19 de febrero

(Válido fuera de pistas de esquí balizadas y abiertas)

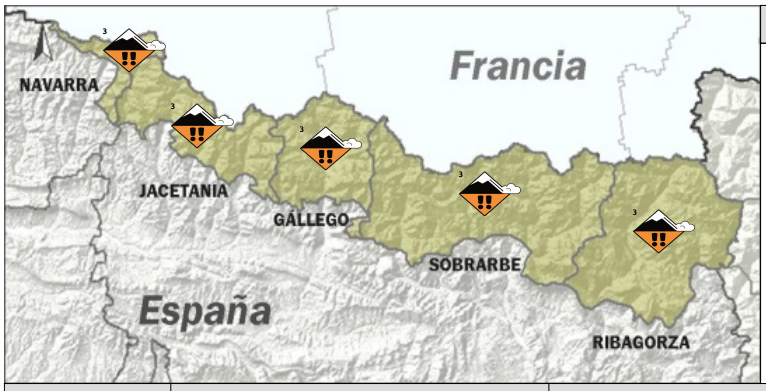

Problemas de aludes

Placas de viento

Nieve reciente

Macizo	Peligro	Problemas de aludes, cota, orientación, tamaño	Innivación observada (m)
Navarra	3 Notable	Placas de viento: 2100, N E S O, 3 Nieve reciente: N E S O, 2	2026-02-18 N S Cotas bajas
Jacetania	3 Notable	Placas de viento: 2100, N E S O, 3 Nieve reciente: N E S O, 2	2026-02-18 N S Cotas bajas
Gállego	3 Notable	Placas de viento: 2100, N E S O, 3 Nieve reciente: N E S O, 2	2026-02-18 N S Cotas bajas

AEMET. Se autoriza la reproducción de su contenido citando la fuente.

Boletín de información nivológica y de peligro de aludes

Pirineo Navarro y Aragonés

Sobrarbe	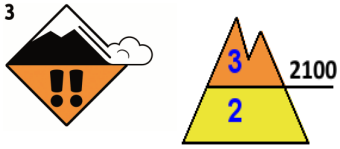 **Notable**	**Placas de viento** **Nieve reciente** 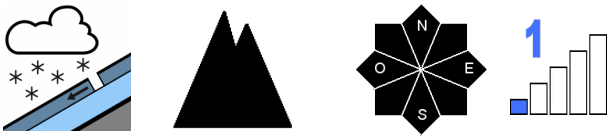	2026-02-18 Cotas bajas
Ribagorza	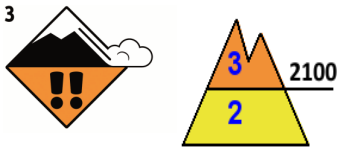 **Notable**	**Placas de viento** **Nieve reciente** 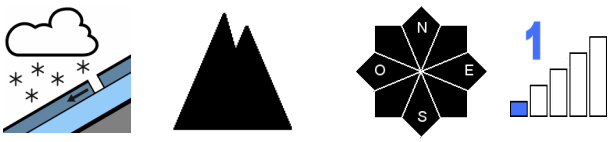	2026-02-18 Cotas bajas

Estado del manto y observaciones recientes

Lluvias débiles en las últimas 24 h que han menguado en torno a 5 cm los espesores medidos en la red de observación. Aun así, el manto sigue siendo continuo desde fondos de valle y presenta espesores muy por encima del promedio habitual a estas alturas de la temporada. En torno a 2100 metros se superan fácilmente los 150-200 cm, aún más en ventisqueros, hoyas y otras zonas propensas a la acumulación. Esquiable a partir de 1500 m en solanas y fondo de valle en las umbrías.

Manto grueso y encostrado en general, con acumulaciones sobre todo en el cuadrante S en cotas altas debido al transporte del viento. También en cotas altas, solanas con costra portante. Nieve nueva rápidamente humedecida debido a la radiación solar, alta humedad y temperatura. En las zonas umbrías con acumulación no hay costra en superficie y las acumulaciones de nieve venteada pueden reposar localmente sobre cristales facetados pequeños. Con la humidificación del manto se espera poca actividad de estos niveles internos.

En cotas bajas y medias: en las zonas orientales hasta 2100 m aproximadamente manto humedecido que ha desarrollado costra portante de 5 a 10 cm, por debajo totalidad del manto humedecido. En las zonas occidentales a partir de 1900 m 10 cm de nieve reciente húmeda sobre la costra formada anteayer. Ayer se formaron placas de viento, muy aisladas en la zona S cerca de collados, suponemos más extensas en la fachada norte.

En umbrías altas por encima de 2400 m, del Somport al este, capas débiles persistentes durmientes tras el encostramiento superficial (dudas en cotas superiores a 2800-2900).

En las últimas 24 h se reportan varios aludes desde la red de observación: dos pequeños en el sector navarro, con altitud de salida 1500-1750 m en orientación mayoritariamente SE, uno grande de placa dura en el Alto Gállego con altitud de salida 2500-3000 m en orientación E y numerosos medianos en la Ribagorza con altitud de salida 2500-3000 m en orientación N la mayoría.

AEMET. Se autoriza la reproducción de su contenido citando la fuente.

Evolución del manto y peligro de aludes para el jueves, día 19

Problema de placas de viento en cotas altas. Problema de nieve reciente.

Esta tarde y mañana jueves se esperan nevadas significativas, con acumulaciones de 5-10 cm por encima de 900-1000 metros que en cotas altas del sector navarro, la Jacetania y Alto Gállego podrán alcanzar los 20-25 cm.
Se podrán formar nuevas placas con los fuertes vientos del W y NW, principalmente por encima de los 2100 m, en un amplio sector E, bajo collados y cordales. Estas placas serán pequeñas por lo general, pero podrán ser reactivas y romper fácilmente al paso de una sola persona. Los aludes de placa que se puedan desencadenar serán pequeños si involucran la nevada reciente, o hasta tamaño mediano si afectan a niveles de manto viejo o placas antiguas. En laderas umbrías de cotas altas con poco espesor su rotura es capaz de desencadenar aludes de tamaño grande.
En la alta montaña, habrá que extremar la precaución con las probables ventiscas, que podrán ser intensas.
En sectores resguardados o poco afectados por el viento, en vertientes propicias, son probables aludes de nieve reciente de tamaño pequeño o mediano, sin descartar que alcancen tamaño grande en las zonas de mayores acumulaciones. La probabilidad de aludes será mayor con el paso de las horas.

Predicción meteorológica para el jueves, día 19

Pirineo navarro:
Muy nuboso o cubierto, con visibilidad localmente reducida.
Precipitaciones débiles o moderadas, en ocasiones en forma de chubascos, que podrán ser persistentes localmente. Cota de nieve: en torno a 1100 metros, bajando transitoriamente hasta los 800 a primeras horas.
No se descartan tormentas ocasionalmente de madrugada.
Temperaturas en descenso, ligero o moderado de las mínimas y notable de las máximas. Heladas débiles, moderadas en cotas altas, donde podrán ser localmente fuertes y persistentes.
Viento fuerte del oeste y noroeste, con rachas muy fuertes en cotas altas y zonas expuestas.

Pirineo aragonés:
Muy nuboso o cubierto, con visibilidad localmente reducida.
Precipitaciones débiles o moderadas, en ocasiones en forma de chubascos, más frecuentes en la Jacetania y Alto Gállego, donde podrán ser localmente persistentes. Cota de nieve: en torno a 1100 metros, bajando transitoriamente hasta los 800 a primeras horas.
No se descartan tormentas ocasionalmente de madrugada, en la Jacetania y zonas próximas.
Temperaturas mínimas en ligero o moderado descenso. Máximas en moderado o notable descenso. Heladas débiles o moderadas, fuertes y persistentes en la alta montaña.
Viento fuerte del oeste y noroeste, con rachas muy fuertes, que en cotas altas y zonas expuestas podrán superar los 90 km/h.

AEMET. Se autoriza la reproducción de su contenido citando la fuente.

Datos en la atmósfera libre:

Altitud de la isoterma de 0 ºC: 1500 m
Altitud de la isoterma de -10 ºC: 3100 m

Viento a 1500 m: NW 50 km/h
Viento a 3000 m: NW 100 km/h

Evolución para el viernes día 20

Nivel de peligro sin cambios o en ligero descenso.

(Información elaborada a partir de los datos recibidos de los refugios de Linza, Lizara, Panticosa, Bachimaña, Góriz, Pineta, Estós, Angel Orús, La Renclusa, Cap de Llauset y Belagua, de las estaciones de esquí de Candanchú, Astún, Formigal y Panticosa (lagos) y de la estación de esquí de fondo de Llanos del Hospital)

Escala europea de peligro de aludes

Débil | Limitado | Notable | Fuerte | Muy Fuerte

Problemas de aludes

Nieve reciente | Placas de viento | Capas débiles persistentes | Nieve húmeda | Deslizamientos basales | Sin problema evidente

Nota1: Se recuerda que, siempre que haya nieve, la ausencia total de peligro no existe. Hay que tener presente que en circunstancias desfavorables, con aludes de tamaño 1 (alud pequeño o colada) y tamaño 2 (alud mediano), se pueden sufrir severos daños personales.

Nota2: Los BPA se elaboran en base a información meteorológica así como al estado del manto nivoso a través de sondeos puntuales. Se advierte a los usuarios de la variabilidad de esta información al extrapolarla a zonas extensas de montaña. Por ello, AEMET no se hace responsable de su uso para la toma de decisiones que conciernen a la seguridad personal, ni de los riesgos físicos o materiales de ellas derivadas.

AEMET. Se autoriza la reproducción de su contenido citando la fuente.