aineva.it

Donnerstag 19.02.2026

Veröffentlicht am 18.02.2026 um 17:00

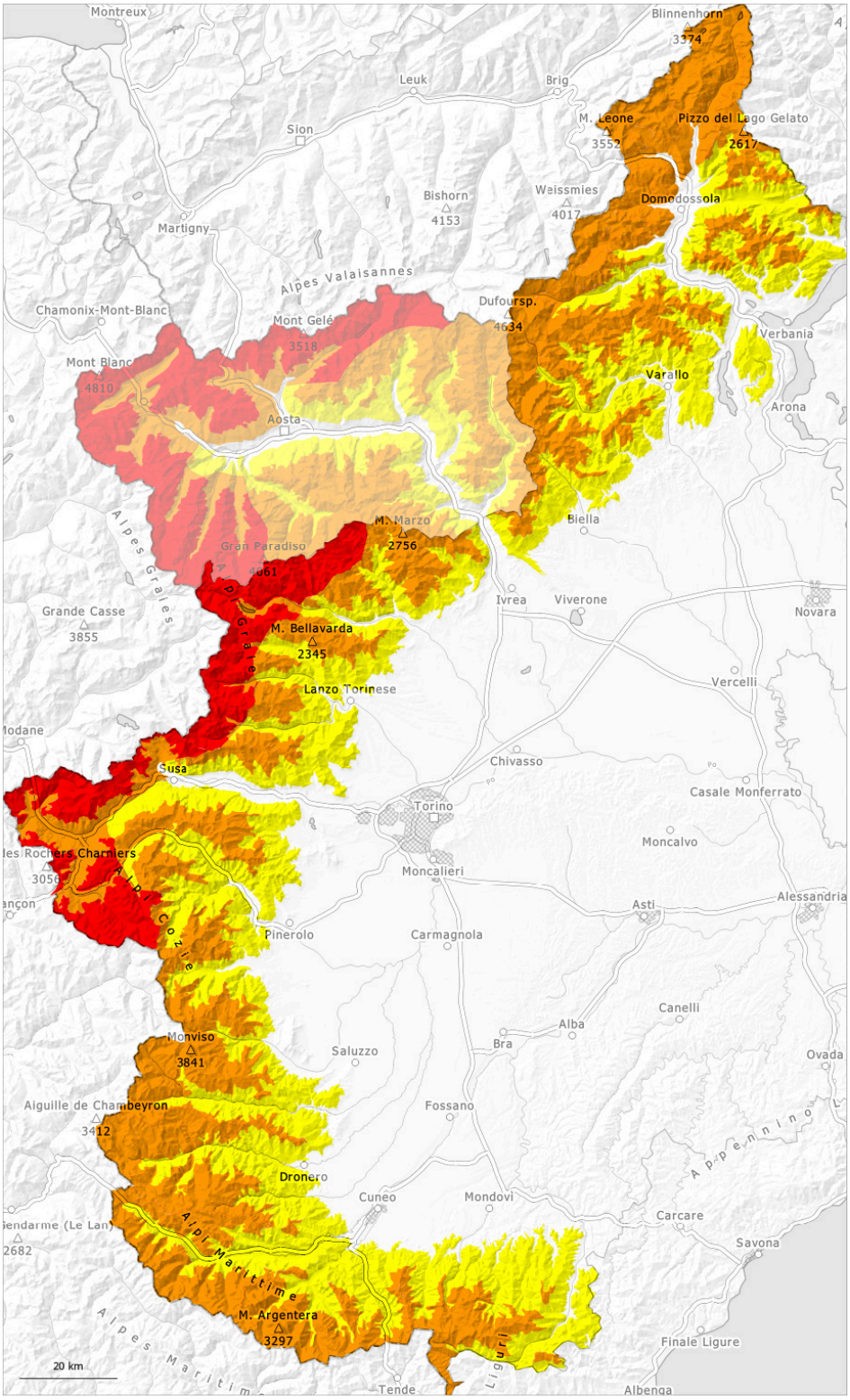

1	2	3	4	5
gering	mäßig	erheblich	groß	sehr groß

Gefahrenstufe 4 - Groß

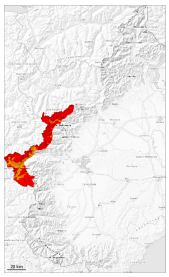

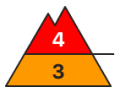

2100m

Tendenz: Lawinengefahr nimmt ab
am Freitag, den 20.02.2026

Triebschnee

2100m

Triebschnee

2100m

Mit Neuschnee und Sturm gebietsweise noch gefährliche Lawinensituation.

Mit Schneefall und teils stürmischem Nordwestwind entstanden in den letzten drei Tagen frische Triebschneeansammlungen. Dies vor allem in den Föhngebieten und im Bereich der Waldgrenze und in Rinnen, Mulden und hinter Geländekanten.
Die störanfälligen Triebschneeansammlungen können schon von einzelnen Wintersportlern leicht ausgelöst werden.

An Triebschneehängen und aus noch nicht entladenen Einzugsgebieten sind mit der Erwärmung einzelne große und vereinzelt sehr große Staublawinen möglich.

Schneedecke

Gefahrenmuster gm.6: lockerer schnee und wind

Seit Montag fielen gebietsweise verbreitet 50 bis 90 cm Schnee, lokal auch mehr.
Der teilweise stürmische Wind hat viel Schnee verfrachtet.
V.a. in Gipfellagen liegen je nach Windeinfluss sehr unterschiedliche Schneehöhen.

In der Altschneedecke sind vor allem an steilen Nordwest-, Nord- und Osthängen störanfällige Schwachschichten vorhanden. Vor allem kammfern sowie in windgeschützten Lagen: Verschiedene Triebschneeschichten liegen stellenweise auf Oberflächenreif.

Gefahrenstufe 3 - Erheblich

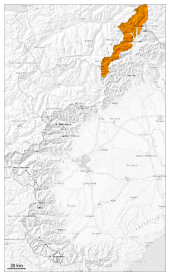

3

Tendenz: Lawinengefahr nimmt ab
am Freitag, den 20.02.2026

Triebschnee

Mit Neuschnee und Sturm gebietsweise noch gefährliche Lawinensituation.

Mit Schneefall und teils stürmischem Nordwestwind entstanden in den letzten drei Tagen frische Triebschneeansammlungen. Dies vor allem in den Föhngebieten und im Bereich der Waldgrenze und in Rinnen, Mulden und hinter Geländekanten.
Die störanfälligen Triebschneeansammlungen können schon von einzelnen Wintersportlern leicht ausgelöst werden.

An Triebschneehängen und aus noch nicht entladenen Einzugsgebieten sind mit der Erwärmung mittlere und große trockene und feuchte Lawinen möglich.

Schneedecke

Gefahrenmuster gm.6: lockerer schnee und wind

Seit Montag fielen gebietsweise verbreitet 40 bis 80 cm Schnee, lokal auch mehr.
Der teilweise stürmische Wind hat viel Schnee verfrachtet.
V.a. in Gipfellagen liegen je nach Windeinfluss sehr unterschiedliche Schneehöhen.

In der Altschneedecke sind vor allem an steilen Nordwest-, Nord- und Osthängen störanfällige Schwachschichten vorhanden.

Gefahrenstufe 3 - Erheblich

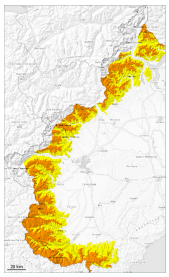

Tendenz: Lawinengefahr bleibt gleich
am Freitag, den 20.02.2026

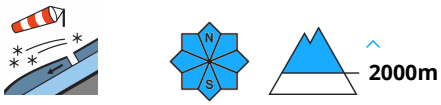

Triebschnee

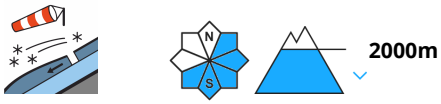

Triebschnee

Es fällt verbreitet Schnee bis in tiefe Lagen. Der Wind bläst stark. Triebschnee ist die Hauptgefahr.

Der teilweise starke Wind verfrachtet Neu- und Altschnee intensiv. Mit starkem Nordwestwind entstehen bis am Morgen frische Triebschneeansammlungen. Diese entstehen vor allem oberhalb von rund 2000 m.

Vor allem mittlere und hohe Lagen sowie in windgeschützten Lagen: Weiche Triebschneeansammlungen können im Bereich der Waldgrenze von einzelnen Wintersportlern ausgelöst werden.

Zudem sind die harten Triebschneeansammlungen der letzten Tage in Passlagen aller Expositionen und allgemein in der Höhe weiterhin auslösbar. Dies vor allem mit großer Belastung. Die älteren Triebschneeansammlungen werden überschneit und damit schwierig zu erkennen.

Mit der Erwärmung sind mehrere mittlere und vereinzelt große trockene und feuchte Lawinen möglich.

Schneedecke

Gefahrenmuster gm.6: lockerer schnee und wind

Am Donnerstag fallen lokal oberhalb von rund 1500 m 5 bis 20 cm Schnee, lokal auch mehr. Der starke Wind verfrachtet Neu- und Altschnee intensiv.
V.a. in Gipfellagen liegen je nach Windeinfluss sehr unterschiedliche Schneehöhen.

Westliche Voralpen und entlang der Grenze zu Frankreich: In der Altschneedecke sind vor allem an steilen Nordwest-, Nord- und Osthängen vereinzelt störanfällige Schwachschichten vorhanden. Neu- und Triebschnee liegen stellenweise auf Oberflächenreif.