Donnerstag 19.02.2026

Veröffentlicht am 18.02.2026 um 17:00

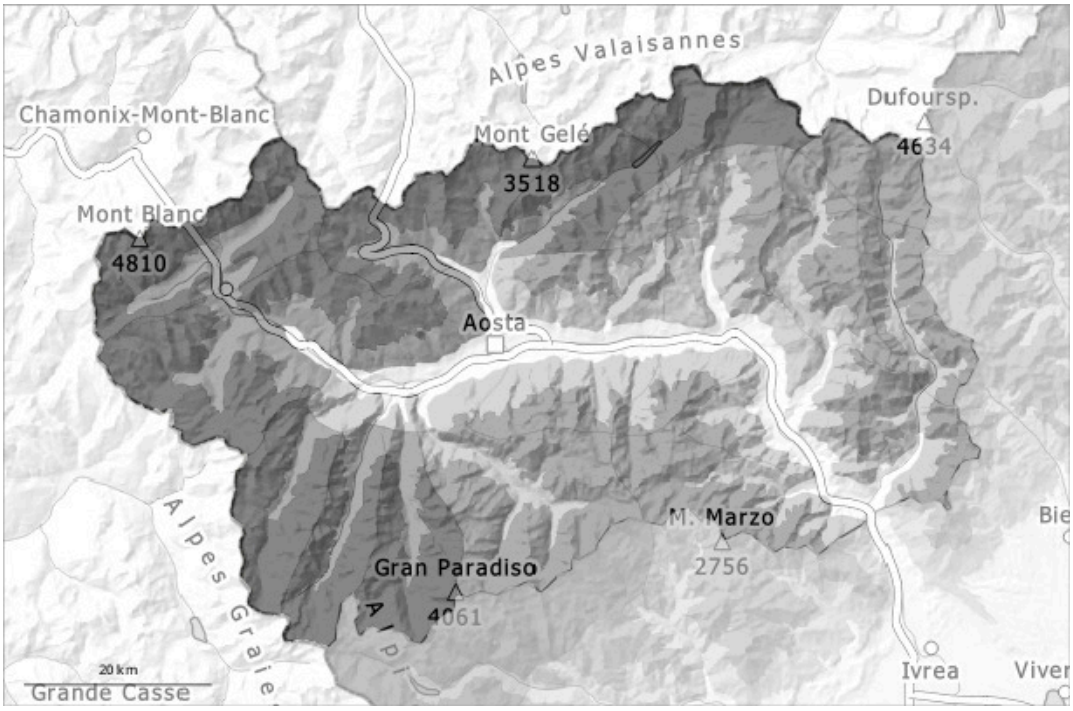

1	2	3	4	5
gering	mäßig	erheblich	groß	sehr groß

Gefahrenstufe 4 - Groß

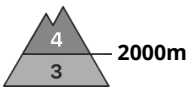

Tendenz: Lawinengefahr nimmt ab
am Freitag, den 20.02.2026

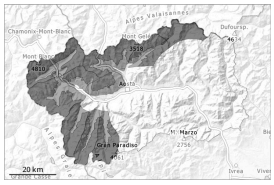

Triebschnee

Neuschnee

Die spontane Aktivität von Lawinen nimmt am Vormittag zu.

Mit Schneefall und starkem Nordwestwind wachsen die Triebschneeansammlungen ab dem Morgen an. Auch bereits entleerte Einzugsgebiete werden mit Schneefall und Wind wieder aufgefüllt. Dort sind mittlere und große spontane trockene Lawinen möglich.
Die Lawinen können in den typischen Lawinenzügen weiterhin sehr groß werden und exponierte Verkehrswege vereinzelt gefährden. Es sind weiterhin Staublawinen möglich.
Für Touren und Variantenabfahrten abseits gesicherter Pisten sind die Verhältnisse heimtückisch. Einzelne Wintersportler können Lawinen auslösen, auch große.

Schneedecke

Gefahrenmuster gm.6: lockerer schnee und wind | gm.1: bodennahe schwachschicht

Seit Sonntag fielen oberhalb von rund 1500 m verbreitet 50 bis 80 cm Schnee, lokal auch mehr. Bis am Abend fallen oberhalb von rund 1800 m verbreitet 30 bis 40 cm Schnee, lokal auch mehr. Der Wind bläst verbreitet stark.
Die Schneedecke ist ungünstig geschichtet.
In Kamm- und Passlagen liegen je nach Windeinfluss sehr unterschiedliche Schneehöhen.
Am Dienstag sind einige große und vereinzelt sehr große Staublawinen abgegangen.

Tendenz

Die Gefahr von spontanen Lawinen nimmt ab.

Gefahrenstufe 3 - Erheblich

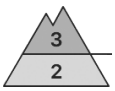

2100m

Tendenz: Lawinengefahr bleibt gleich
am Freitag, den 20.02.2026

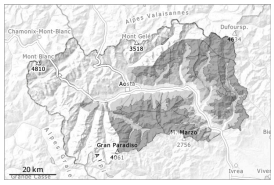

Triebschnee

2100m

Altschnee

2000m

Der Wind bläst stark. Triebschnee ist die Hauptgefahr.

Mit Neuschnee und starkem Wind nimmt die Größe der Gefahrenstellen am Vormittag zu.
Vorsicht an sehr steilen Hängen und in Rinnen, Mulden und hinter Geländekanten. Lawinen können schon von einzelnen Wintersportlern ausgelöst werden.
Schwachschichten im Altschnee erfordern Vorsicht. Die Lawinen können stellenweise im Altschnee ausgelöst werden und recht groß werden.
Fernauslösungen sind möglich. Wummgeräusche und Risse beim Betreten der Schneedecke sind Alarmzeichen.

Schneedecke

Gefahrenmuster gm.6: lockerer schnee und wind | gm.1: bodennahe schwachschicht

Seit Sonntag fielen oberhalb von rund 1600 m verbreitet 15 bis 40 cm Schnee. Am Donnerstag fallen oberhalb von rund 1600 m verbreitet 10 bis 15 cm Schnee, lokal auch mehr. Der Wind bläst stark.
In Kamm- und Passlagen liegen je nach Windeinfluss sehr unterschiedliche Schneehöhen. Die Schneedecke ist ungünstig geschichtet.
In der Altschneedecke sind v.a. an West-, Nord- und Osthängen kantig aufgebaute Schwachschichten vorhanden.
Am Dienstag sind vereinzelt mittlere bis große spontane trockene Lawinen abgegangen.