ICGC Institut Cartogràfic i Geològic de Catalunya

Servei Meteorològic de Catalunya meteo.cat

Boletín de peligro de aludes para el Pirineo de Catalunya
Del 18/02/2026 al 19/02/2026

(Válido fuera pistas de esquí y zonas no controladas)

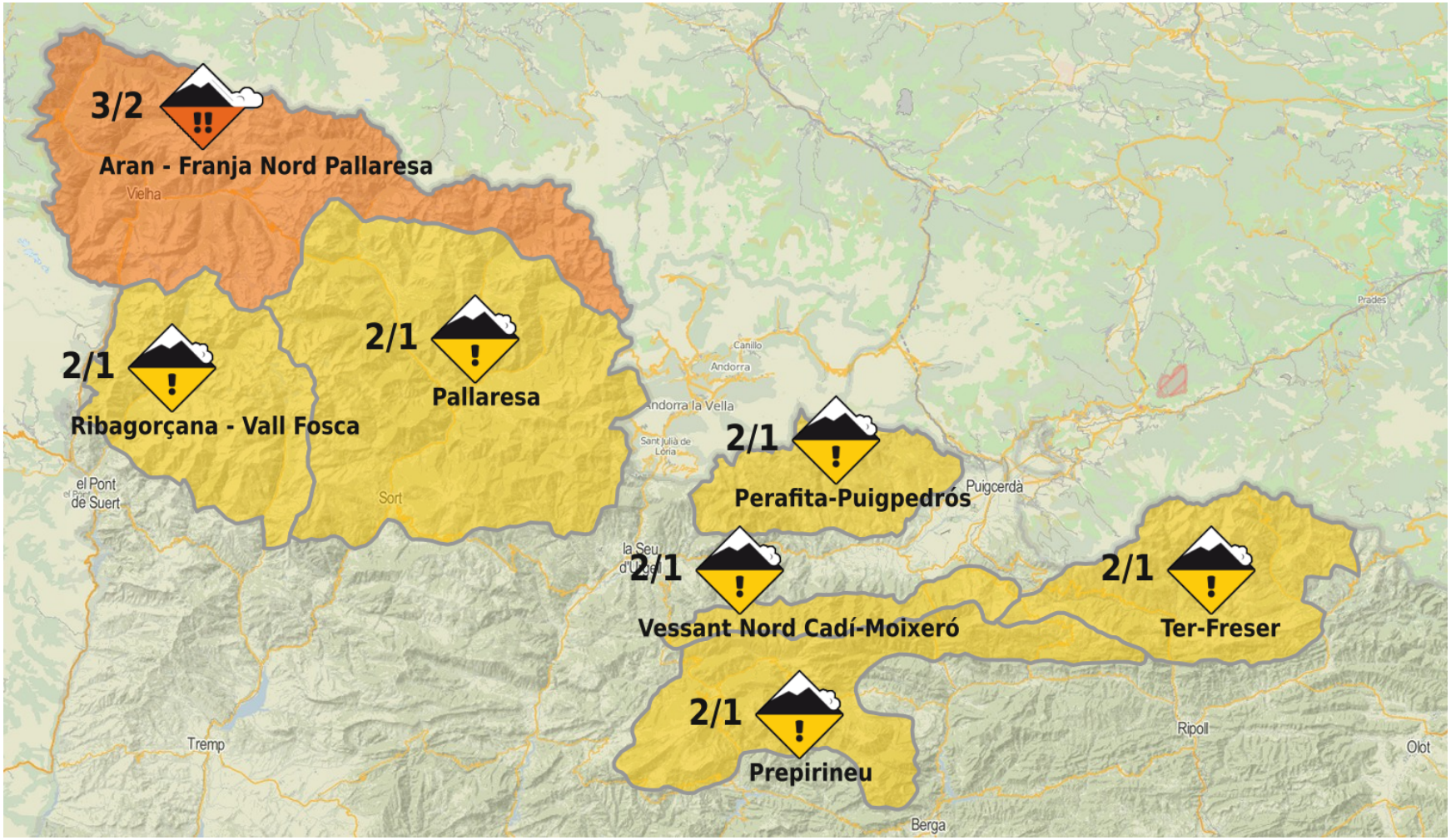

5 MUY FUERTE	4 FUERTE	3 NOTABLE	2 LIMITADO	1 DÉBIL

ICGC Institut Cartogràfic i Geològic de Catalunya

meteo.cat Servei Meteorològic de Catalunya

Boletín de peligro de aludes Aran - Franja Nord Pallaresa Del 18/02/2026 al 19/02/2026

(Válido fuera pistas de esquí y zonas no controladas)

NOTABLE (3) por encima de 2.000 m. LIMITADO (2), por debajo.

Situación primaria

Nieve venteada

Distribución

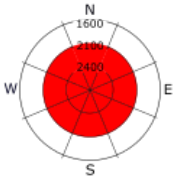

Tamaño

Origen

Tendencia

Situación secundaria

Nieve reciente

Distribución

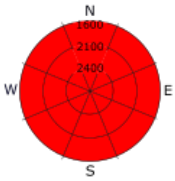

Tamaño

Origen

Tendencia

Estado del manto nivoso

Se han registrado algunos aludes de nieve húmeda, de placa y algún deslizamiento basal. Hoy miércoles se observa transporte efectivo de nieve en varias crestas y cimas del sector. El viento se intensificará la tarde del miércoles, de componente SW-W, con precipitaciones débiles. Mañana jueves el viento será intenso del NW y un nuevo episodio de nieve podrá dejar unos 15-20 mm a lo largo del día, con cota de nieve baja.

Se formarán nuevas placas de viento, en cualquier orientación, por encima de unos 2.000 m, bajo collados y cordales, y pequeñas cuencas. Estas placas se podrán mostrar muy sensibles y romper muy fácilmente al paso de una persona, generando aludes de tamaño medio en general. En sectores resguardados o poco afectados por el viento, en vertientes propicias, son probables aludes de nieve reciente de pequeño tamaño en general. El jueves, la probabilidad de aludes será mayor con el paso de las horas. No se descarta todavía la posibilidad de algunos deslizamientos basales.

Distribución del manto nivoso

Hay nieve en el suelo a 1.400 m en Norte. El manto es esquiable por encima de unos 1.500 m en umbrías. Los espesores a unos 2.200 m son superiores a los normales y rondan los 120-140 cm en el norte de Arán y los 180-220 cm en la Franja Norte Pallaresa y en el sur de Aran.

Tendencia para las próximas 48-72h

El viento y las débiles nevadas persistirán hasta el viernes. Peligro ESTACIONARIO.

El próximo boletín será emitido el día 2026-02-19

5 MUY FUERTE	4 FUERTE	3 NOTABLE	2 LIMITADO	1 DÉBIL

EAWS EUROPEAN AVALANCHE WARNING SERVICES

ICGC Institut Cartogràfic i Geològic de Catalunya

Servei Meteorològic de Catalunya meteo.cat

Boletín de peligro de aludes Ribagorçana - Vall Fosca Del 18/02/2026 al 19/02/2026

(Válido fuera pistas de esquí y zonas no controladas)

LIMITADO (2), por encima del límite de bosque. DÉBIL (1), por debajo

Situación primaria

Nieve venteada

Distribución

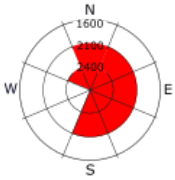

Tamaño

Origen

Tendencia

Estado del manto nivoso

Se espera un nuevo episodio de nieve, entre débil y moderado, de miércoles por la noche al jueves por la noche, con breve pausa la madrugada del jueves. El viento será de nuevo protagonista, fuerte el miércoles, del W, y muy fuerte el jueves, del NW. Superficialmente encontramos un manto endurecido por la presencia de costras de lluvia y de fusión-rehielo, o de nieve venteada muy compacta. Existe poca disponibilidad de nieve transportable con la actual estructura del manto, pero se formarán nuevas placas con la nueva nevada que podrán coexistir con las placas más antiguas. Las encontraremos por encima del nivel de bosque, en orientaciones E, S y N, bajo collados y cordales y pequeñas cuencas. Las nuevas placas serán pequeñas por lo general pero podrán ser reactivas y romper fácilmente de forma accidental.

Los aludes que se puedan desencadenar serán pequeños si involucran la nevada reciente, o hasta tamaño medio si afectan a niveles de manto interno.

Distribución del manto nivoso

Hay nieve en el suelo a 1.500 m. El manto es esquiable por encima de unos 1500-1600 m. Los grosores alcanzan los 130-160 cm. Estos valores son muy superiores a los normales en la época.

Tendencia para las próximas 48-72h

El viento persistirá hasta el viernes y las placas continuarán activas. Peligro ESTACIONARIO.

El próximo boletín será emitido el día 2026-02-19

5 MUY FUERTE	4 FUERTE	3 NOTABLE	2 LIMITADO	1 DÉBIL

EAWS EUROPEAN AVALANCHE WARNING SERVICES

ICGC Institut Cartogràfic i Geològic de Catalunya

Servei Meteorològic de Catalunya meteo.cat

Boletín de peligro de aludes Pallaresa
Del 18/02/2026 al 19/02/2026

(Válido fuera pistas de esquí y zonas no controladas)

LIMITADO (2), por encima del límite de bosque. DÉBIL (1), por debajo.

Situación primaria

Nieve venteada

Distribución

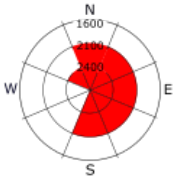

Tamaño

Origen

Tendencia

Estado del manto nivoso

Se espera un nuevo episodio de nieve, entre débil y moderado, de miércoles por la noche al jueves por la noche, con breve pausa la madrugada del jueves. El viento será de nuevo protagonista, fuerte el miércoles, del W, y muy fuerte el jueves, del NW. Superficialmente encontramos un manto endurecido por la presencia de costras de lluvia y de fusión-rehielo, o de nieve venteada muy compacta. Existe poca disponibilidad de nieve transportable con la actual estructura del manto, pero se formarán nuevas placas con la nueva nevada que podrán coexistir con las placas más antiguas. Las encontraremos por encima del nivel de bosque, en orientaciones E, S y N, bajo collados y cordales y pequeñas cuencas. Las nuevas placas serán pequeñas por lo general pero podrán ser reactivas y romper fácilmente de forma accidental.
Los aludes que se puedan desencadenar serán pequeños si involucran la nevada reciente, o hasta tamaño medio si afectan a niveles de manto interno.

Distribución del manto nivoso

Hay nieve en el suelo a 1.500 m. El manto es esquiable por encima de unos 1500-1600 m. Los grosores alcanzan los 130-160 cm. Estos valores son muy superiores a los normales para la época.

Tendencia para las próximas 48-72h

El viento persistirá hasta el viernes y las placas continuarán activas. Peligro ESTACIONARIO.

El próximo boletín será emitido el día 2026-02-19

5 MUY FUERTE	4 FUERTE	3 NOTABLE	2 LIMITADO	1 DÉBIL

EAWS EUROPEAN AVALANCHE WARNING SERVICES

ICGC Institut Cartogràfic i Geològic de Catalunya

Servei Meteorològic de Catalunya

Boletín de peligro de aludes Perafita-Puigpedrós Del 18/02/2026 al 19/02/2026

(Válido fuera pistas de esquí y zonas no controladas)

LIMITADO (2), por encima del límite de bosque. DÉBIL (1), por debajo

Situación primaria

Nieve venteada

Distribución

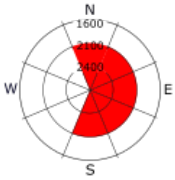

Tamaño

Origen

Tendencia

Estado del manto nivoso

El manto se encuentra endurecido superficialmente, bien por la presencia de una costra, bien por nieve venteada muy compacta. Entre hoy miércoles por la noche y mañana jueves se esperan nevadas débiles o moderadas en el sector, con fuerte viento del W primero y NW el jueves.

Se podrán formar nuevas placas, locales debido al fuerte viento, principalmente por encima del nivel de bosque, en orientaciones E, S y, en menor medida, N, bajo collados y cordales. Estas placas serán pequeñas por lo general, pero podrán ser reactivas y romper fácilmente al paso de una persona.

Los aludes de placa de viento que se puedan desencadenar serán pequeños si involucran la nevada reciente, o hasta tamaño medio si afectan a niveles de manto viejo o placas antiguas.

En caso de circular por la montaña, habrá que tener cuidado con la ventisca, que podrá ser intensa.

Distribución del manto nivoso

Hay nieve en el suelo por encima de 1.400-1500 m. Sin embargo, el manto es esquiable por encima de 1.500-1.600 m. Los grosores alcanzan los 130-150 cm a 2.200 m. Son grosores muy por encima de los habituales para la época.

Tendencia para las próximas 48-72h

El viento persistirá hasta el viernes y las placas continuarán activas. Peligro ESTACIONARIO.

El próximo boletín será emitido el día 2026-02-19

5 MUY FUERTE	4 FUERTE	3 NOTABLE	2 LIMITADO	1 DÉBIL

EAWS EUROPEAN AVALANCHE WARNING SERVICES

ICGC Institut Cartogràfic i Geològic de Catalunya

Servei Meteorològic de Catalunya

Boletín de peligro de aludes Vessant Nord Cadí-Moixeró Del 18/02/2026 al 19/02/2026

(Válido fuera pistas de esquí y zonas no controladas)

LIMITADO (2), por encima del límite de bosque. DÉBIL (1), por debajo

Situación primaria

Nieve venteada

Distribución

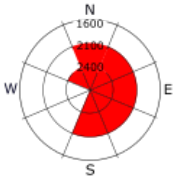

Tamaño

Origen

Tendencia

Estado del manto nivoso

El manto se encuentra endurecido superficialmente por el efecto del viento, o el humedecimiento de días atrás y posterior encostramiento. El episodio de nieve previsto entre hoy miércoles por la noche y mañana jueves dejará nevadas débiles en el sector acompañadas de viento fuerte del W y NW.

Es probable la formación de nuevas placas en orientaciones E, S y, en menor medida, N, bajo collados y cordales, y en las canales más resguardadas, por encima del límite de bosque. Estas nuevas placas serán por lo general locales y pequeñas, pero se podrán mostrar sensibles y romper fácilmente al paso de una persona. Los aludes de placa podrán ser de hasta tamaño medio si involucran niveles de manto viejo o placas antiguas. Hay que tener cuidado con el terreno trampa, donde un alud pequeño puede llegar a enterrarnos.

Distribución del manto nivoso

Hay nieve desde 1.300 m. en norte y desde 1.400 a 1500 m. en sur, esquiable por encima de unos 1.500 m. Los grosores están alrededor de 150-170 cm a 2.200 m. Estos valores son muy excedentarios para la época del año.

Tendencia para las próximas 48-72h

El viento persistirá hasta el viernes y las placas continuarán activas. Peligro ESTACIONARIO.

El próximo boletín será emitido el día 2026-02-19

5 MUY FUERTE	4 FUERTE	3 NOTABLE	2 LIMITADO	1 DÉBIL

EAWS EUROPEAN AVALANCHE WARNING SERVICES

ICGC Institut Cartogràfic i Geològic de Catalunya

meteo.cat Servei Meteorològic de Catalunya

Boletín de peligro de aludes Prepirineu
Del 18/02/2026 al 19/02/2026

(Válido fuera pistas de esquí y zonas no controladas)

LIMITADO (2), por encima del límite de bosque. DÉBIL (1), por debajo

Situación primaria

Nieve venteada

Distribución

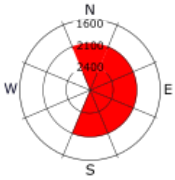

Tamaño

Origen

Tendencia

Estado del manto nivoso

El manto se encuentra endurecido superficialmente por el efecto del viento o el humedecimiento de días atrás y posterior encostramiento. El episodio de nieve previsto entre hoy miércoles por la noche y mañana jueves dejará nevadas débiles en el sector acompañadas de viento fuerte del W y NW.

Se podrán formar nuevas placas de viento, principalmente por encima del nivel de bosque, en orientaciones E, S, y también N aunque menos frecuentes, bajo collados y cordales y pequeñas cuencas. Estas placas serán de pequeño tamaño en general, pero podrán ser reactivas y romper con facilidad accidentalmente. Los aludes de placa que se puedan desencadenar serán pequeños si involucran la nevada reciente, o hasta tamaño medio si afectan a niveles de manto viejo o placas antiguas.

Distribución del manto nivoso

Hay nieve desde 1400-1500 m. El manto es esquiable a partir de 1600 m. Los grosores están alrededor de 110-130 cm a unos 2.200 m y son superiores a los habituales.

Tendencia para las próximas 48-72h

El viento persistirá hasta el viernes y las placas continuarán activas. Peligro ESTACIONARIO.

El próximo boletín será emitido el día 2026-02-19

5 MUY FUERTE	4 FUERTE	3 NOTABLE	2 LIMITADO	1 DÉBIL

EAWS EUROPEAN AVALANCHE WARNING SERVICES

ICGC Institut Cartogràfic i Geològic de Catalunya

meteo.cat Servei Meteorològic de Catalunya

Boletín de peligro de aludes Ter-Freser
Del 18/02/2026 al 19/02/2026

(Válido fuera pistas de esquí y zonas no controladas)

LIMITADO (2), por encima del límite de bosque. DÉBIL (1), por debajo

Situación primaria

Nieve venteada

Distribución

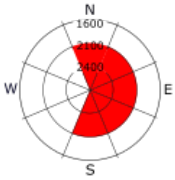

Tamaño

Origen

Tendencia

Estado del manto nivoso

El manto se encuentra endurecido superficialmente, bien por la presencia de una costra, bien por nieve venteada muy compacta. Entre hoy miércoles por la noche y mañana jueves se esperan nevadas débiles en el sector, con fuerte viento del W primero y NW el jueves.

Se podrán formar nuevas placas, locales debido al fuerte viento, principalmente por encima del nivel de bosque, en orientaciones E, S y, en menor medida, N, bajo collados y cordales y pequeñas cuencas. Estas placas serán pequeñas por lo general, pero podrán ser reactivas y romper fácilmente al paso de una persona. Los aludes de placa que se puedan desencadenar serán pequeños si involucran la nevada reciente, o hasta tamaño medio si afectan a niveles de manto viejo o placas antiguas.

En caso de circular por la montaña, habrá que tener mucho cuidado con la ventisca, que podrá ser intensa.

Distribución del manto nivoso

El manto nivoso presenta grosores muy excedentarios para la época del año. En lugares no afectados por el viento, los espesores oscilan entre 100-140 cm a unos 2.000 m, siendo esquiable a partir de unos 1.500 m.

Tendencia para las próximas 48-72h

El viento persistirá hasta el viernes y las placas continuarán activas. Peligro ESTACIONARIO.

El próximo boletín será emitido el día 2026-02-19

5 MUY FUERTE	4 FUERTE	3 NOTABLE	2 LIMITADO	1 DÉBIL

EAWS EUROPEAN AVALANCHE WARNING SERVICES