BUTLLETÍ DEL PERILL D'ALLAUS DEL PRINCIPAT D'ANDORRA

Servei meteorològic nacional
Principat d'Andorra

Elaborat el 18/02/2026 16:00
Propera actualització 19/02/2026 a les 16h

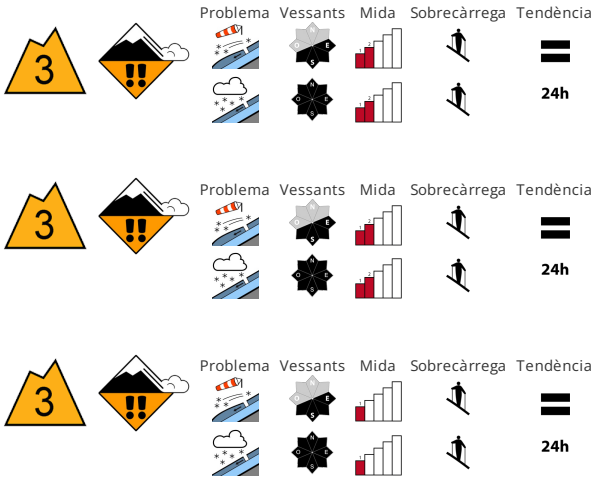

ESTABILITAT DEL MANTELL NIVAL

La neu recent i les plaques de vent han de ser avaluades amb cautela., especialment en vessants inclinats orientats a nord-est , sud i sud-est , i també en cubetes, canals i darrere de canvis abruptes de pendent. Les allaus poden en alguns indrets ser desencadenades al pas d'un muntanyenc i assolir mida mitjana. Els indrets perillosos són parcialment coberts de neu recent i difícils de reconèixer amb mala visibilitat. Es recomana una selecció acurada de la ruta i mantenir la distància entre els components.

QUALITAT DE LA NEU

Sobretot al nord fins al dijous cauran en alguns sectors fins a 30 cm de neu per sobre dels 1500 m aproximadament, localment fins a 30 cm. La neu recent de dijous es dipositarà a sobre d'un mantell de neu vella bastant favorable. Amb la neu recent i el vent les plaques de vent augmentaran de mida addicionalment. Aquesta neu ha de ser avaluada amb cautela. Els gruixos de neu varien molt per sobre dels 2600 m aproximadament per la influència del vent.

GRUIXOS DEL MANTELL NIVAL FORA DE PISTA

Zona nord		Gruix neu		
Mantell Nival		1500m	2000m	2500m
N	1300 m	50 cm	150 cm	200 cm
S	1500 m	0 cm	100 cm	150 cm

Zona centre		Gruix neu		
Mantell Nival		1500m	2000m	2500m
N	1300 m	30 cm	150 cm	200 cm
S	1500 m	0 cm	100 cm	150 cm

Zona sud		Gruix neu		
Mantell Nival		1500m	2000m	2500m
N	1300 m	30 cm	120 cm	150 cm
S	1500 m	0 cm	60 cm	100 cm

Govern d'Andorra

EAWS EUROPEAN AVALANCHE WARNING SERVICES

Aquest butlletí ha estat elaborat seguint les normes i recomanacions de l'**European Avalanche Warning Services**, del qual el **Servei meteorològic Nacional** n'és membre

Informació detallada per espais naturals protegits

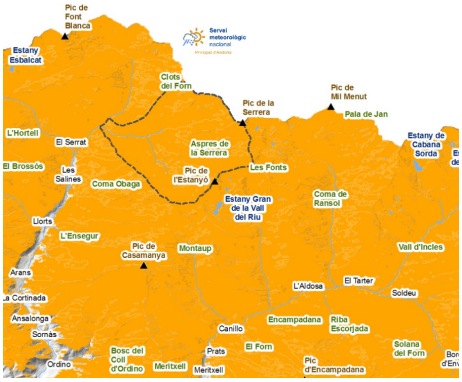

SORTENY

Les nevades del cap de setmana han creat acumulacions de neu ventada superiors als 50 cm. La pluja ha humidificat el mantell, l´ha regelat i compactat per sota dels 2.200 metres. Per sobre d´aquesta cota hi ha grans acumulacions de neu, sobretot als peus de les parets rocoses. En altura hi ha menys neu a causa del vent, però en algunes collades hi ha grans congestes que poden dificultar l´accés.

COMAPEDROSA

A cotes baixes la neu s´ha compactat i ha reduït el seu gruix a causa de l´humidificació. Per sobre del Pla de l´Estany i del refugi del Comapedrosa haurem de circular amb cautela, ja que als vessants amb component est poden haver-hi plaques de vent sensibles a sobrecàrregues.

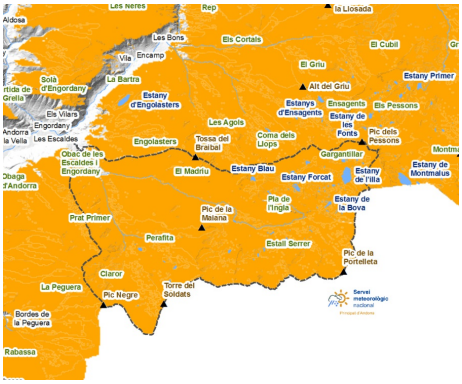

MADRIU-PERAFITA-CLAROR

Als vessants est s´hi ha de circular amb molta cautela, ja que és on hi ha les acumulacions de neu ventada més importants i perilloses. A la resta de vessants, a cotes baixes trobarem una neu ben compactada mentre a cotes altes els vent haurà deixat la neu dura al descobert.

BUTLLETÍ DEL PERILL D'ALLAUS DEL PRINCIPAT D'ANDORRA

Servei meteorològic nacional
Principat d'Andorra

Gruixos de neu nova dels darrers dies (de les últimes 24h mesurat a les 06:00h UTC)

	14/02/2026	15/02/2026	16/02/2026	17/02/2026
FEDA (Central)	0 cm	0 cm	0 cm	0 cm
Engolasters - FEDA	3 cm	0 cm	0 cm	0 cm
Bony de les Neres	0 cm	0 cm	0 cm	0 cm
Sorteny	0 cm	2 cm	6 cm	0 cm
Les Fonts d'Arinsal	0 cm	0 cm	0 cm	0 cm
Perafita	12 cm	0 cm	0 cm	0 cm
Tossa Espiolets	3 cm	0 cm	0 cm	0 cm
Grau Roig - FEDA	0 cm	0 cm	0 cm	0 cm
Fontverd	13 cm	0 cm	0 cm	0 cm
Ransol - FEDA	2 cm	0 cm	0 cm	2 cm
Setúria	0 cm	0 cm	0 cm	0 cm
Caborreu	0 cm	4 cm	6 cm	0 cm
Envalira Antenes	8 cm	0 cm	0 cm	3 cm