BUTLLETÍ DEL PERILL D'ALLAUS DEL PRINCIPAT D'ANDORRA

Servei meteorològic nacional
Principat d'Andorra

Elaborado el 18/02/2026 16:00
Proxima actualización 19/02/2026 a las 16h

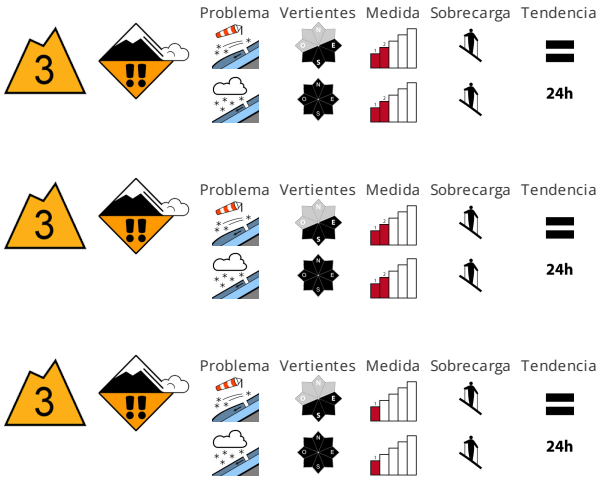

CALIDAD DE LA NIEVE

La nieve reciente y la nieve venteada deben ser evaluadas con cautela., especialmente en las laderas inclinadas orientadas a nordeste , sur y sudeste , y en las cubetas, canales y detrás de los cambios abruptos de pendiente. Los aludes pueden en algunos lugares ser desencadenadas al paso de un montañero y alcanzar un tamaño mediano. Los lugares peligrosos están parcialmente cubiertos de nieve reciente y resultan difíciles de reconocer con poca visibilidad. Se recomienda una elección cuidadosa de la ruta y mantener la distancia de seguridad entre los miembros del grupo.

ESTABILIDAD DEL MANTO NIVOSO

Sobre todo en el norte hasta el jueves caerán en algunos sectores hasta 30 cm de nieve por encima de los 1500 m aproximadamente, localmente hasta 30 cm. La nieve reciente del jueves se depositará encima de un manto de nieve antigua bastante favorable. Con la nieve reciente y el viento las placas de viento aumentarán de tamaño adicionalmente. Esta nieve debe ser evaluada con cautela. Los espesores de nieve varían mucho por encima de los 2600 m aproximadamente por la influencia del viento.

ESPESORES DEL MANTO NIVOSO FUERA DE PISTA

Zona norte		Espesor nieve		
Manto Nival		1500m	2000m	2500m
N	1300 m	50 cm	150 cm	200 cm
S	1500 m	0 cm	100 cm	150 cm

zona centro		Espesor nieve		
Manto Nival		1500m	2000m	2500m
N	1300 m	30 cm	150 cm	200 cm
S	1500 m	0 cm	100 cm	150 cm

Zona sur		Espesor nieve		
Manto Nival		1500m	2000m	2500m
N	1300 m	30 cm	120 cm	150 cm
S	1500 m	0 cm	60 cm	100 cm

Govern d'Andorra

EAWS
EUROPEAN AVALANCHE WARNING SERVICES

Aquest butlletí ha estat elaborat seguint les normes i recomanacions de l'**European Avalanche Warning Services**, del qual el **Servei meteorològic Nacional** n'és membre

Información detallada por espacios naturales protegidos

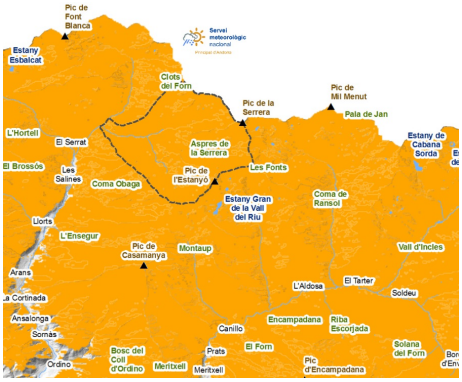

SORTENY

Las nevadas del fin de semana han creado acumulaciones de nieve venteada superiores a los 50 cm. La lluvia ha humidificado el manto, lo ha rehelado y compactado por debajo de los 2.200 metros. Por encima de esta cota existen grandes acumulaciones de nieve, sobre todo a los pies de las paredes rocosas. En altura hay menos nieve a causa del viento, pero en algunos collados hay grandes congestos que pueden dificultar el acceso.

COMAPEDROSA

En cotas bajas la nieve se ha compactado y ha reducido su grosor debido a la humidificación. Por encima del Pla de l ´Estany y del refugio del Comapedrosa deberemos circular con cautela, ya que en las laderas con componente este pueden haber placas de viento sensibles a sobrecargas.

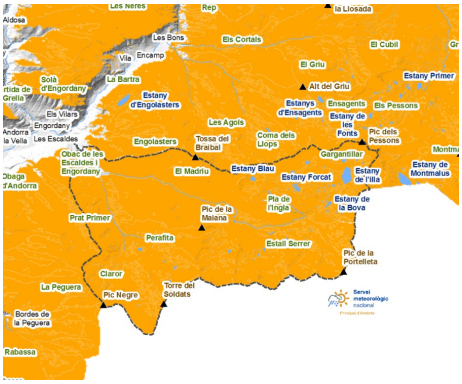

MADRIU-PERAFITA-CLAROR

En las vertientes este se debe circular con mucha cautela, ya que es donde están las acumulaciones de nieve venteada más importantes y peligrosas. En el resto de vertientes, en cotas bajas encontraremos una nieve bien compactada mientras en cotas altas el viento habrá dejado la nieve dura al descubierto.

BUTLLETÍ DEL PERILL D'ALLAUS DEL PRINCIPAT D'ANDORRA

Servei meteorològic nacional
Principat d'Andorra

Espesores de nieve nueva de los últimos días (de las ultimas 24h mesurado a las 06:00h UTC)

	14/02/2026	15/02/2026	16/02/2026	17/02/2026
FEDA (Central)	0 cm	0 cm	0 cm	0 cm
Engolasters - FEDA	3 cm	0 cm	0 cm	0 cm
Bony de les Neres	0 cm	0 cm	0 cm	0 cm
Sorteny	0 cm	2 cm	6 cm	0 cm
Les Fonts d'Arinsal	0 cm	0 cm	0 cm	0 cm
Perafita	12 cm	0 cm	0 cm	0 cm
Tossa Espiolets	3 cm	0 cm	0 cm	0 cm
Grau Roig - FEDA	0 cm	0 cm	0 cm	0 cm
Fontverd	13 cm	0 cm	0 cm	0 cm
Ransol - FEDA	2 cm	0 cm	0 cm	2 cm
Setúria	0 cm	0 cm	0 cm	0 cm
Caborreu	0 cm	4 cm	6 cm	0 cm
Envalira Antenes	8 cm	0 cm	0 cm	3 cm