BUTLLETÍ DEL PERILL D'ALLAUS DEL PRINCIPAT D'ANDORRA

Servei meteorològic nacional
Principat d'Andorra

Préparé le 18/02/2026 16:00
Prochaine mise à jour le 19/02/2026 à 16h

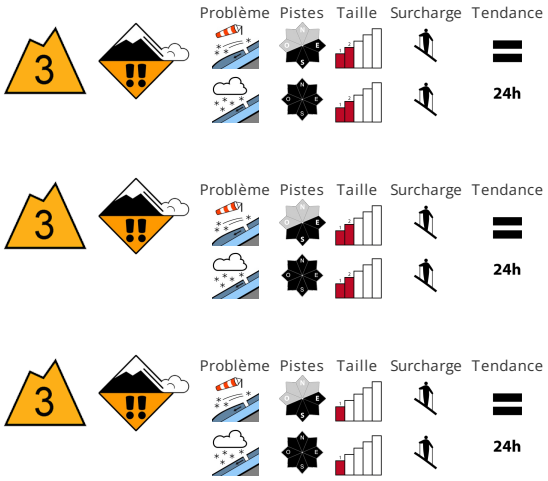

STABILITÉ DU MANTEAU NEIGEUX

La neige fraîche et la neige soufflée doivent être évaluées avec précaution. , surtout sur les pentes raides exposées au nord-est , au sud et au sud-est comme dans les combes, couloirs et derrière les ruptures de terrain. Des avalanches peuvent par endroits être déchaîné par un seul amateur de sports d'hiver et atteindre une taille moyenne.. Les endroits dangereux sont en partie couverts de neige fraîche, et à peine identifiables par mauvaise visibilité.. Un choix prudent d'itinéraire et des distances de délestage sont recommandés..

QUALITÈ DE LA NEIGE

Jusqu'à jeudi il tombera surtout au nord au-dessus d'environ 1500 m par régions jusqu'à 30 cm de neige , localement jusqu'à 30 cm.. La neige fraîche de jeudi se déposera sur une couche assez favorable de neige ancienne. Les accumulations de neige soufflée se développent encore avec la neige fraîche et le vent. Elle doit être évaluée avec précaution. On trouve suivant l'influence du vent des hauteurs de neiges très différentes au-dessus d'environ 2600 m.

EPAISSEUR DE NEIGE HORS PISTE

Zone nord		Epaisseur de neige		
Nival manteau		1500m	2000m	2500m
N	1300 m	50 cm	150 cm	200 cm
S	1500 m	0 cm	100 cm	150 cm

Zone centre		Epaisseur de neige		
Nival manteau		1500m	2000m	2500m
N	1300 m	30 cm	150 cm	200 cm
S	1500 m	0 cm	100 cm	150 cm

Zone sud		Epaisseur de neige		
Nival manteau		1500m	2000m	2500m
N	1300 m	30 cm	120 cm	150 cm
S	1500 m	0 cm	60 cm	100 cm

Govern d'Andorra

EAWS
EUROPEAN AVALANCHE WARNING SERVICES

Aquest butlletí ha estat elaborat seguint les normes i recomanacions de l'**European Avalanche Warning Services**, del qual el **Servei meteorològic Nacional** n'és membre

BUTLLETÍ DEL PERILL D'ALLAUS DEL PRINCIPAT D'ANDORRA

Servei meteorològic nacional
Principat d'Andorra

Des informations détaillées par espace naturel protégé

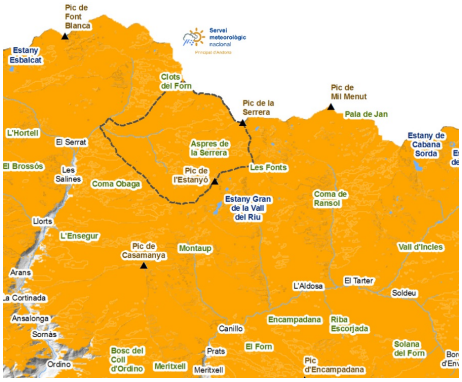

SORTENY

Les chutes de neige du week-end ont créé des accumulations de poudrerie dépassant les 50 cm. La pluie a humidifié le manteau, l'a gelé et l'a compacté en dessous de 2 200 mètres. Au-dessus de ce niveau, on trouve de grandes accumulations de neige, surtout au pied des parois rocheuses. À des altitudes plus élevées, il y a moins de neige à cause du vent, mais dans certains cols, il y a de grandes congères qui peuvent rendre l'accès difficile. , , , , , , ,

COMAPEDROSA

À basse altitude, la neige s'est compactée et a réduit son épaisseur en raison de l'humidification. Au-dessus du Pla de l'Estany et du refuge Comapedrosa, nous devrons rouler avec prudence, car il peut y avoir des plaques de vent sensibles aux surcharges sur les pentes à composante est. , , ,

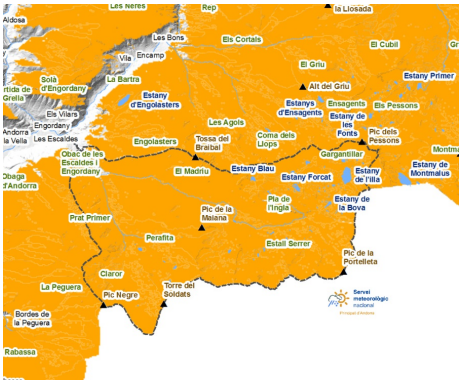

MADRIU-PERAFITA-CLAROR

Les pentes orientales doivent être parcourues avec beaucoup de prudence, car c'est là que se trouvent les accumulations de neige soufflée les plus importantes et les plus dangereuses. Sur le reste des pistes, à basse altitude, nous trouverons de la neige bien compactée, tandis qu'à haute altitude, le vent aura laissé la neige dure exposée. , , ,

Govern d'Andorra

EAWS
EUROPEAN AVALANCHE WARNING SERVICES

Aquest butlletí ha estat elaborat seguint les normes i recomanacions de l'**European Avalanche Warning Services**, del qual el **Servei meteorològic Nacional** n'és membre

BUTLLETÍ DEL PERILL D'ALLAUS DEL PRINCIPAT D'ANDORRA

Servei meteorològic nacional
Principat d'Andorra

Couche de neige fraiche des derniers jours (De 24 h mesurée à 06:00 h UTC)

	14/02/2026	15/02/2026	16/02/2026	17/02/2026
FEDA (Central)	0 cm	0 cm	0 cm	0 cm
Engolasters - FEDA	3 cm	0 cm	0 cm	0 cm
Bony de les Neres	0 cm	0 cm	0 cm	0 cm
Sorteny	0 cm	2 cm	6 cm	0 cm
Les Fonts d'Arinsal	0 cm	0 cm	0 cm	0 cm
Perafita	12 cm	0 cm	0 cm	0 cm
Tossa Espiolets	3 cm	0 cm	0 cm	0 cm
Grau Roig - FEDA	0 cm	0 cm	0 cm	0 cm
Fontverd	13 cm	0 cm	0 cm	0 cm
Ransol - FEDA	2 cm	0 cm	0 cm	2 cm
Setúria	0 cm	0 cm	0 cm	0 cm
Caborreu	0 cm	4 cm	6 cm	0 cm
Envalira Antenes	8 cm	0 cm	0 cm	3 cm