MINISTERO DELLA DIFESA

meteomont
Servizio Nazionale di previsione neve e valanghe

EAWS EUROPEAN AVALANCHE WARNING SERVICES

CARABINIERI

AERONAUTICA MILITARE SERVIZIO METEOROLOGICO

ALPI GIULIE

Bollettino Valanghe N. 350/2026 del 18/02/2026 ore 14.00
Validità 48 ore prossima emissione 19/02/2026

A cura del Servizio METEOMONT dell'ARMA dei CARABINIERI
In collaborazione con Servizio Meteorologico dell'Aeronautica militare

SITUAZIONE alle 14:00 del 18/02/2026

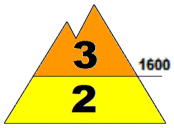

SITUAZIONE TIPO: neve a debole coesione e vento.

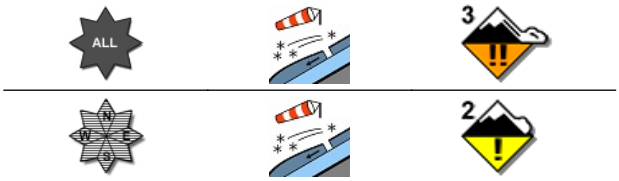

SITUAZIONE TIPO: neve a debole coesione e vento.

Quota neve (mslm)	Nord	Sud
	800 - 900	1300

Altezza Neve (cm)	Neve al suolo	Neve Fresca	Quota (mslm)
	117	005	1750
	43	00	872

VALANGHE OSSERVATE: Nessuna valanga.

PREVISIONI 19/02/2026

GRADO DI PERICOLO: FORTE 4

SITUAZIONE TIPO: neve a debole coesione e vento.



SITUAZIONE TIPO: neve a debole coesione e vento.

MANTO NEVOSO: La stabilità del manto nevoso è scarsa su molti punti (aree) per tutte le esposizioni al di sopra di 1600 mslm, possibili valanghe di dimensioni grandi.
La stabilità del manto nevoso è scarsa su alcuni punti (aree) per tutte le esposizioni al di sotto di 1600 mslm, possibili valanghe di dimensioni medie.

AVVERTENZE

In considerazione dei recenti apporti di neve fresca, è richiesta un'ottima valutazione locale della stabilità ed individuazione dell'itinerario.

SCALA EUROPEA DEL GRADO DI PERICOLO VALANGHE

5 - MOLTO FORTE — *4 - FORTE* — *3 - MARCATO* — *2 - MODERATO* — *1 - DEBOLE* — NO NEVE *NO NEVE* — *NO INFO*

LEGENDA PROBLEMA

NEVE FRESCA — *LASTRONI DA VENTO* — *STRATI DEBOLI PERSISTENTI* — *NEVE BAGNATA* — *SLITTAMENTO* — *CORNICI* — *NESSUN PROBLEMA VALANGHIVO EVIDENTE* — *NO_INFO*

Bollettino realizzato su scala sinottica-regionale (standard EAWS). La sua valutazione non può escludere in alcun modo la necessità di una seria e capace valutazione locale del pericolo (singolo pendio) che può essere anche sensibilmente diverso. Le previsioni meteorologiche sono relative all'orario UTC (per l'Italia +1 in inverno e +2 in estate).

Bollettino sottoposto a processi di: Acquisizione e controllo del C-Sifa e della rete di Osservatori e Esperti - Validazione del Previsore di turno - Certificazione della Sezione Meteomont.

ALPI GIULIE

PREVISIONE METEO

Quota		19/02/2026 h6:00	19/02/2026 h12:00	19/02/2026 h18:00
1000	Venti	01 Nodi da S-Ovest	02 Nodi da Est	01 Nodi da Ovest
	Temperature	+01 °C	+01 °C	+00 °C
	Temp.percepita	1 °C	1 °C	0 °C
2000	Venti	07 Nodi da Sud	09 Nodi da Sud	03 Nodi da Sud
	Temperature	-03 °C	-03 °C	-04 °C
	Temp.percepita	-8 °C	-8 °C	-6 °C
3000	Venti	20 Nodi da S-Ovest	27 Nodi da Sud	10 Nodi da Sud
	Temperature	-08 °C	-07 °C	-11 °C
	Temp.percepita	-18 °C	-18 °C	-19 °C
Zero termico		1000-1200 m.	1100-1300 m.	0800-1000 m.
Fenomeno				
Stato del cielo				

LEGENDA FENOMENI

Assenza Fenomeni — Nebbia — Foschia — Pioggia debole — Pioggia moderata — Pioggia forte — Temporali

Nevicata debole — Nevicata moderata — Nevicata forte

STATO DEL CIELO

Sereno — Poco nuvoloso — Nuvoloso — Molto nuvoloso — Coperto

Parametri meteonivometrici registrati presso i campi di rilevamento il 18/02/2026.

Località	Comune	Quota (m.s.l.m.)	Altezza neve (cm)	Neve caduta nelle 24 ore (cm)	Temp. Min (°C)	Temp. Max (°C)	Condizioni del tempo
MALBORGHETTO - VAL SAISERA	Tarvisio (UD)	875	43	0	-7	+7	Assenza di precipitazioni
PASSO PRAMOLLO	Pontebba (UD)	1530	120	0	-12	+5	Assenza di precipitazioni
MONTE LUSSARI	Tarvisio (UD)	1750	117	0	-9	+6	Assenza di precipitazioni
PASSO PREDIL	Tarvisio (UD)	1130	72	0	-7	+4	Assenza di precipitazioni

(*) Rilievi fuori campo

L'INFORMAZIONE E' PREVENZIONE - LEGGI L'ATTUALE GRADO DI PERICOLO VALANGHE!

IL CAPO DEL CENTRO NAZIONALE METEOMONT
(Ten. Col. RFI Emanuela Gini)
FIRMA AUTOGRAFA OMESSA AI SENSI
DELL'ART.3 DEL D.LGS N.39/1993

Bollettino realizzato su scala sinottica-regionale (standard EAWS). La sua valutazione non può escludere in alcun modo la necessità di una seria e capace valutazione locale del pericolo (singolo pendio) che può essere anche sensibilmente diverso. Le previsioni meteorologiche sono relative all'orario UTC (per l'Italia +1 in inverno e +2 in estate).