MINISTERO DELLA DIFESA

meteomont Servizio Nazionale di previsione neve e valanghe

EAWS EUROPEAN AVALANCHE WARNING SERVICES

CARABINIERI

In collaborazione con: arpav

PREALPI

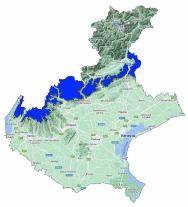

Bollettino Valanghe N. 346/2026 del 18/02/2026 ore 14.00
Validità 48 ore prossima emissione 19/02/2026

A cura del Servizio METEOMONT dell'ARMA dei CARABINIERI
In collaborazione con Servizio Meteorologico dell'Aeronautica militare

SITUAZIONE alle 14:00 del 18/02/2026

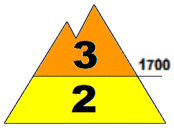

SITUAZIONE TIPO: neve a debole coesione e vento.

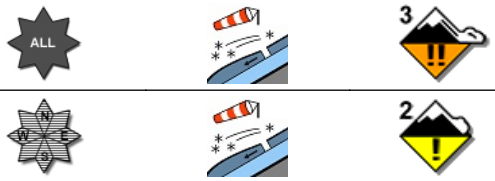

SITUAZIONE TIPO: neve a debole coesione e vento.

Quota neve (mslm)	Nord	Sud
	1000 - 1200	1400

Altezza Neve (cm)	Neve al suolo	Neve Fresca	Quota (mslm)
	65	00	2236
	111	000	1488

VALANGHE OSSERVATE: Valanghe di piccole dimensioni, I due tipi di valanghe di neve di superficie.

PREVISIONI 19/02/2026

GRADO DI PERICOLO: MARCATO 3

SITUAZIONE TIPO: neve a debole coesione e vento.

SITUAZIONE TIPO: neve a debole coesione e vento.

MANTO NEVOSO: La stabilità del manto nevoso è molto scarsa su molti punti (aree) per tutte le esposizioni al di sopra di 1700 mslm, possibili valanghe di dimensioni medie.
La stabilità del manto nevoso è scarsa su pochi punti (aree) per tutte le esposizioni al di sotto di 1700 mslm, possibili valanghe di dimensioni medie.

AVVERTENZE

A seguito dell'attività eolica registrata sono da evitare le zone di accumulo, conche, canaloni, cambi di pendenza e pendii sotto vento in genere.

SCALA EUROPEA DEL GRADO DI PERICOLO VALANGHE

LEGENDA PROBLEMA

Bollettino realizzato su scala sinottica-regionale (standard EAWS). La sua valutazione non può escludere in alcun modo la necessità di una seria e capace valutazione locale del pericolo (singolo pendio) che può essere anche sensibilmente diverso. Le previsioni meteorologiche sono relative all'orario UTC (per l'Italia +1 in inverno e +2 in estate).

PREALPI

PREVISIONE METEO

Quota		19/02/2026 h6:00	19/02/2026 h12:00	19/02/2026 h18:00
1000	Venti	03 Nodi da N-Est	01 Nodi da Nord	02 Nodi da N-Est
	Temperature	-01 °C	+00 °C	+01 °C
	Temp.percepita	-3 °C	0 °C	1 °C
2000	Venti	10 Nodi da Sud	03 Nodi da S-Est	07 Nodi da Nord
	Temperature	-02 °C	-04 °C	-02 °C
	Temp.percepita	-8 °C	-6 °C	-6 °C
3000	Venti	21 Nodi da Sud	06 Nodi da Sud	16 Nodi da Nord
	Temperature	-06 °C	-09 °C	-09 °C
	Temp.percepita	-15 °C	-14 °C	-18 °C
Zero termico		0800-1000 m.	0900-1100 m.	1500-1700 m.
Fenomeno				
Stato del cielo				

LEGENDA FENOMENI

Assenza Fenomeni — Nebbia — Foschia — Pioggia debole — Pioggia moderata — Pioggia forte — Temporali

Nevicata debole — Nevicata moderata — Nevicata forte

STATO DEL CIELO

Sereno — Poco nuvoloso — Nuvoloso — Molto nuvoloso — Coperto

Parametri meteonivometrici registrati presso i campi di rilevamento il 18/02/2026.

Località	Comune	Quota (m.s.l.m.)	Altezza neve (cm)	Neve caduta nelle 24 ore (cm)	Temp. Min (°C)	Temp. Max (°C)	Condizioni del tempo
MONTE BALDO	Malcesine (VR)	1828	105	0	N.P.	N.P.	Assenza di precipitazioni
PIAN CANTON	Tambre (BL)	1280	16	0	-4	+7	Assenza di precipitazioni
MONTE GUSLON *	Chies d'Alpago (BL)	2236	65	0	N.P.	N.P.	Assenza di precipitazioni
SENGIO ALTO - MALGA BOVENTAL *	Vallarsa (TN)	1488	111	0	N.P.	N.P.	Assenza di precipitazioni

(*) Rilievi fuori campo

L'INFORMAZIONE E' PREVENZIONE - LEGGI L'ATTUALE GRADO DI PERICOLO VALANGHE!

IL CAPO DEL CENTRO NAZIONALE METEOMONT
(Ten. Col. RFI Emanuela Gini)
FIRMA AUTOGRAFA OMESSA AI SENSI
DELL'ART.3 DEL D.LGS N.39/1993

Bollettino realizzato su scala sinottica-regionale (standard EAWS). La sua valutazione non può escludere in alcun modo la necessità di una seria e capace valutazione locale del pericolo (singolo pendio) che può essere anche sensibilmente diverso. Le previsioni meteorologiche sono relative all'orario UTC (per l'Italia +1 in inverno e +2 in estate).