MINISTERO DELLA DIFESA

meteomont Servizio Nazionale di previsione neve e valanghe

EAWS EUROPEAN AVALANCHE WARNING SERVICES

CARABINIERI

ALPI RETICHE

Bollettino Valanghe N. 351/2026 del 18/02/2026 ore 14.00
Validità 48 ore prossima emissione 19/02/2026

A cura del Servizio METEOMONT dell'ARMA dei CARABINIERI
In collaborazione con Servizio Meteorologico dell'Aeronautica militare

SITUAZIONE alle 14:00 del 18/02/2026

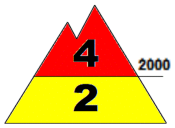

SITUAZIONE TIPO: neve a debole coesione e vento.

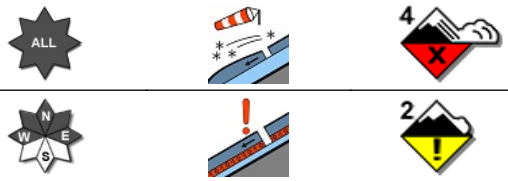

SITUAZIONE TIPO: strato debole persistente basale.

Quota neve (mslm)	Nord	Sud
	900 - 1000	1200 - 1500

Altezza Neve (cm)	Neve al suolo	Neve Fresca	Quota (mslm)
	127	20	2407
	058	0	1640

VALANGHE OSSERVATE: Alcune valanghe di dimensioni molto grandi, I due tipi di valanghe di neve di fondo.

PREVISIONI 19/02/2026

GRADO DI PERICOLO: FORTE 4

SITUAZIONE TIPO: neve a debole coesione e vento.

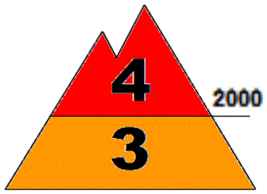

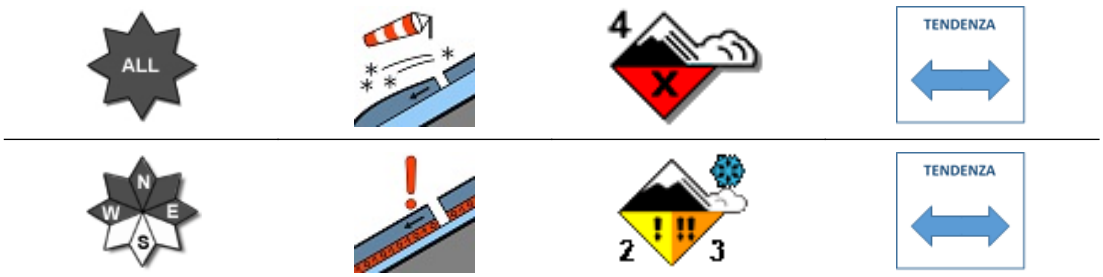

SITUAZIONE TIPO: strato debole persistente basale.

MANTO NEVOSO: La stabilità del manto nevoso è molto scarsa su molti punti (aree) per tutte le esposizioni al di sopra di 2000 mslm, possibili valanghe di dimensioni grandi.
La stabilità del manto nevoso è scarsa su molti punti (aree) per versanti da ovest a est al di sotto di 2000 mslm, possibili valanghe di dimensioni medie.

AVVERTENZE

In considerazione delle avverse condizioni meteorologiche previste , le attività al di fuori delle piste battute e segnalate sono sconsigliate.

SCALA EUROPEA DEL GRADO DI PERICOLO VALANGHE

LEGENDA PROBLEMA

Bollettino realizzato su scala sinottica-regionale (standard EAWS). La sua valutazione non può escludere in alcun modo la necessità di una seria e capace valutazione locale del pericolo (singolo pendio) che può essere anche sensibilmente diverso. Le previsioni meteorologiche sono relative all'orario UTC (per l'Italia +1 in inverno e +2 in estate).

MINISTERO DELLA DIFESA

meteomont
Servizio Nazionale di previsione neve e valanghe

EAWS EUROPEAN AVALANCHE WARNING SERVICES

CARABINIERI

ALPI RETICHE

PREVISIONE METEO

Quota		19/02/2026 h6:00	19/02/2026 h12:00	19/02/2026 h18:00
1000	Venti	02 Nodi da N-Est	01 nodi da N-Ovest	02 nodi da N-Ovest
	Temperature	-05 °C	-03 °C	-02 °C
	Temp.percepita	-5 °C	-3 °C	-2 °C
2000	Venti	02 Nodi da N-Est	01 nodi da N-Ovest	02 nodi da N-Ovest
	Temperature	-05 °C	-03 °C	-02 °C
	Temp.percepita	-5 °C	-3 °C	-2 °C
3000	Venti	10 Nodi da Sud	10 Nodi da Nord	13 Nodi da Nord
	Temperature	-09 °C	-10 °C	-10 °C
	Temp.percepita	-16 °C	-18 °C	-19 °C
Zero termico		1100-1300 m.	1500-1700 m.	1600-1800 m.
Fenomeno				—
Stato del cielo				

LEGENDA FENOMENI

— Assenza Fenomeni
Nebbia
Foschia
Pioggia debole
Pioggia moderata
Pioggia forte
Temporali
Nevicata debole
Nevicata moderata
Nevicata forte

STATO DEL CIELO

Sereno
Poco nuvoloso
Nuvoloso
Molto nuvoloso
Coperto

Parametri meteonivometrici registrati presso i campi di rilevamento il 18/02/2026.

Località	Comune	Quota (m.s.l.m.)	Altezza neve (cm)	Neve caduta nelle 24 ore (cm)	Temp. Min (°C)	Temp. Max (°C)	Condizioni del tempo
SPONDA	Livigno (SO)	2150	83	0	-15	+1	Assenza di precipitazioni
BORMIO2000-LECCIONA	Valdisotto (SO)	2050	68	1	-10	-3	Assenza di precipitazioni
VALAR	Valdidentro (SO)	1930	76	9	-15	+0	Assenza di precipitazioni
DOSSO DEL VALLONE	Valfurva (SO)	2582	70	6	N.P.	N.P.	Assenza di precipitazioni
COREN DI CASPOI *	Vezza d'Oglio (BS)	1815	24	6	N.P.	N.P.	Assenza di precipitazioni
ALPE PALU'	Chiesa in Valmalenco (SO)	2010	79	4	-11	-1	Assenza di precipitazioni
COLONIA VIGILI	Ponte di Legno (BS)	1640	58	Tracce di neve	-9	0	Assenza di precipitazioni
PARÉ DI LIVIGNO *	Livigno (SO)	2113	87	20	N.P.	N.P.	Assenza di precipitazioni
COSTACCIA *	Livigno (SO)	2407	127	20	N.P.	N.P.	Assenza di precipitazioni

(*) Rilievi fuori campo

L'INFORMAZIONE E' PREVENZIONE - LEGGI L'ATTUALE GRADO DI PERICOLO VALANGHE!

IL CAPO DEL CENTRO NAZIONALE METEOMONT
(Ten. Col. RFI Emanuela Gini)
FIRMA AUTOGRAFA OMESSA AI SENSI
DELL'ART.3 DEL D.LGS N.39/1993

Bollettino realizzato su scala sinottica-regionale (standard EAWS). La sua valutazione non può escludere in alcun modo la necessità di una seria e capace valutazione locale del pericolo (singolo pendio) che può essere anche sensibilmente diverso. Le previsioni meteorologiche sono relative all'orario UTC (per l'Italia +1 in inverno e +2 in estate).