Bulletin d'estimation du risque d'avalanche

(valable en dehors des pistes balisées et ouvertes)

MASSIF : Cerdagne Canigou

Rédigé le mercredi 18 février 2026 à 16h

Estimation des risques pour le : JEUDI 19 FÉVRIER

PERSISTANCE DE STRUCTURES DE PLAQUES EN ALTITUDE

3

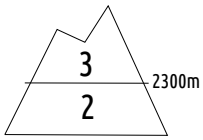

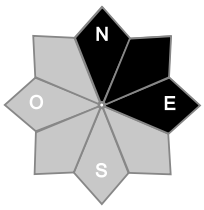

Au-dessus de 2300m indice de risque marqué, plus bas indice limité.

Départs spontanés : Peu probables

Déclenchements provoqués : Plaques à vent en altitude en place, nouvelles structures possibles jeudi en journée

Indices de risque : 5 très fort - 4 fort - 3 marqué - 2 limité - 1 faible -- En noir : les pentes les plus dangereuses

Stabilité du manteau neigeux

Situation avalancheuse typique : neige ventée

Déclenchements provoqués :
En altitude, au-dessus de 2200 à 2400m en général, des structures de plaques souvent dures, mais parfois friables, se sont formées ces derniers jours sous le vent de nord-ouest. Elles sont surtout présentes dans un large secteur nord à est et pourront conduire à des avalanches de moyenne taille (T2). Les nouvelles chutes de neige attendues sont faibles mais le vent associé pourra favoriser la formation de nouvelles structures friables pouvant céder facilement au passage d'un skieur ou randonneur.
Observables : zone d'accumulations sous le vent, neige travaillée par le vent en surface, traces de montée disparaissant rapidement (chasse-neige).

Départs spontanés :Peu probables.
La baisse des températures limite fortement le risque de départ en neige humide et les nouvelles chutes attendues semblent trop faibles pour provoquer autre chose que des petites coullées de surface dans les pentes raides sans conséquence.

Qualité de la neige

Enneigement :
L'enneigement reste largement supérieur à celui des cinq dernières années et se situe à niveau remarquable par rapport aux statistiques plus anciennes. L'enneigement débute vers 1500m et devient rapidement conséquent avec l'altitude. La barre des 2m de neige est souvent atteinte dès 2000m d'altitude. Les petites chutes de neige attendues ne modifient pas significativement ce constat.

État de la neige :
On peut trouver une fine couche de neige fraîche jeudi matin reposant sur un manteau compact de type printanier jusqu'à 2200m en versant nord et souvent jusqu'aux sommets en versants ensoleillés.
À partir de 2200m, on pourra trouver un peu plus de neige froide et sèche dans les vallons et secteurs abrités du vent, une neige très travaillée par le vent ailleurs. Les crêtes et sommets peuvent se retrouver décapés par le vent violent.

Aperçu météo pour le jeudi 19 février

	nuit	matin	après-midi	soir
Vent fort, quelques chutes de neige débordant de l'Ariège				
Pluie-Neige	1 600 m	1 000 m	1 300 m	
Iso 0 °C	2 500 m	1 600 m	2 000 m	1 900 m
Vent 2000 m	↘ 50 km/h	→ 65 km/h	→ 80 km/h	↘ 90 km/h
Vent 3000 m	→ 75 km/h	↘ 95 km/h	↘ 110 km/h	↘ 120 km/h

Épaisseur de neige hors-piste

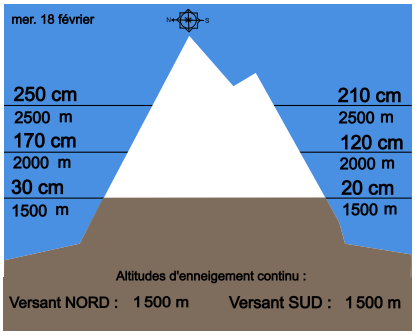

Précipitations à 1800 m

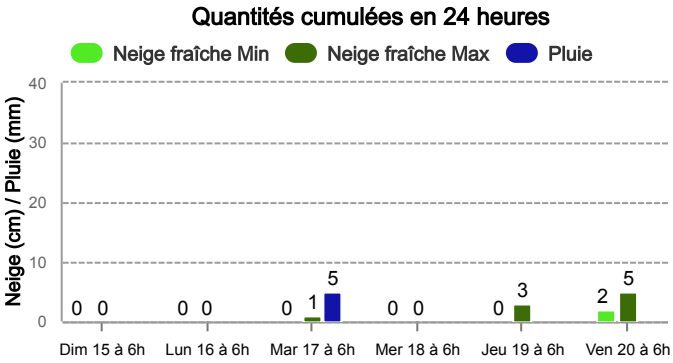

Tendance du vendredi 20 février

3 **Indice de risque marqué**

Maintient d'un risque marqué avec de nouvelles structures de plaque pouvant se former.

Pour consulter la vigilance en cours, veuillez vous rendre sur le site https://vigilance.meteofrance.fr/fr

Météo-France - 73 avenue de Paris, 94165 Saint-Mandé cedex - Contact : contact@meteo.fr

Rédigé par Météo-France avec la contribution des observateurs du réseau nivo-météorologiques. Partenariat : ANMSM (Maires de Stations de Montagne), DSF (Domaines Skiables de France), ADSP (Directeurs de Pistes et de la Sécurité des Stations de Sports d'Hiver) et autres acteurs de la montagne.

Bulletin neige & avalanches par téléphone au 0 892 68 10 20 Service 0,35 € / min + prix appel

RÉPUBLIQUE FRANÇAISE
Liberté Égalité Fraternité

METEO FRANCE
À VOS CÔTÉS, DANS UN CLIMAT QUI CHANGE

Bulletin d'estimation du risque d'avalanche
(valable en dehors des pistes balisées et ouvertes)
MASSIF : Cerdagne Canigou

Rédigé le mercredi 18 février 2026 à 16h

Conditions nivo-météo des 7 derniers jours

	jeu. 12/02				ven. 13/02				sam. 14/02				dim. 15/02				lun. 16/02				mar. 17/02				mer. 18/02			
	03h	09h	15h	21h	03h	09h	15h	21h	03h	09h	15h	21h	03h	09h	15h	21h	03h	09h	15h	21h	03h	09h	15h	21h	03h	09h	15h	21h
Météo																												
Vent (km/h)	90	120	115	80	75	85	60	90	90	90	100	100	95	60	65	65	95	100	105	120	120	110	90	75	65	55	70	80
à 3000m																												
Vent (km/h)	65	90	90	55	45	50	35	60	70	70	80	80	60	40	35	40	50	65	80	85	85	65	50	40	30	25	35	50
à 2000m																												

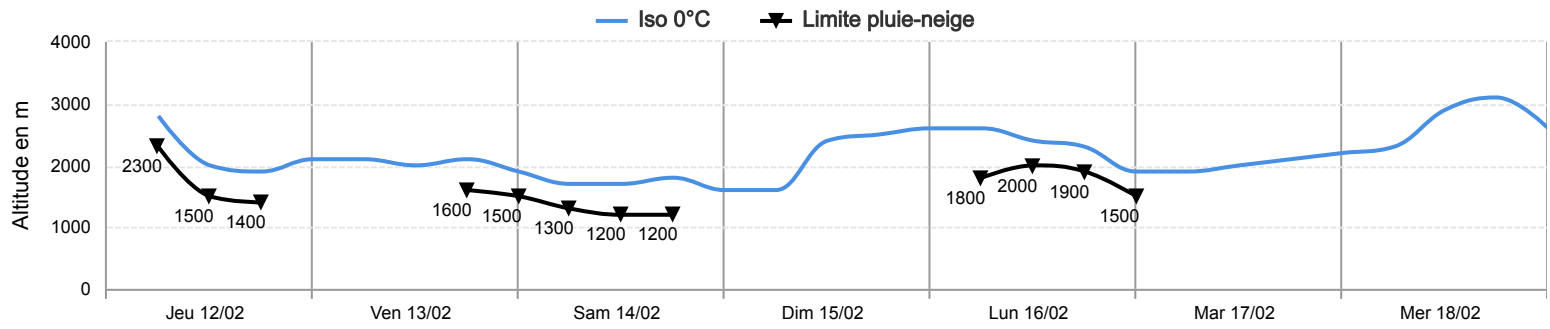

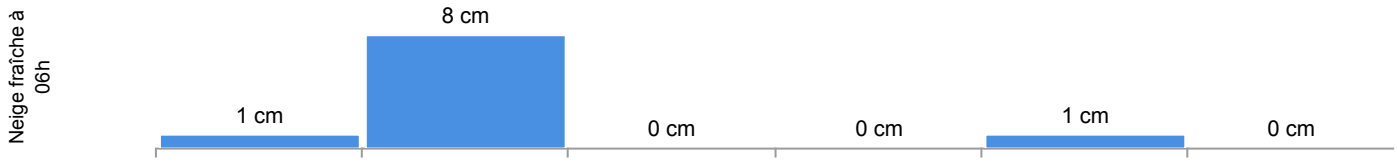

Risque d'avalanche	jeu. 12/02	ven. 13/02	sam. 14/02	dim. 15/02	lun. 16/02	mar. 17/02	mer. 18/02
	2	2	2	3	3	3	3

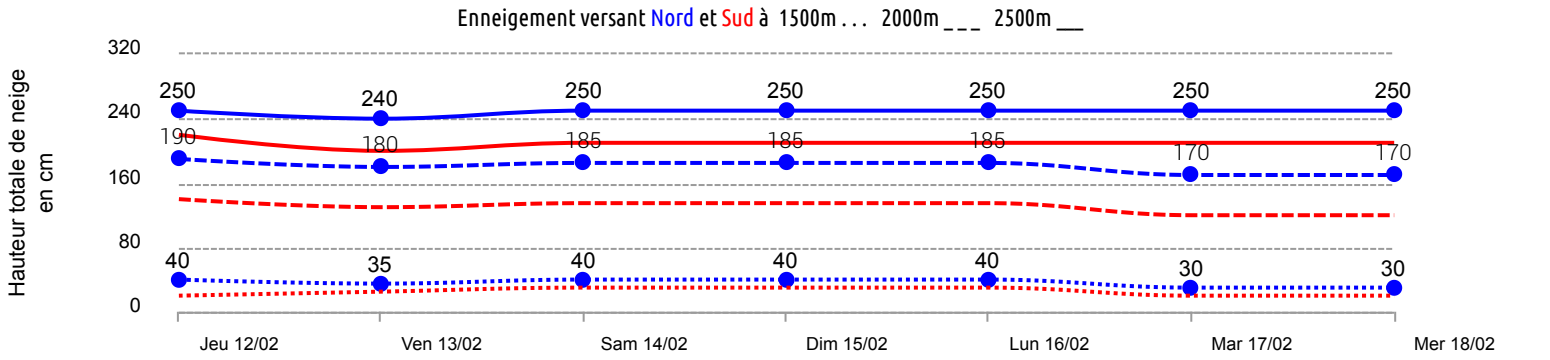

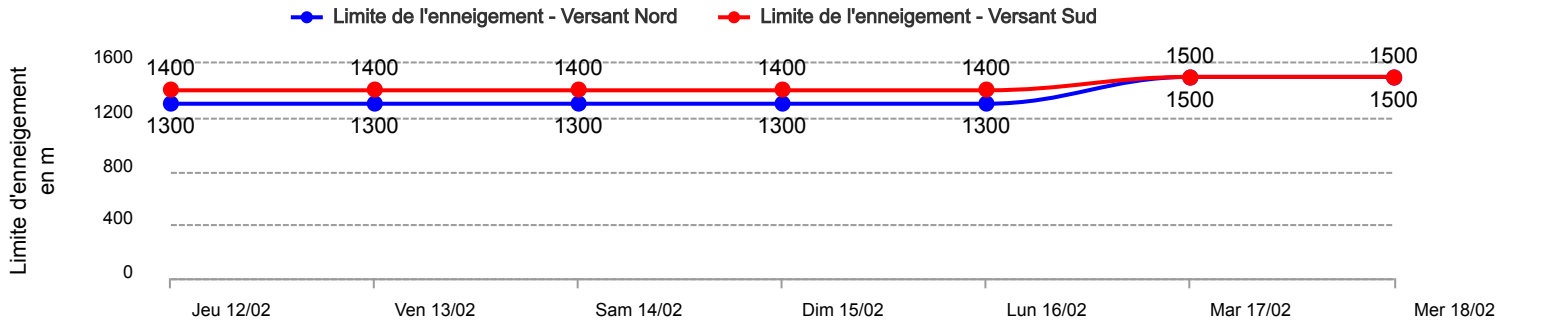

Pour consulter la vigilance en cours, veuillez vous rendre sur le site https://vigilance.meteofrance.fr/fr

Météo-France - 73 avenue de Paris, 94165 Saint-Mandé cedex - Contact : contact@meteo.fr

Bulletin neige & avalanches par téléphone au
0 892 68 10 20 Service 0,35 € / min + prix appel

Rédigé par Météo-France avec la contribution des observateurs du réseau nivo-météorologiques. Partenariat : ANMSM (Maires de Stations de Montagne), DSF (Domaines Skiables de France), ADSP (Directeurs de Pistes et de la Sécurité des Stations de Sports d'Hiver) et autres acteurs de la montagne.