Bulletin d'estimation du risque d'avalanche
(valable en dehors des pistes balisées et ouvertes)

MASSIF : Chablais

Rédigé le mercredi 18 février 2026 à 16h

Estimation des risques pour le : JEUDI 19 FÉVRIER

NOMBREUSES INSTABILITÉS DANS LE MANTEAU NEIGEUX, EN AUGMENTATION AU FIL DES CHUTES.

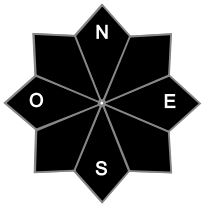

Indice de risque fort.

Départs spontanés : Nombreuses grandes avalanches, pouvant parcourir de grandes dénivellations.

Déclenchements provoqués : Risque maximal.

Indices de risque : 5 très fort - 4 fort - 3 marqué - 2 limité - 1 faible -- En noir : les pentes les plus dangereuses

Vigilance orange avalanches en cours ou prévue sur le massif

Stabilité du manteau neigeux

Situation avalancheuse typique : neige ventée couche fragile persistante

Départs spontanés :

Départs de plus en plus nombreux de grandes (taille 3) avalanches au fil des chutes. Départs de **plaques épaisses**, sur de **grandes largeurs,** au-dessus d'environ 1800 m. Ces avalanches peuvent parcourir de **grandes dénivellations**.

Facteur aggravant :

- en versants Est/Nord/Ouest : une couche fragile persistante enfouie peut être sollicitée, pouvant donner dans de rares cas une cassure de plus grosse épaisseur (grande avalanche, taille 4)
- plaques à vent épaisses formées par le vent de Nord-Ouest à Sud-Ouest ces derniers jours. Elles peuvent être déclenchées par surcharge des nouvelles chutes de neige. Une avalanche peut aussi partir au sol.

Déclenchements provoqués :

Risque accidentel maximal. Nombreuses plaques à vent formées dans la neige récente par le vent de Nord-Ouest à Sud-Ouest. Plus nombreuses au-dessus de 1800 m ou à proximité des crêtes/arêtes. De nouvelles plaques à vent se forment dans la neige fraîche. Cassures épaisses. **Taille 2 (moyenne) à 3 (grande).**

Facteur aggravant au dessus de 1800/2000 m en versants Est/Nord/Ouest : une couche fragile persistante enfouie peut être sollicitée et donner une avalanche de plus grande ampleur.

Qualité de la neige

Enneigement : Bon pour la saison à toutes altitudes grâce aux fréquentes chutes de neige du mois de février. On peut chausser les skis vers 1200 m dans tous les versants. L'épaisseur du manteau neigeux varie : nombreuses congères et corniches.

Qualité de la neige ce jeudi :

* Cumuls de neige fraîche le matin, tombé la nuit :
  - 5-10 cm vers 1000 m.
  - 10-15 cm vers 1500 m.
  - 15-25 cm au-dessus de 2000 m.

Au fil de la journée, l'épaisseur de neige fraîche augmente.

* Cette neige fraîche, ainsi que le manteau neigeux sur lequel elle tombe est travaillé par le vent de Nord-Ouest à Sud-Ouest : formations de congères et corniches, remplissage des combes.
* La sous-couche de neige est très meuble, l'enfoncement piéton est très important : supérieur à 1 m vers 2000 m d'altitude.

Aperçu météo pour le jeudi 19 février

	nuit	matin	après-midi	soir

Chutes de neige sur la nuit et la journée. Limite pluie-neige qui s'abaisse rapidement vers 1000 m. Vent fort en altitude.

	nuit	matin	après-midi	soir
Pluie-Neige	1 200 m	1 000 m	1 000 m	1 000 m
Iso 0 °C	1 400 m	1 300 m	1 300 m	1 300 m
Vent 2000 m	↗ 35 km/h	↗ 40 km/h	↗ 30 km/h	→ 25 km/h
Vent 2500 m	→ 50 km/h	→ 50 km/h	→ 40 km/h	→ 40 km/h

Épaisseur de neige hors-piste

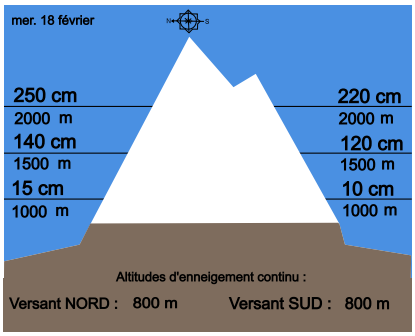

Précipitations à 1800 m

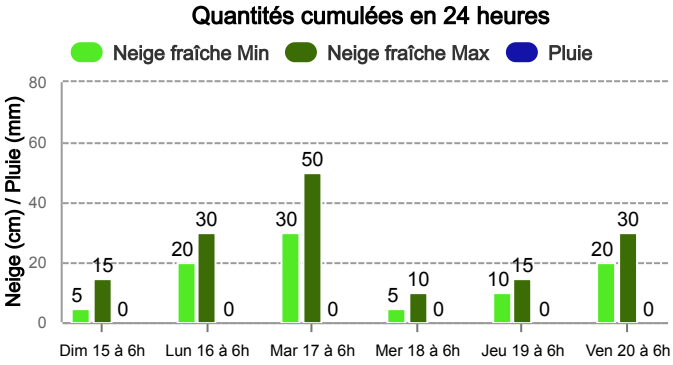

Tendance du vendredi 20 février

Indice de risque fort

Les instabilités du manteau neigeux sont toujours très nombreuses. Les chutes de neige continuent la nuit de jeudi à vendredi et plus faiblement en journée de vendredi, créant de nouvelles instabilités. Redoux en journée de vendredi.

Pour consulter la vigilance en cours, veuillez vous rendre sur le site https://vigilance.meteofrance.fr/fr

Météo-France - 73 avenue de Paris, 94165 Saint-Mandé cedex - Contact : contact@meteo.fr

Rédigé par Météo-France avec la contribution des observateurs du réseau nivo-météorologiques. Partenariat : ANMSM (Maires de Stations de Montagne), DSF (Domaines Skiables de France), ADSP (Directeurs de Pistes et de la Sécurité des Stations de Sports d'Hiver) et autres acteurs de la montagne.

Bulletin neige & avalanches par téléphone au **0 892 68 10 20** Service 0,35 € / min + prix appel

RÉPUBLIQUE FRANÇAISE
Liberté Égalité Fraternité

METEO FRANCE
À VOS CÔTÉS, DANS UN CLIMAT QUI CHANGE

Bulletin d'estimation du risque d'avalanche

(valable en dehors des pistes balisées et ouvertes)

MASSIF : Chablais

Rédigé le mercredi 18 février 2026 à 16h

Conditions nivo-météo des 7 derniers jours

	jeu. 12/02				ven. 13/02				sam. 14/02				dim. 15/02				lun. 16/02				mar. 17/02				mer. 18/02			
	03h	09h	15h	21h	03h	09h	15h	21h	03h	09h	15h	21h	03h	09h	15h	21h	03h	09h	15h	21h	03h	09h	15h	21h	03h	09h	15h	21h
Météo																												
Vent (km/h)	80	80	70	50	50	40	40	30	25	30	40	60	35	30	40	65	80	70	70	55	55	55	50	35	30	55	50	60
à 2500m																												
Vent (km/h)	55	50	50	40	40	30	30	20	10	20	30	45	20	15	25	50	60	55	55	45	45	40	40	25	20	45	40	50
à 2000m																												

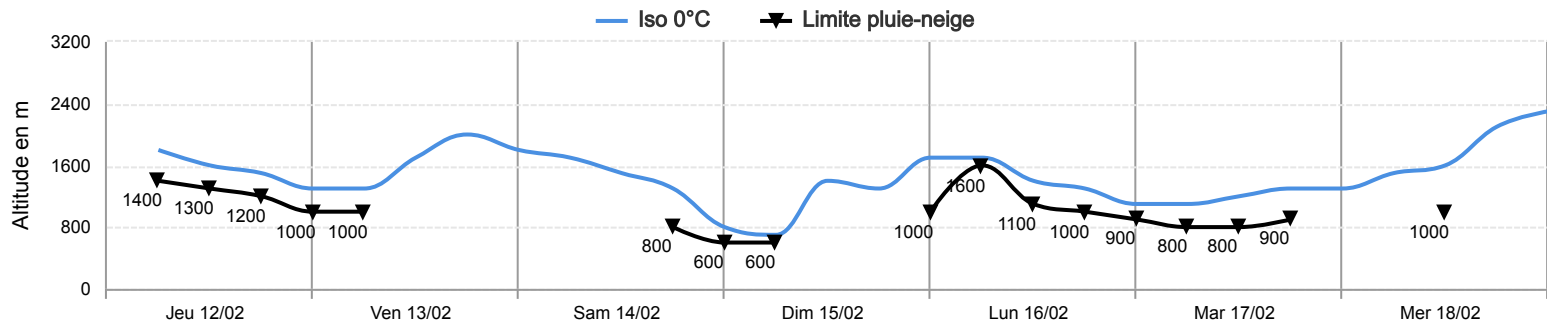

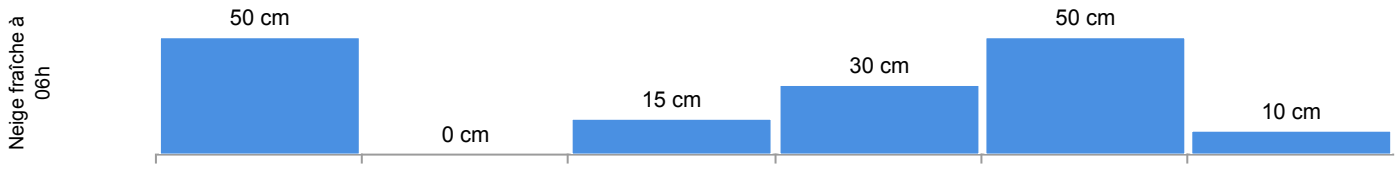

Risque d'avalanche	jeu. 12/02	ven. 13/02	sam. 14/02	dim. 15/02	lun. 16/02	mar. 17/02	mer. 18/02
	5	4	3	3	4	4	4

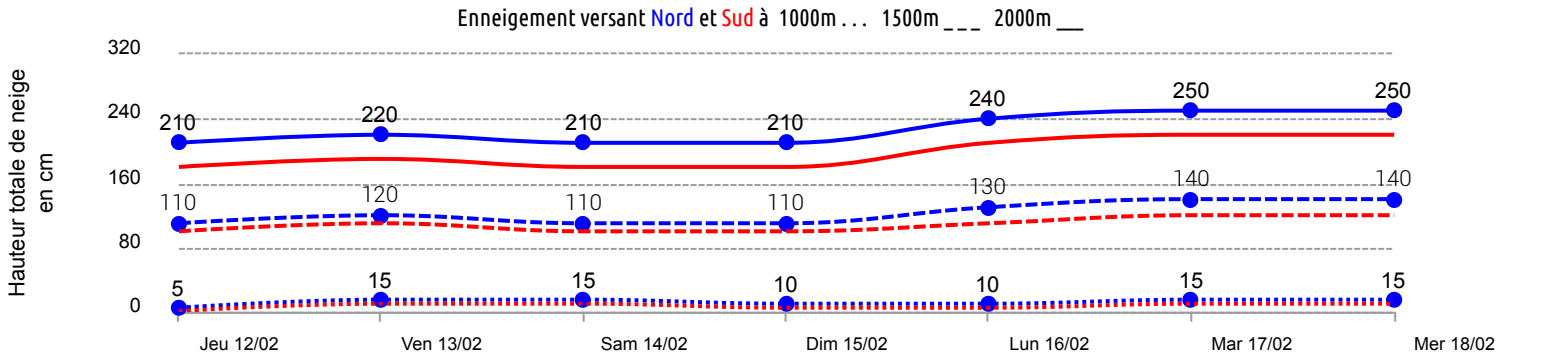

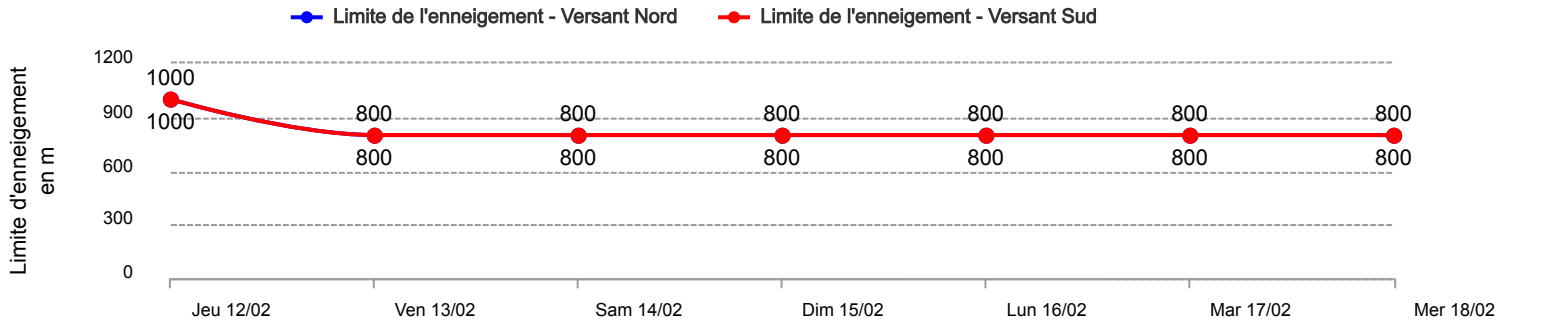

Pour consulter la vigilance en cours, veuillez vous rendre sur le site https://vigilance.meteofrance.fr/fr

Météo-France - 73 avenue de Paris, 94165 Saint-Mandé cedex - Contact : contact@meteo.fr

Rédigé par Météo-France avec la contribution des observateurs du réseau nivo-météorologiques. Partenariat : ANMSM (Maires de Stations de Montagne), DSF (Domaines Skiables de France), ADSP (Directeurs de Pistes et de la Sécurité des Stations de Sports d'Hiver) et autres acteurs de la montagne.

Bulletin neige & avalanches par téléphone au
0 892 68 10 20 Service 0,35 € / min + prix appel