Bulletin d'estimation du risque d'avalanche

(valable en dehors des pistes balisées et ouvertes)

MASSIF : Chartreuse

Rédigé le mercredi 18 février 2026 à 16h

Estimation des risques pour le : JEUDI 19 FÉVRIER

EVOLUTION DEFAVORABLE : FORTES CHUTES DE NEIGE VENTEES A PARTIR DE JEUDI APRES-MIDI/SOIREE...

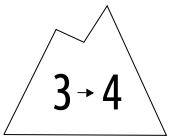

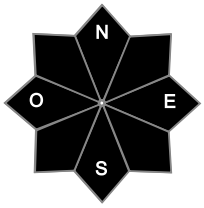

Altitude et couloirs

Indice de risque marqué évoluant en fort.

Départs spontanés : Coulées poudreuses en altitude/petites avalanches dès jeudi matin. Jeudi soir, plus nombreuses et grandes avalanches sous le vent de Nord-Ouest...

Déclenchements provoqués : Le matin risque cantonné vers les hautes crêtes (faces Nord à Est), en cours d'après-midi /soirée risque accidentel devenant marqué puis fort en altitude...

Indices de risque : 5 très fort - 4 fort - 3 marqué - 2 limité - 1 faible -- En noir : les pentes les plus dangereuses

Stabilité du manteau neigeux

Situation avalancheuse typique : neige fraîche neige ventée

Vers d'importantes quantités de neige fraîche, de plus en plus ventées : Risque d'avalanche évoluant défavorablement en fin d'après-midi et surtout nuit de jeudi à vendredi.

Départs spontanés :

Jeudi matin avec jusque 20 cm de fraîche tombés en peu de temps, on peut s'attendre à des coulées ponctuelles voire de petites avalanches poudreuses en altitude.

Jeudi au fil de l'après-midi et surtout le soir il va davantage neiger avec un vent de plus en plus soutenu, tournant au Nord-Ouest. Cumul de fraîche jusque 40 cm jeudi soir (puis 60/70 cm vendredi matin, voire 80 cm vers la Dent de Crolles).

Possibles cassures spontanées de plaques (voire ruptures de corniches), dégénérant en grande avalanches. Localement des couloirs d'avalanches seraient impactées jusqu'en forêts, à assez basse altitude ?

Déclenchements provoqués :

Le jeudi matin, risque localisé de plaques, vers les hautes crêtes, sous le vent de Sud puis Ouest (plaques peu volumineuses en général, mais une cassure plus épaisse non exclue en contrebas)

Au fil de l'après-midi, davantage de plaques en formations sous le vent turbulent et forcissant de Nord-Ouest, : Risque accidentel devenant fort le soir, dès modeste altitude...

Qualité de la neige

Qualification de l'enneigement : L'enneigement devient bon pour la saison dès 1200m, puis abondant au dessus de 1500m environ, notamment dans les combes d'altitude... Crêtes parfois dégarnies/ grosses congères et corniches sommitales...

Limites skiables : vers 1100/1300 m... sur les pistes forestières/clairières...

Qualité de la neige jeudi : Dès le matin neige fraîche (15/20 cm) plus poudreuse au dessus de 1500m environ, assez peu ventée vers les crêtes. D'anciennes grosses congères/corniches sont visibles. D'ci jeudi soir 30/40 cm de neige fraîche attendue, davantage soufflés par vents d'Ouest puis Nord-Ouest (quantités plus conséquentes vendredi matin)...

Aperçu météo pour le jeudi 19 février

	nuit	matin	après-midi	soir

Bref front neigeux actif avant jeudi matin. Jeudi neige intermittente, devenant plus soutenue/ventée en fin d'après-midi et jusque vendredi matin !

Pluie-Neige	1 200 m	1 200 m	1 100 m	1 000 m
Iso 0 °C	1 600 m	1 400 m	1 400 m	1 300 m
Vent 1500 m	↑ 45 km/h	↗ 25 km/h	→ 25 km/h	↘ 25 km/h
Vent 2000 m	↑ 75 km/h	→ 50 km/h	↘ 50 km/h	↘ 65 km/h

Épaisseur de neige hors-piste

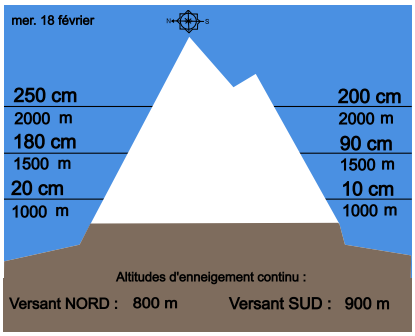

Précipitations à 1800 m

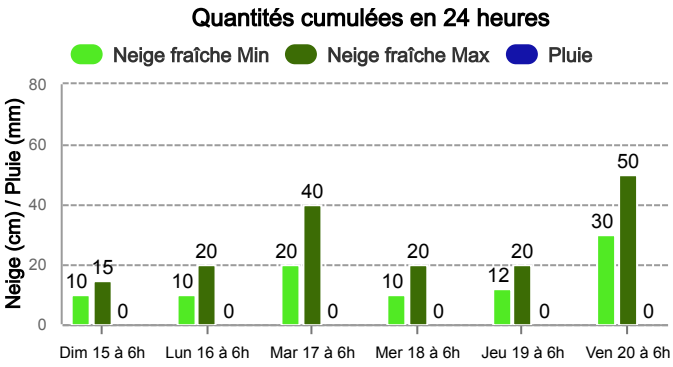

Tendance du vendredi 20 février

Indice de risque fort

Surtout vendredi matin, risque d'avalanche encore temporairement fort en haut du Massif.

Neige résiduelle et vent de Nord chassant la neige poudreuse...

L'après-midi encore un risque de rupture accidentelle important...

Pour consulter la vigilance en cours, veuillez vous rendre sur le site https://vigilance.meteofrance.fr/fr

Météo-France - 73 avenue de Paris, 94165 Saint-Mandé cedex - Contact : contact@meteo.fr

Rédigé par Météo-France avec la contribution des observateurs du réseau nivo-météorologiques. Partenariat : ANMSM (Maires de Stations de Montagne), DSF (Domaines Skiables de France), ADSP (Directeurs de Pistes et de la Sécurité des Stations de Sports d'Hiver) et autres acteurs de la montagne.

Bulletin neige & avalanches par téléphone au

0 892 68 10 20 Service 0,35 € / min + prix appel

RÉPUBLIQUE FRANÇAISE
Liberté Égalité Fraternité

METEO FRANCE
À VOS CÔTÉS, DANS UN CLIMAT QUI CHANGE

Bulletin d'estimation du risque d'avalanche

(valable en dehors des pistes balisées et ouvertes)

MASSIF : Chartreuse

Rédigé le mercredi 18 février 2026 à 16h

Conditions nivo-météo des 7 derniers jours

	jeu. 12/02				ven. 13/02				sam. 14/02				dim. 15/02				lun. 16/02				mar. 17/02				mer. 18/02			
	03h	09h	15h	21h	03h	09h	15h	21h	03h	09h	15h	21h	03h	09h	15h	21h	03h	09h	15h	21h	03h	09h	15h	21h	03h	09h	15h	21h
Météo																												
Vent (km/h)	85	70	70	35	35	20	15	15	15	25	40	35	45	25	30	55	65	75	80	80	75	60	45	30	30	20	45	90
à 2000m																												
Vent (km/h)	70	50	45	15	15	20	25	10	10	20	30	35	35	10	10	25	35	45	60	60	50	40	30	20	15	15	25	75
à 1500m																												

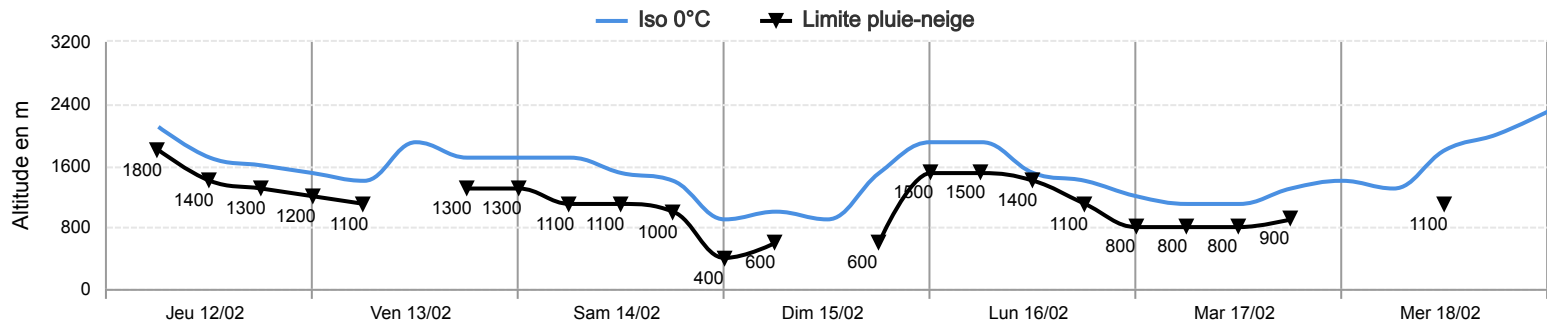

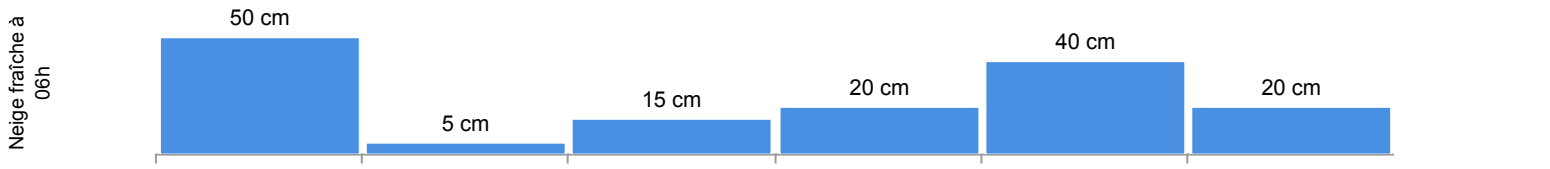

Risque d'avalanche	jeu. 12/02	ven. 13/02	sam. 14/02	dim. 15/02	lun. 16/02	mar. 17/02	mer. 18/02
	3	3	3	3	3	3	3

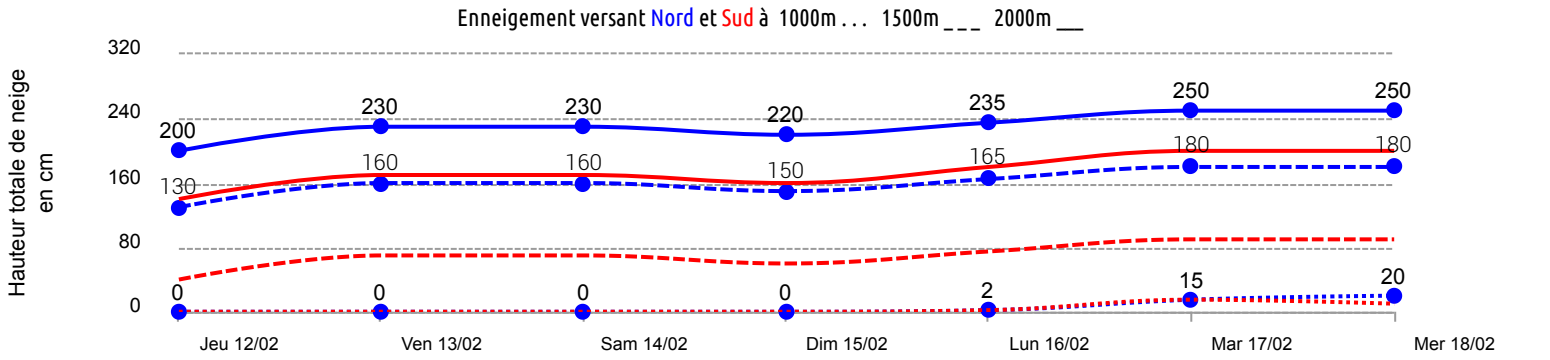

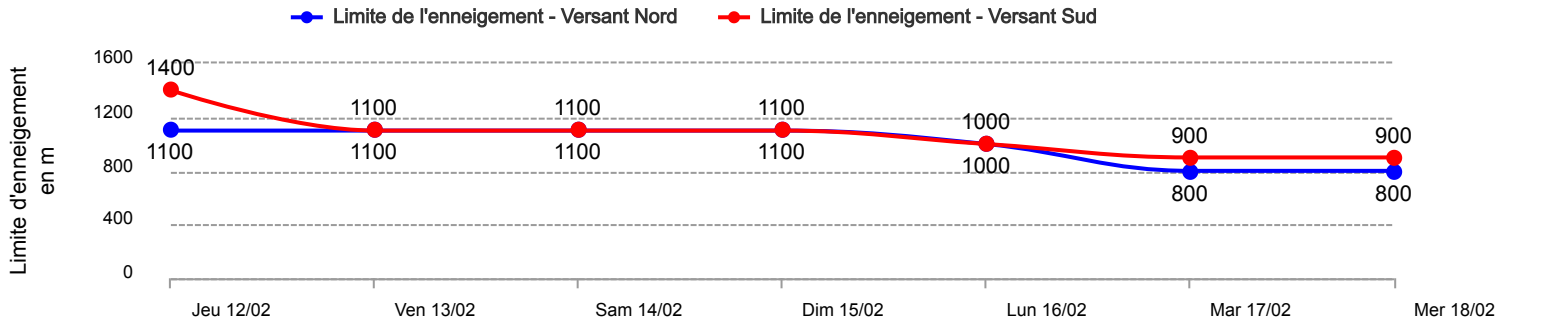

Pour consulter la vigilance en cours, veuillez vous rendre sur le site https://vigilance.meteofrance.fr/fr

Météo-France - 73 avenue de Paris, 94165 Saint-Mandé cedex - Contact : contact@meteo.fr

Bulletin neige & avalanches par téléphone au

0 892 68 10 20 Service 0,35 € / min + prix appel

Rédigé par Météo-France avec la contribution des observateurs du réseau nivo-météorologiques. Partenariat : ANMSM (Maires de Stations de Montagne), DSF (Domaines Skiables de France), ADSP (Directeurs de Pistes et de la Sécurité des Stations de Sports d'Hiver) et autres acteurs de la montagne.