Bulletin d'estimation du risque d'avalanche

(valable en dehors des pistes balisées et ouvertes)

MASSIF : Cinto Rotondo

Rédigé le mercredi 18 février 2026 à 16h

Estimation des risques pour le : JEUDI 19 FÉVRIER

NOMBREUSES INSTABILITÉS DANS LA NEIGE FRAICHE FORTEMENT VENTÉE

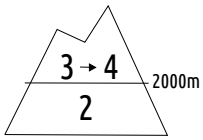

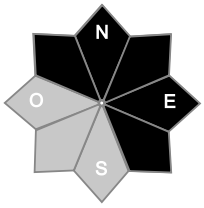

Au-dessus de 2000m indice de risque marqué évoluant en fort, plus bas indice limité.

Départs spontanés : Avalanches de neige fraîche de taille moyenne à grande au-dessus de 2000m

Déclenchements provoqués : Nombreuses plaques à vent réactives dans la neige récente.

Indices de risque : 5 très fort - 4 fort - 3 marqué - 2 limité - 1 faible -- En noir : les pentes les plus dangereuses

Stabilité du manteau neigeux

Situation avalancheuse typique : neige ventée neige fraîche

Déclenchements provoqués : Nombreuses plaques en formation, ou déjà formées, sous l'action du vent de Sud-Ouest qui souffle encore ce jeudi, loin des crêtes, plus fréquentes au-dessus de 2000 m. Certaines de ces plaques présentent un aspect poudreux très piégeux et sont facilement déclenchables au passage d'un skieur ou randonneur y compris à distance. Elles sont plus épaisses et plus dures en montant en altitude, même sous le vent, et sont réparties de façon plus hétérogène, avec des accumulations localement épaisses qui côtoient des secteurs décapés par le vent tempétueux. Toutes ces plaques reposent sur des couches fragiles temporaires (neige récente moins dense) ou de la neige roulée. Avalanches généralement de taille moyenne à grande (taille 2 à 3). En versants ombragés, une couche fragile persistante davantage enfouie peut être sollicitée après cassure d'une plaque décrite au dessus et donner une avalanche de plus grande ampleur (taille 4) qui peut présenter des cassures importantes.
En dessous de 2000 mètres, voire plus haut en versants ensoleillés, on pourra trouver des quantités variables de neige fraîche en surface, reposant sur un manteau neigeux plus ou moins humidifié, ce qui limitera l'ampleur d'un éventuel déclenchement mais parfois déclenchable par un seul skieur. Les versants Nord et Est sont les plus chargées avec des plaques parfois épaisses.

Départs spontanés : Les chutes à venir d'ici jeudi soir, avec un cumul attendu de 30 à 40 cm, vont au fil des heures, faire augmenter le risque de départs naturels d'avalanches de poudre. Les départs ne vont d'abord concerner que les pentes les plus raides en matinée avant de s'étendre à des pentes moins raides en cours de journée et surtout soirée. Des décrochements de plaques peuvent se également seproduire à cause de la neige transportée par le vent, venant surcharger et déclencher une de ces plaque. De très grandes avalanches sont possibles dans les pentes les plus chargées.

Autres : Risque de glissade en neige dure ou glacée aux abords des crêtes et sommets balayés par les vents.

Qualité de la neige

Qualification de l'enneigement : L'enneigement est excellent pour la saison à toutes altitudes. On relève plus de 2 mètres dans les combes abritées.
Limite d'enneigement skiable : 1300 à 1500 m selon le versant.
État de la neige : On trouve en surface une couche de neige fraîche de plus en plus significative en montant mais le vent d'Ouest à Nord-ouest soutenu rend l'enneigement très hétérogène : les orientations Nord et Est sont souvent plus garnies que les pentes Ouest rapidement pelées ou verglacées dès que l'on se rapproche des crêtes et sommets. La neige est froide et poudreuse à l'abri du vent dès 1800 à 2000 m d'altitude, elle devient plus compacte, voire cartonnée dans les secteurs ventés. On trouve localement des accumulations de neige roulée. Corniches et accumulations parfois volumineuses sont en place.

Aperçu météo pour le jeudi 19 février

	nuit	matin	après-midi	soir
Pluie-Neige	1 600 m	1 100 m	900 m	1 200 m
Iso 0 °C	1 900 m	1 400 m	1 400 m	1 600 m
Vent 1500 m	↗ 40 km/h	↗ 50 km/h	→ 70 km/h	→ 40 km/h
Vent 3000 m	↗ 80 km/h	→ 90 km/h	→ 120 km/h	↘ 80 km/h

Épaisseur de neige hors-piste

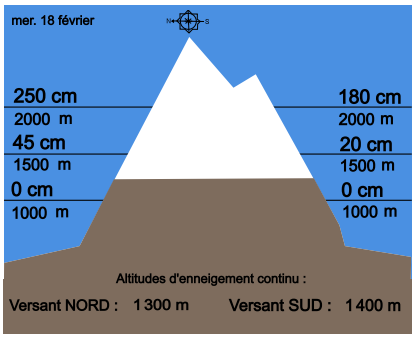

Précipitations à 1800 m

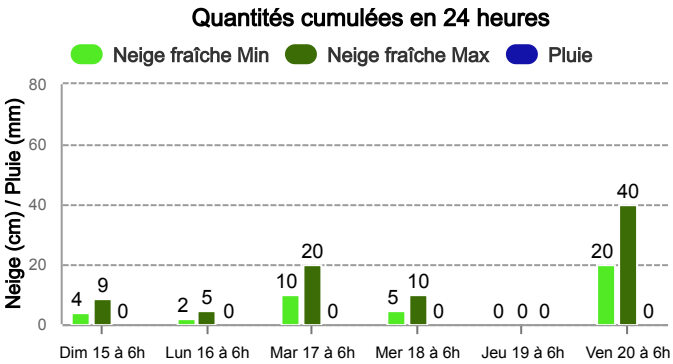

Tendance du vendredi 20 février

Indice de risque marqué

En baisse avec le retour du soleil.

Pour consulter la vigilance en cours, veuillez vous rendre sur le site https://vigilance.meteofrance.fr/fr

Météo-France - 73 avenue de Paris, 94165 Saint-Mandé cedex - Contact : contact@meteo.fr

Rédigé par Météo-France avec la contribution des observateurs du réseau nivo-météorologiques. Partenariat : ANMSM (Maires de Stations de Montagne), DSF (Domaines Skiables de France), ADSP (Directeurs de Pistes et de la Sécurité des Stations de Sports d'Hiver) et autres acteurs de la montagne.

Bulletin neige & avalanches par téléphone au **0 892 68 10 20** Service 0,35 € / min + prix appel

Bulletin d'estimation du risque d'avalanche

(valable en dehors des pistes balisées et ouvertes)

MASSIF : Cinto Rotondo

Rédigé le mercredi 18 février 2026 à 16h

Conditions nivo-météo des 7 derniers jours

	jeu. 12/02				ven. 13/02				sam. 14/02				dim. 15/02				lun. 16/02				mar. 17/02				mer. 18/02			
	03h	09h	15h	21h	03h	09h	15h	21h	03h	09h	15h	21h	03h	09h	15h	21h	03h	09h	15h	21h	03h	09h	15h	21h	03h	09h	15h	21h
Météo																												
Vent (km/h)	80	120	100	100	60	55	35	70	50	20	50	50	40	70	50	50	80	90	120	130	100	80	70	60	60	65	60	60
à 3000m																												
Vent (km/h)	70	80	80	70	50	40	20	40	30	15	30	30	20	30	30	40	70	70	90	90	80	50	50	40	45	30	30	30
à 1500m																												

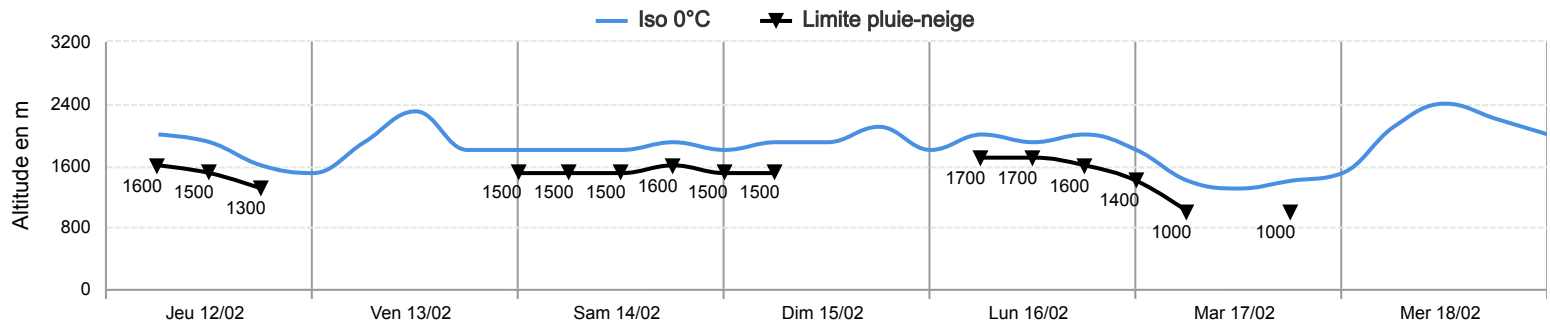

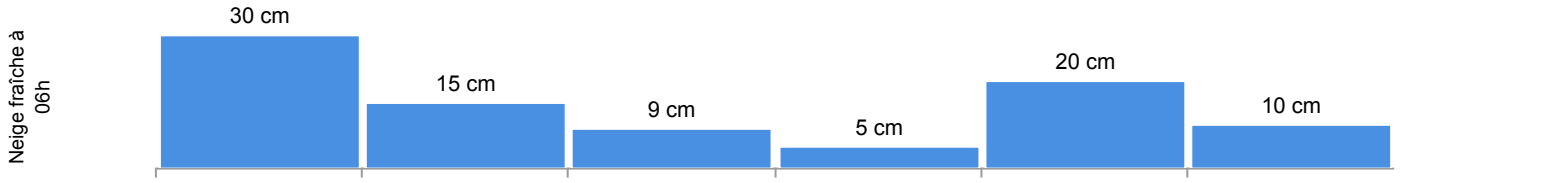

Risque d'avalanche	jeu. 12/02	ven. 13/02	sam. 14/02	dim. 15/02	lun. 16/02	mar. 17/02	mer. 18/02
	4	3	3	2	3	3	3

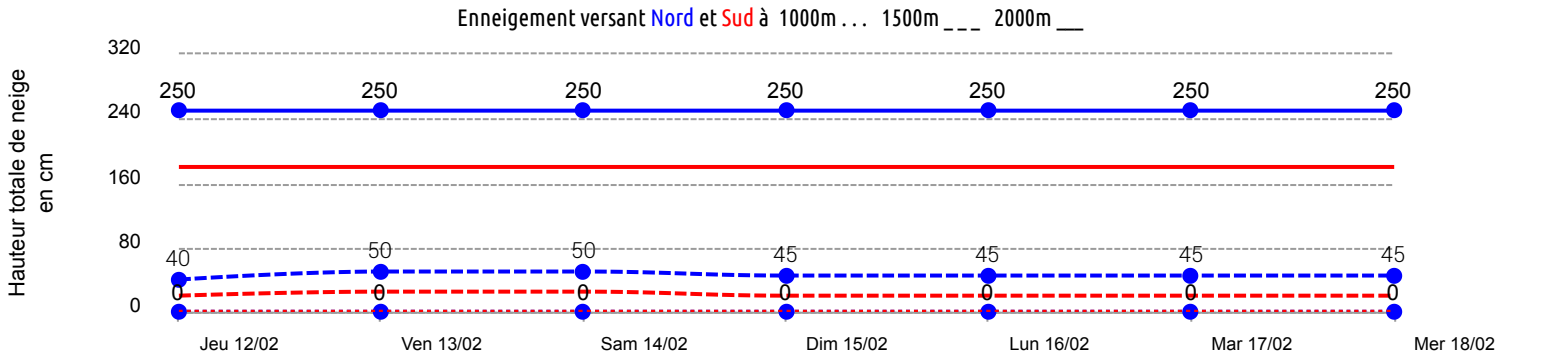

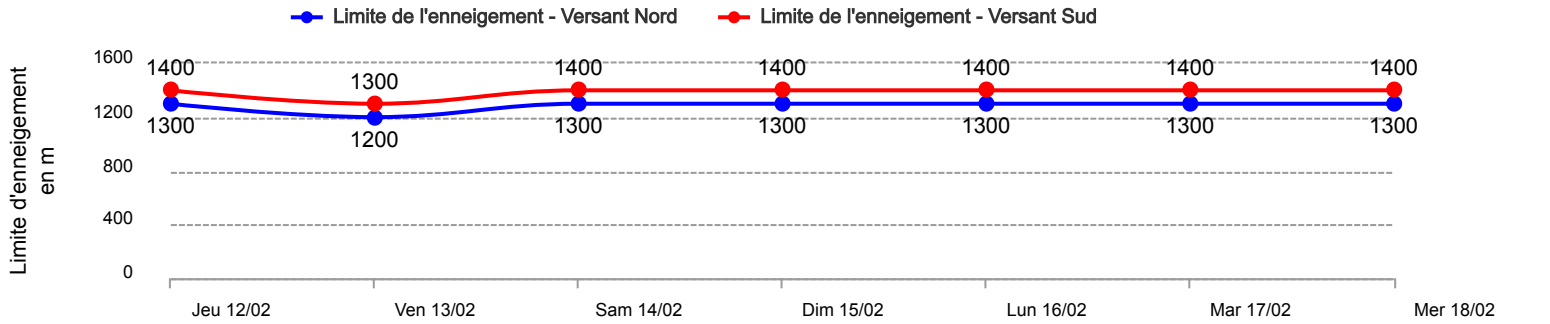

Pour consulter la vigilance en cours, veuillez vous rendre sur le site https://vigilance.meteofrance.fr/fr

Météo-France - 73 avenue de Paris, 94165 Saint-Mandé cedex - Contact : contact@meteo.fr

Rédigé par Météo-France avec la contribution des observateurs du réseau nivo-météorologiques. Partenariat : ANMSM (Maires de Stations de Montagne), DSF (Domaines Skiables de France), ADSP (Directeurs de Pistes et de la Sécurité des Stations de Sports d'Hiver) et autres acteurs de la montagne.

Bulletin neige & avalanches par téléphone au

0 892 68 10 20 Service 0,35 € / min + prix appel