# Bulletin d'estimation du risque d'avalanche
(valable en dehors des pistes balisées et ouvertes)

# MASSIF : Haut-Var Haut-Verdon

Rédigé le mercredi 18 février 2026 à 16h

## Estimation des risques pour le : JEUDI 19 FÉVRIER

**NOMBREUSES NOUVELLES INSTABILITÉS DANS LA NEIGE FRAÎCHE VENTÉE, PARFOIS VOLUMINEUSES DANS LE HAUT-VERDON**

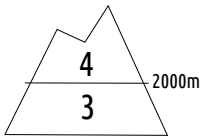


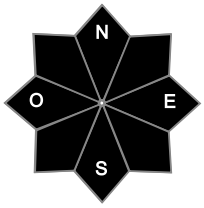


Au-dessus de 2000m indice de risque fort, plus bas indice marqué.

**Départs spontanés :** nombreux départs pendant les chutes de neige, ou par transport par le vent.

**Déclenchements provoqués :** nombreuses instabilités dans la neige fraîche ventée, parfois volumineuses dans le Haut-Verdon

Indices de risque : 5 très fort - 4 fort - 3 marqué - 2 limité - 1 faible -- En noir : les pentes les plus dangereuses

## Stabilité du manteau neigeux

**Situation avalancheuse typique :** neige fraîche couche fragile persistante

**Déclenchements provoqués** :
nombreuses instabilités dans la neige fraîche et récente ventée, possibles en toutes orientations au dessus de 1800/2000 m, même loin des crêtes. Les plaques formées en surface du manteau neigeux sont souvent d'aspect poudreux, ou parfois durci par le vent à l'approche des crêtes où elles sont réparties de manière plus hétérogène. Elles peuvent être faciles à déclencher au passage d'un seul skieur, et peuvent localement mobiliser d'importantes quantités de neige tombée récemment et encore peu stabilisée, engendrant des avalanches de taille moyenne (taille 2), voire grande (taille 3) dans les zones de forte accumulation en Haut-Verdon.

Dans le Haut-Verdon, en orientations ouest, nord et est d'altitude supérieure à 2000/2200 m environ, le risque de déclencher une grande avalanche est plus élevé, et une très grande (taille 4) n'est pas exclue, sous forme de départ linéaire de grande ampleur. On trouve en effet une couche fragile persistante enfouie à la base du manteau neigeux, pouvant encore être sollicitée, en particulier après un premier départ en surface dans la neige fraîche.

En dessous de 1800/2000 m, le risque reste marqué : les plaques sont moins épaisses, avec des tailles d'avalanches généralement moyenne.

**Départs spontanés** : nombreux départs possibles en pentes raides, en toutes orientations. Départs ponctuels en neige fraîche pendant les chutes, et également linaires en neige ventée sous l'effet du transport de neige par le vent de sud-ouest puis nord-ouest. Avalanches petites à moyennes en général. Dans le Haut-Verdon, une grande taille est localement possible dans les zones de forte accumulation, voire une très grande en cas de sur-avalanche par rupture de la couche fragile persistante enfouie décrite précédemment.

## Qualité de la neige

**Enneigement** très excédentaire pour un mois de février. Il faut remonter à 2014 pour trouver un enneigement encore plus abondant à cette période de l'année.
Données observées : en ubacs, 1 m dès 1600/1700 m, 1,5 m à 2 m vers 2000 m, 2 m à 2,5 m vers 2400 m.

**Enneigement skiable** dès 1200 m en terrains favorables, 1500 m en adrets.

**État de la neige en surface** : jeudi matin, 15/20 cm de neige fraîche modérément ventée en Haut-Verdon, plutôt 7/10 cm en Haut-Var. Elle repose sur une couche parfois épaisse de neige récente souvent fortement travaillée par le vent en altitude, restée légère et poudreuse en ubacs abrités du vent, notamment en forêts au-dessus de 1800 m ; elle est plus tassée voire finement croûtée sous 1800 m. En journée, transport et densification de la neige fraîche par le vent de nord-ouest.

## Aperçu météo pour le jeudi 19 février

| | nuit | matin | après-midi | soir |
|---|---|---|---|---|
| | | | | |

Neige généralisée la nuit, puis fréquentes averses en journée sur le Haut-Verdon uniquement. Vent de nord-ouest se renforçant en altitude en journée.

| | | | | |
|---|---|---|---|---|
| **Pluie-Neige** | 1 000 m | 1 000 m | 1 200 m | 1 100 m |
| **Iso 0 °C** | 1 900 m | 1 700 m | 1 800 m | 1 800 m |
| **Vent 2000 m** | ↑ 30 km/h | ↘ 45 km/h | ↘ 55 km/h | ↘ 60 km/h |
| **Vent 3000 m** | ↗ 50 km/h | ↘ 55 km/h | ↘ 85 km/h | ↓ 65 km/h |

## Épaisseur de neige hors-piste

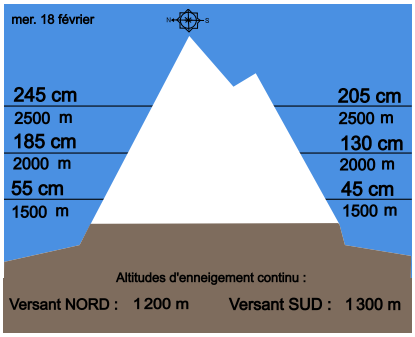


## Précipitations à 1800 m

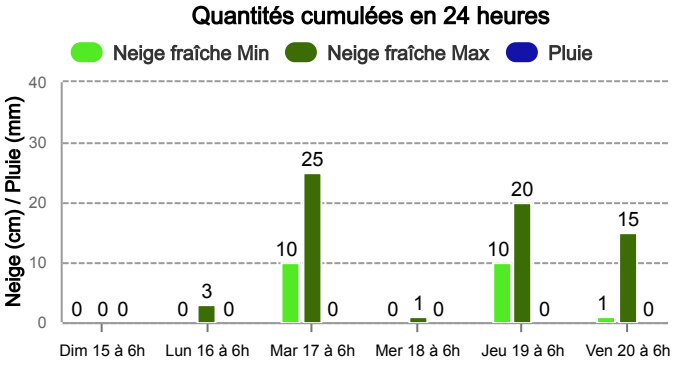


## Tendance du vendredi 20 février

**Indice de risque fort**

risque encore fort en Haut-Verdon avec de nombreuses instabilités en place dans la neige récente, et de nouvelles se formant avec un vent de nord encore sensible le matin.

Pour consulter la vigilance en cours, veuillez vous rendre sur le site https://vigilance.meteofrance.fr/fr

Météo-France - 73 avenue de Paris, 94165 Saint-Mandé cedex - Contact : contact@meteo.fr

Rédigé par Météo-France avec la contribution des observateurs du réseau nivo-météorologiques. Partenariat : ANMSM (Maires de Stations de Montagne), DSF (Domaines Skiables de France), ADSP (Directeurs de Pistes et de la Sécurité des Stations de Sports d'Hiver) et autres acteurs de la montagne.

Bulletin neige & avalanches par téléphone au **0 892 68 10 20** Service 0,35 € / min + prix appel

RÉPUBLIQUE FRANÇAISE
*Liberté Égalité Fraternité*

METEO FRANCE
À VOS CÔTÉS, DANS UN CLIMAT QUI CHANGE

# Bulletin d'estimation du risque d'avalanche

## (valable en dehors des pistes balisées et ouvertes)

# MASSIF : Haut-Var Haut-Verdon

Rédigé le mercredi 18 février 2026 à 16h

## Conditions nivo-météo des 7 derniers jours

| | jeu. 12/02 | | | | ven. 13/02 | | | | sam. 14/02 | | | | dim. 15/02 | | | | lun. 16/02 | | | | mar. 17/02 | | | | mer. 18/02 | | | |
|---|---|---|---|---|---|---|---|---|---|---|---|---|---|---|---|---|---|---|---|---|---|---|---|---|---|---|---|---|
| | 03h | 09h | 15h | 21h | 03h | 09h | 15h | 21h | 03h | 09h | 15h | 21h | 03h | 09h | 15h | 21h | 03h | 09h | 15h | 21h | 03h | 09h | 15h | 21h | 03h | 09h | 15h | 21h |
| Météo | | | | | | | | | | | | | | | | | | | | | | | | | | | | |
| Vent (km/h) | 80 | 100 | 140 | 130 | 90 | 30 | 40 | 55 | 70 | 70 | 60 | 40 | 35 | 45 | 45 | 55 | 65 | 85 | 110 | 100 | 90 | 75 | 70 | 60 | 45 | 40 | 35 | 65 |
| à 3000m | | | | | | | | | | | | | | | | | | | | | | | | | | | | |
| Vent (km/h) | 80 | 90 | 120 | 115 | 60 | 15 | 20 | 25 | 35 | 45 | 40 | 35 | 5 | 5 | 15 | 35 | 50 | 50 | 80 | 70 | 65 | 50 | 50 | 40 | 30 | 30 | 15 | 40 |
| à 2000m | | | | | | | | | | | | | | | | | | | | | | | | | | | | |

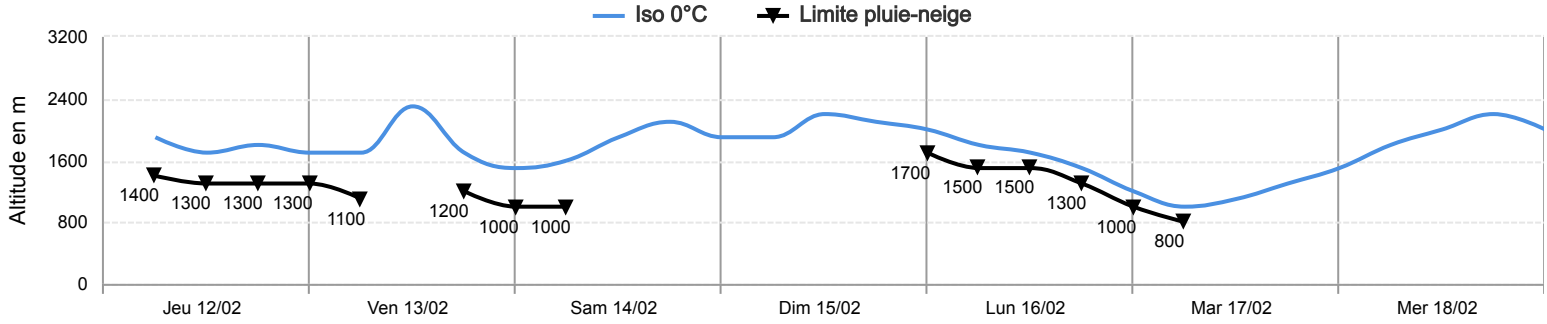


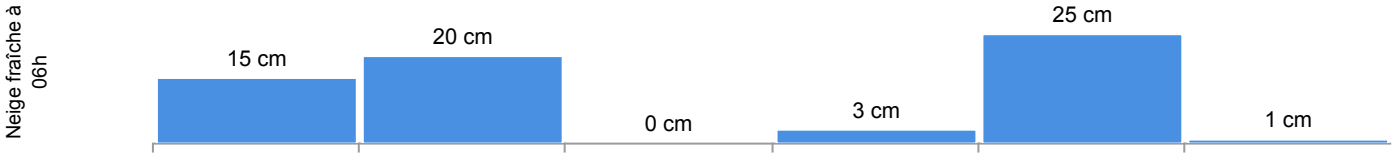


| Risque d'avalanche | jeu. 12/02 | ven. 13/02 | sam. 14/02 | dim. 15/02 | lun. 16/02 | mar. 17/02 | mer. 18/02 |
|---|---|---|---|---|---|---|---|
| | 4 | 4 | 3 | 3 | 3 | 3 | 3 |

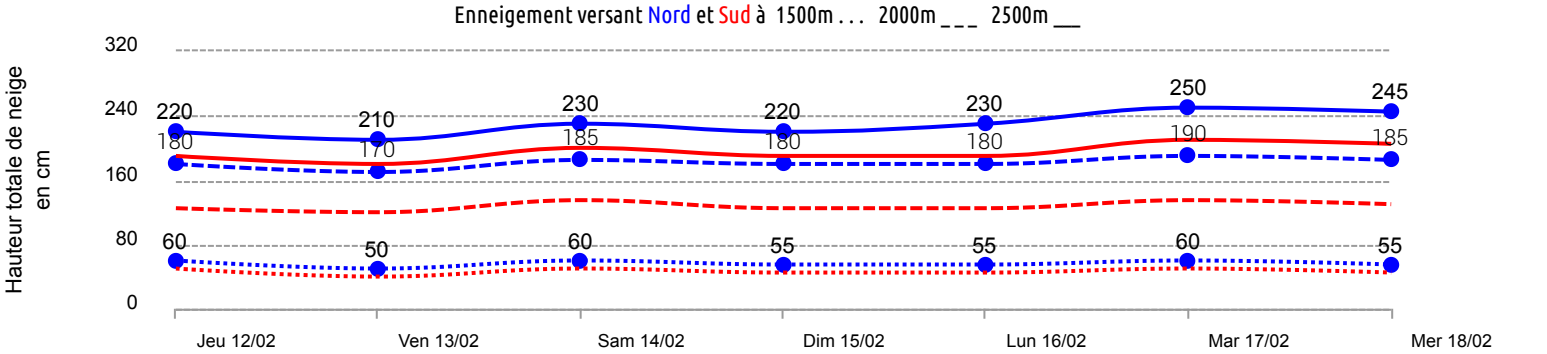


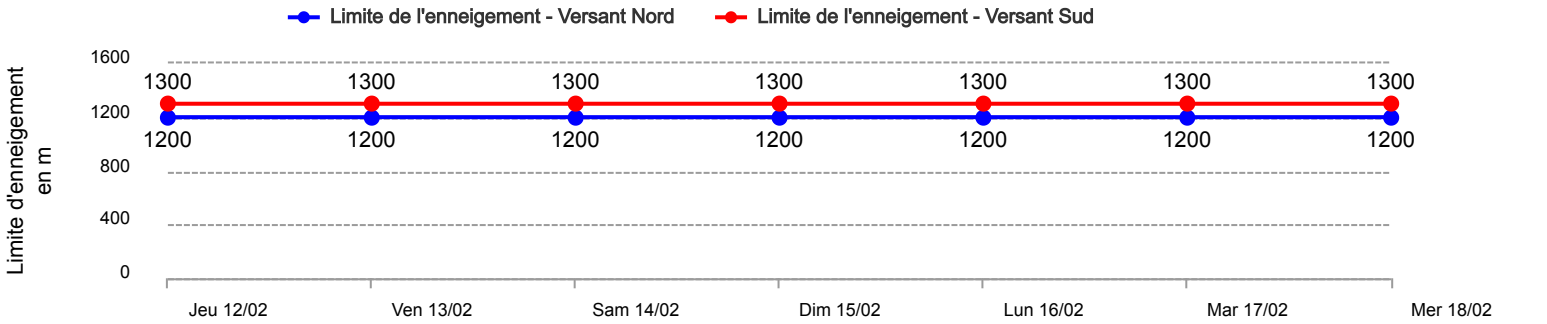


Pour consulter la vigilance en cours, veuillez vous rendre sur le site https://vigilance.meteofrance.fr/fr


Météo-France - 73 avenue de Paris, 94165 Saint-Mandé cedex - Contact : contact@meteo.fr


Rédigé par Météo-France avec la contribution des observateurs du réseau nivo-météorologiques. Partenariat : ANMSM (Maires de Stations de Montagne), DSF (Domaines Skiables de France), ADSP (Directeurs de Pistes et de la Sécurité des Stations de Sports d'Hiver) et autres acteurs de la montagne.

Bulletin neige & avalanches par téléphone au

**0 892 68 10 20** Service 0,35 € / min + prix appel