RÉPUBLIQUE FRANÇAISE
Liberté Égalité Fraternité

METEO FRANCE
À VOS CÔTÉS, DANS UN CLIMAT QUI CHANGE

Bulletin d'estimation du risque d'avalanche
(valable en dehors des pistes balisées et ouvertes)
MASSIF : Haute-Maurienne

Rédigé le mercredi 18 février 2026 à 16h

Estimation des risques pour le : JEUDI 19 FÉVRIER

NOMBREUSES AVALANCHES, PARFOIS DE GRANDE AMPLEUR, POUVANT METTRE EN PÉRIL LES INFRASTRUCTURES EXPOSÉES.

5

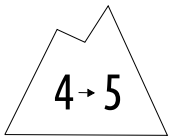

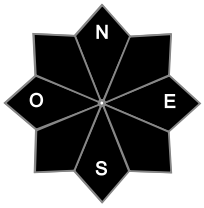

Indice de risque fort évoluant en très fort.

Départs spontanés : POSSIBLES TRES GRANDES AVALANCHES.

Déclenchements provoqués : INSTABILITÉS FORTES ET GÉNÉRALISÉES.

Indices de risque : 5 très fort - 4 fort - 3 marqué - 2 limité - 1 faible -- En noir : les pentes les plus dangereuses

Vigilance orange avalanches en cours ou prévue sur le massif

Stabilité du manteau neigeux

Situation avalancheuse typique : couche fragile persistante neige fraîche

Départs spontanés : activité avalancheuse potentiellement remarquable en fin nuit de mercredi à jeudi, et surtout **jeudi en fin de journée/soirée** avec les cumuls de neige fraîche qui augmentent au fil des heures et le fort vent de Nord Ouest qui forcit. D'ici jeudi soir, l'établissement du vent conjugué aux 15 cm de neige surchargent un manteau déjà proche de la rupture. **De grandes (taille 3) à très grandes (taille 4) avalanches sont possibles**. **Elles peuvent aller loin avec un fort potentiel destructeur** en mettant en péril les infrastructures de montagne. Atteignant leur **emprise maximale connue**, évoluer en fond de vallon/vallée n'est pas gage de sécurité.

Déclenchements provoqués :
RISQUE ACCIDENTEL MAXIMAL, nombreuses plaques épaisses et très réactives avec forte propagation. Plaques présentes aussi près de crêtes qu'en bas de pente. Risque généralisé dans tous les versants.

Qualité de la neige

Enneigement : Les chutes de neige récentes ont permis de repasser dans un enneigement excédentaire dès 1200m en Nord et 1400m en sud.

Limite skiable : Skiable dès 1000m en Nord, plutôt 1200m en Sud pas trop raide.

Qualité de la neige : très gros cumuls de neige ventée et cartonnée dès la moyenne montagne, avec plus d'1m50 dans les zones d'accumulations tandis que les croupes et crêtes exposées sont bien moins chargées voir glacées. Plus bas et à l'abri du vent , la couche de poudreuse est moins ventée/cartonnée avec une neige profonde dès 1200/1300m. Le vent en seconde partie de journée va largement transporter la neige de surface.

Aperçu météo pour le jeudi 19 février

	nuit	matin	après-midi	soir

Averses de neige en journée. Vent de Nord Ouest se renforçant dans l'après-midi.

Pluie-Neige	1 300 m	1 100 m	1 200 m	1 200 m
Iso 0 °C	1 800 m	1 500 m	1 500 m	1 500 m
Vent 2500 m	↖ 40 km/h	↘ 40 km/h	→ 60 km/h	↘ 70 km/h
Vent 3500 m	↖ 40 km/h	↘ 50 km/h	↘ 90 km/h	↘ 100 km/h

Épaisseur de neige hors-piste

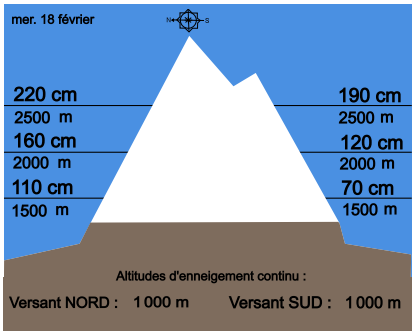

Précipitations à 1800 m

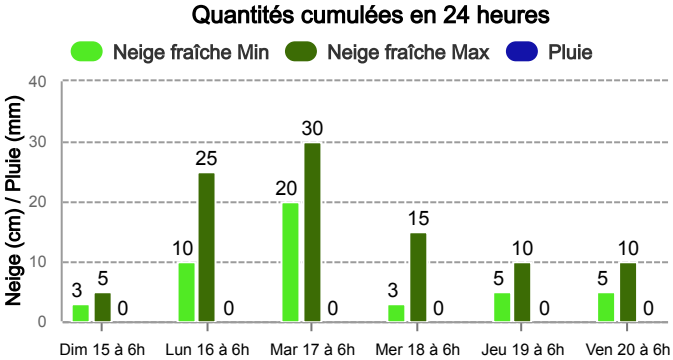

Tendance du vendredi 20 février

5

Indice de risque très fort

Le vent de NO soutenu dans la nuit de jeudi à vendredi entretient un risque de déclenchement de grandes avalanches. Le risque 5 reste envisagé sur ce créneau. Puis, le risque naturel baissera.

Pour consulter la vigilance en cours, veuillez vous rendre sur le site https://vigilance.meteofrance.fr/fr

Météo-France - 73 avenue de Paris, 94165 Saint-Mandé cedex - Contact : contact@meteo.fr

Rédigé par Météo-France avec la contribution des observateurs du réseau nivo-météorologiques. Partenariat : ANMSM (Maires de Stations de Montagne), DSF (Domaines Skiables de France), ADSP (Directeurs de Pistes et de la Sécurité des Stations de Sports d'Hiver) et autres acteurs de la montagne.

Bulletin neige & avalanches par téléphone au
0 892 68 10 20 Service 0,35 € / min + prix appel

RÉPUBLIQUE FRANÇAISE
Liberté Égalité Fraternité

METEO FRANCE
À VOS CÔTÉS, DANS UN CLIMAT QUI CHANGE

Bulletin d'estimation du risque d'avalanche
(valable en dehors des pistes balisées et ouvertes)
MASSIF : Haute-Maurienne

Rédigé le mercredi 18 février 2026 à 16h

Conditions nivo-météo des 7 derniers jours

	jeu. 12/02				ven. 13/02				sam. 14/02				dim. 15/02				lun. 16/02				mar. 17/02				mer. 18/02			
	03h	09h	15h	21h	03h	09h	15h	21h	03h	09h	15h	21h	03h	09h	15h	21h	03h	09h	15h	21h	03h	09h	15h	21h	03h	09h	15h	21h
Météo																												
Vent (km/h)	60	75	80	65	60	35	40	50	40	20	35	40	45	45	50	60	65	75	90	110	110	90	80	70	50	40	30	40
à 3500m																												
Vent (km/h)	50	60	65	55	45	20	30	40	30	10	25	35	40	35	40	50	55	65	80	90	90	80	70	60	45	30	20	30
à 2500m																												

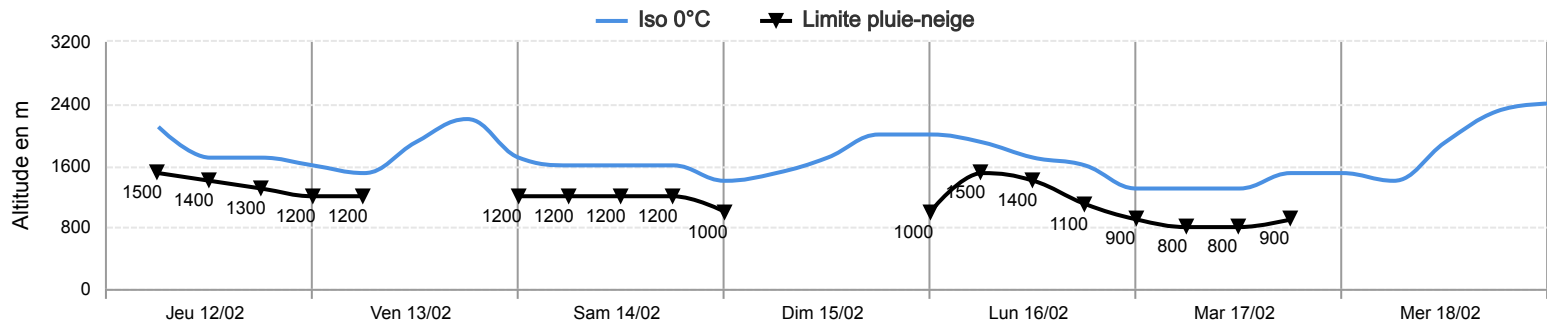

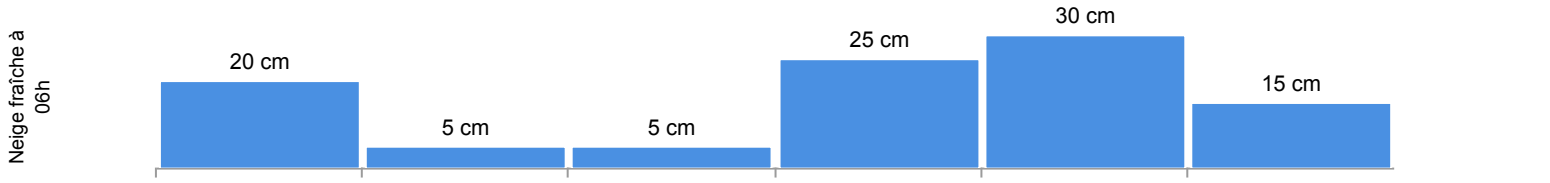

Risque d'avalanche	jeu. 12/02	ven. 13/02	sam. 14/02	dim. 15/02	lun. 16/02	mar. 17/02	mer. 18/02
	4	4	4	3	4	4	4

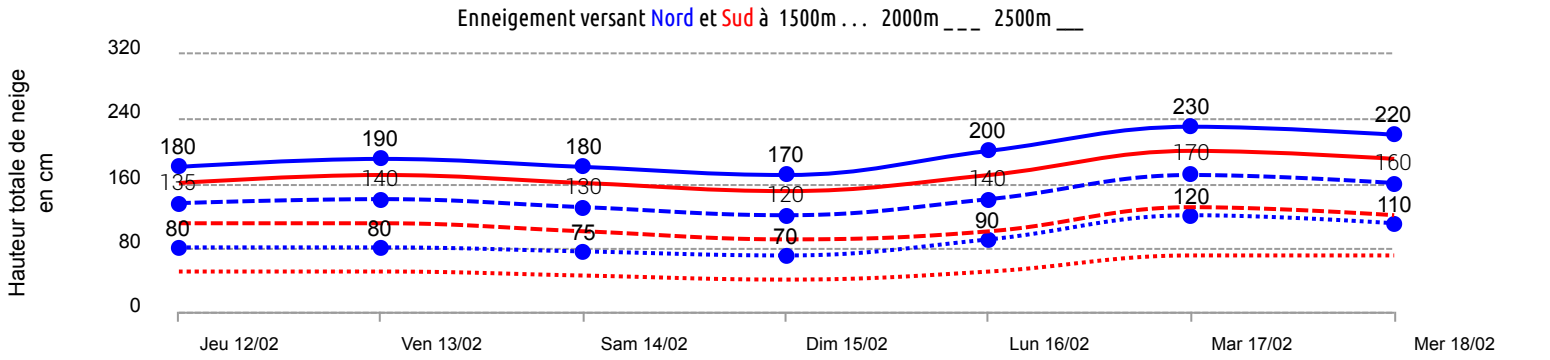

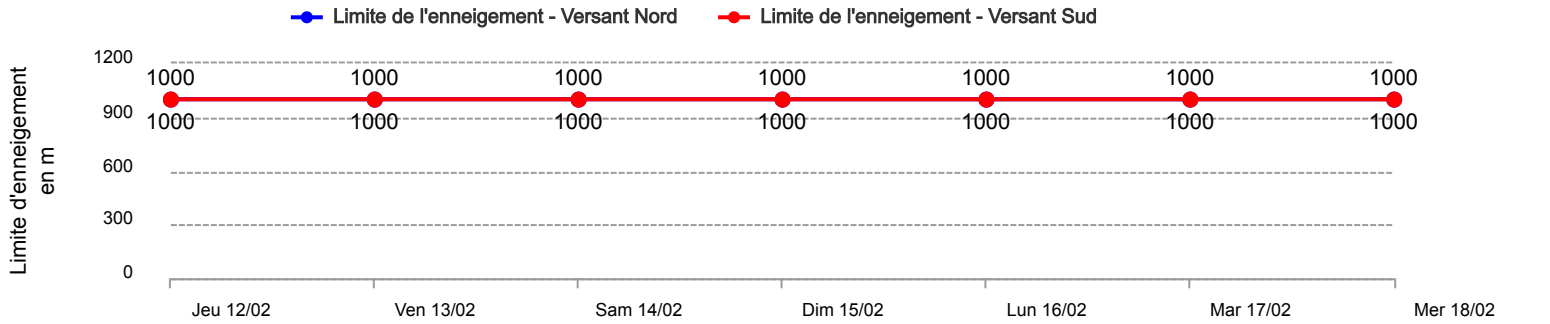

Pour consulter la vigilance en cours, veuillez vous rendre sur le site https://vigilance.meteofrance.fr/fr

Météo-France - 73 avenue de Paris, 94165 Saint-Mandé cedex - Contact : contact@meteo.fr

Rédigé par Météo-France avec la contribution des observateurs du réseau nivo-météorologiques. Partenariat : ANMSM (Maires de Stations de Montagne), DSF (Domaines Skiables de France), ADSP (Directeurs de Pistes et de la Sécurité des Stations de Sports d'Hiver) et autres acteurs de la montagne.

Bulletin neige & avalanches par téléphone au
0 892 68 10 20 Service 0,35 € / min + prix appel