Bulletin d'estimation du risque d'avalanche

(valable en dehors des pistes balisées et ouvertes)

MASSIF : Luchonnais

Rédigé le mercredi 18 février 2026 à 16h

Estimation des risques pour le : JEUDI 19 FÉVRIER

CHUTES DE NEIGE VENTEES.

3

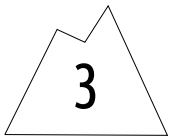

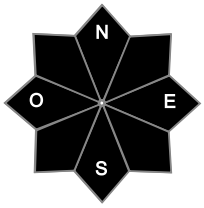

Indice de risque marqué.

Départs spontanés : en neige récente, ponctuels et linéaires.

Déclenchements provoqués : instabilités en neige récente et plaques à vent.

Indices de risque : 5 très fort - 4 fort - 3 marqué - 2 limité - 1 faible -- En noir : les pentes les plus dangereuses

Stabilité du manteau neigeux

Situation avalancheuse typique : neige fraîche neige ventée

Déclenchements provoqués : risque **marqué** de déclenchement de **plaques instables** formées dans la nuit de mercredi à jeudi, **continuant à se former et s'épaississant en tous secteurs** en journée de jeudi sous le **vent de nord-ouest très turbulent**. Une **faible sollicitation** d'un skieur ou randonneur est **suffisante pour déclencher des avalanches de plaques de taille 2 le matin à taille 3 ensuite.** Dépôts de blocs, durs en versants Ouest à Nord plus ventés, plus pulvérulents partout ailleurs.

A noter : ce **risque accidentel sera temporairement un peu plus important** entre **jeudi fin de journée et vendredi matin**, **fonction des quantités de neige** supplémentaires attendues sur cette même période, **à réévaluer lors du prochain BERA**.

Observables : travail du vent visible et **plaques facilement identifiables** en versants **Ouest à Nord**, mais **peu visibles et d'aspect poudreux dans les autres secteurs**.

Départs spontanés : en **neige récente**, en **tous secteurs raides**. Généralement **coulées ou petites avalanches en départs ponctuels en matinée. Puis nombreuses avalanches petites à moyennes en cours d'après-midi, soirée et nuit suivante en fonction de l'accroissement de la couche de neige fraîche**.
L'apport supplémentaire de **neige transportée par le vent** de nord-ouest est **à l'origine dans l'après-midi et la nuit suivante** du **déclenchement des plaques décrites ci-dessus**, avec des **cassures linéaires pouvant atteindre 30 à 50 cm dans les versants Est à Sud déventés** où se constituent les accumulations les plus importantes. **Cassures localement plus épaisses** (50 à 80 cm) et **déclenchement plus rare mais possible** d'avalanche de **taille 3 à 4** en partant d'une **accumulation encore en place au-dessus de 2300/2400m**.

Qualité de la neige

Enneigement : nouvelles chutes de neige redonnant un aspect plus hivernal au massif, saupoudrage à partir de 800/900m. Crêtes, cols et sommets pelés en expositions Ouest, en neige dure à très dure partout ailleurs.
Limites skiables : à partir de 1200 à 1300m suivant les versants, car sans sous-couche en dessous.
État de la neige : au matin, couche de neige fraîche d'une dizaine de centimètres, déposée sur manteau neigeux stabilisé sous 2000/2100m, frittée à cartonnée dans les pentes ouest à nord. Augmentation en cours de journée de la couche de neige fraîche, travaillée par le vent très turbulent et irrégulier : répartition hétérogène et frittée à cartonnée en gagnant en altitude.

Aperçu météo pour le jeudi 19 février

	nuit	matin	après-midi	soir
Neigeux et fortement venté.				
Pluie-Neige	800 m	1 000 m	1 100 m	1 000 m
Iso 0 °C	1 100 m	1 300 m	1 400 m	1 300 m
Vent 2000 m	↘ 70 km/h	↘ 70 km/h	↘ 70 km/h	↓ 60 km/h
Vent 3000 m	↘ 90 km/h	↘ 110 km/h	↘ 95 km/h	↘ 80 km/h

Épaisseur de neige hors-piste

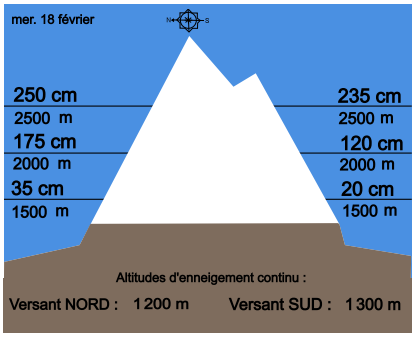

Précipitations à 1800 m

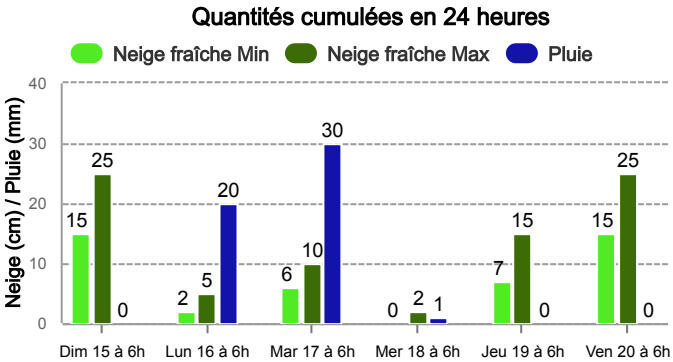

Tendance du vendredi 20 février

3

Indice de risque marqué

Risque accidentel en légère augmentation temporaire et fonction des quantités de neige supplémentaires attendues entre jeudi soir et vendredi matin, à réévaluer lors du prochain BERA.
Malgré la fin des chutes de neige et le retour d'un temps plus clément en journée de vendredi, la diminution du risque sera lente.

Pour consulter la vigilance en cours, veuillez vous rendre sur le site https://vigilance.meteofrance.fr/fr

Météo-France - 73 avenue de Paris, 94165 Saint-Mandé cedex - Contact : contact@meteo.fr

Rédigé par Météo-France avec la contribution des observateurs du réseau nivo-météorologiques. Partenariat : ANMSM (Maires de Stations de Montagne), DSF (Domaines Skiables de France), ADSP (Directeurs de Pistes et de la Sécurité des Stations de Sports d'Hiver) et autres acteurs de la montagne.

Bulletin neige & avalanches par téléphone au **0 892 68 10 20** Service 0,35 € / min + prix appel

RÉPUBLIQUE FRANÇAISE
Liberté Égalité Fraternité

METEO FRANCE
À VOS CÔTÉS, DANS UN CLIMAT QUI CHANGE

Bulletin d'estimation du risque d'avalanche

(valable en dehors des pistes balisées et ouvertes)

MASSIF : Luchonnais

Rédigé le mercredi 18 février 2026 à 16h

Conditions nivo-météo des 7 derniers jours

	jeu. 12/02				ven. 13/02				sam. 14/02				dim. 15/02				lun. 16/02				mar. 17/02				mer. 18/02			
	03h	09h	15h	21h	03h	09h	15h	21h	03h	09h	15h	21h	03h	09h	15h	21h	03h	09h	15h	21h	03h	09h	15h	21h	03h	09h	15h	21h
Météo																												
Vent (km/h)	120	120	90	70	85	75	100	115	85	60	65	40	35	40	80	90	90	85	75	80	60	55	60	65	55	80	95	85
à 3000m																												
Vent (km/h)	100	100	70	40	60	50	45	75	55	55	55	40	40	15	35	50	55	35	60	60	55	45	10	15	25	60	75	45
à 2000m																												

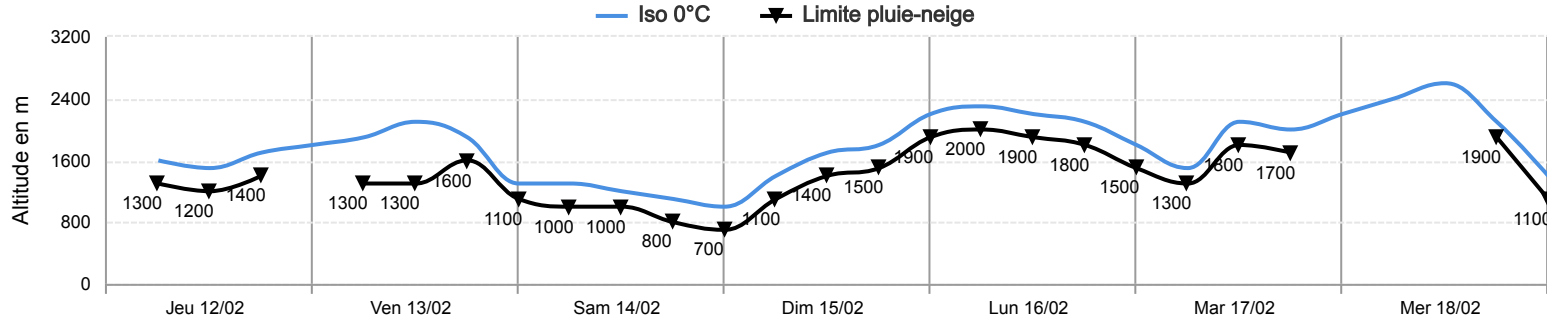

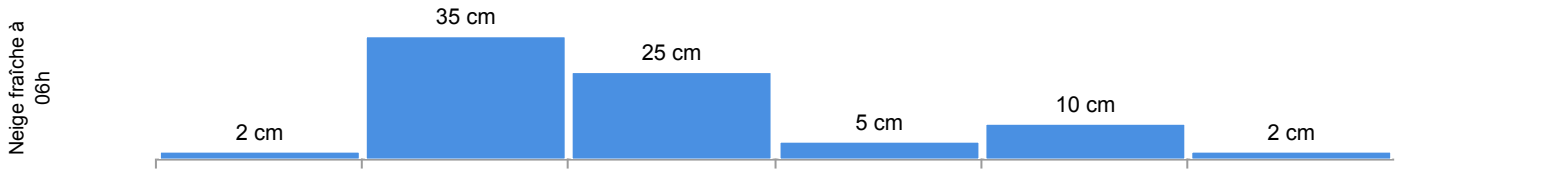

Risque d'avalanche	jeu. 12/02	ven. 13/02	sam. 14/02	dim. 15/02	lun. 16/02	mar. 17/02	mer. 18/02
	3	2	3	4	4	4	3

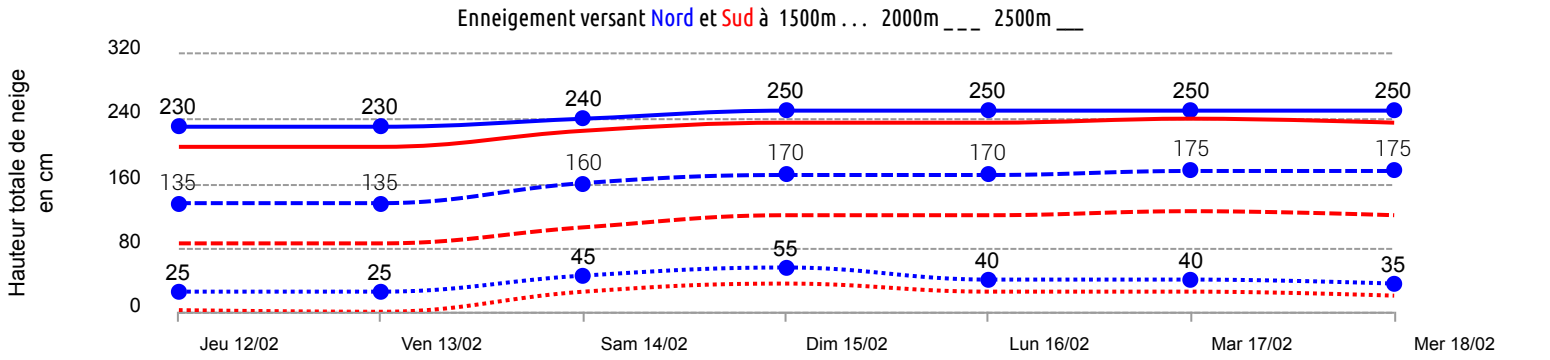

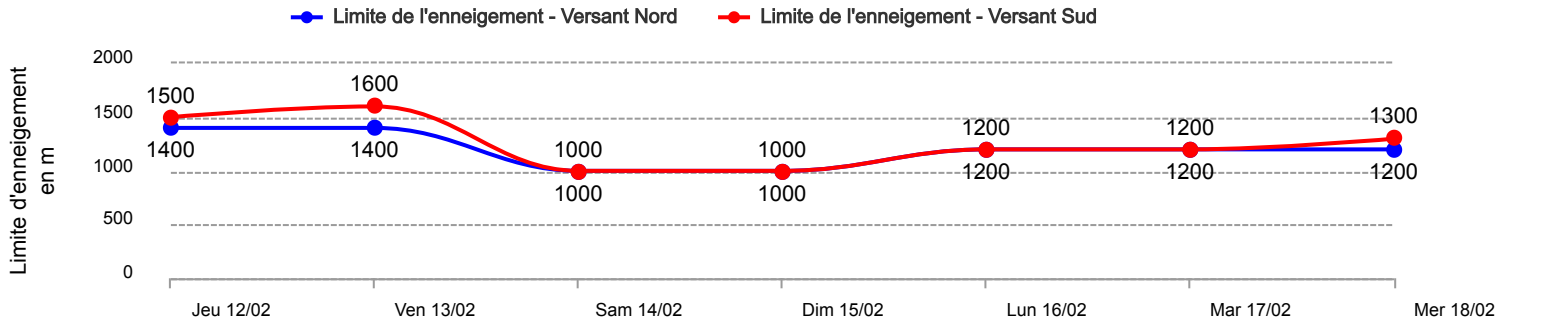

Pour consulter la vigilance en cours, veuillez vous rendre sur le site https://vigilance.meteofrance.fr/fr

Météo-France - 73 avenue de Paris, 94165 Saint-Mandé cedex - Contact : contact@meteo.fr

Bulletin neige & avalanches par téléphone au **0 892 68 10 20** Service 0,35 € / min + prix appel

Rédigé par Météo-France avec la contribution des observateurs du réseau nivo-météorologiques. Partenariat : ANMSM (Maires de Stations de Montagne), DSF (Domaines Skiables de France), ADSP (Directeurs de Pistes et de la Sécurité des Stations de Sports d'Hiver) et autres acteurs de la montagne.