Bulletin d'estimation du risque d'avalanche
(valable en dehors des pistes balisées et ouvertes)

MASSIF : Mercantour

Rédigé le mercredi 18 février 2026 à 16h

Estimation des risques pour le : JEUDI 19 FÉVRIER

NOMBREUSES NOUVELLES INSTABILITÉS DANS LA NEIGE FRAÎCHE VENTÉE

3

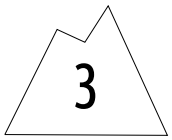

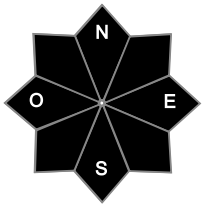

Indice de risque marqué.

Départs spontanés : nombreux départs pendant les chutes de neige, ou par transport par le vent.

Déclenchements provoqués : nombreuses instabilités dans la neige fraîche ventée.

Indices de risque : 5 très fort - 4 fort - 3 marqué - 2 limité - 1 faible -- En noir : les pentes les plus dangereuses

Stabilité du manteau neigeux

Situation avalancheuse typique : neige fraîche couche fragile persistante

Déclenchements provoqués :
nombreuses instabilités dans la neige fraîche et récente ventée, possibles en toutes orientations, mais plus fréquentes et plus épaisses au dessus de 1800/2000 m, même loin des crêtes. Les plaques formées en surface du manteau neigeux sont souvent d'aspect poudreux, ou parfois durci par le vent à l'approche des crêtes où elles sont réparties de manière plus hétérogène. Elles peuvent être faciles à déclencher au passage d'un seul skieur, engendrant des avalanches de taille petite à moyenne (taille 1 à 2), plus rarement grande (taille 3) dans les zones de forte accumulation où des quantités encore importantes de neige récente sont mobilisables.

Départs spontanés : nombreux départs possibles en pentes raides, en toutes orientations. Départs ponctuels en neige fraîche pendant les chutes, et également linaires en neige ventée sous l'effet du transport de neige par le vent de sud-ouest, puis nord-ouest en journée. Avalanches petites à moyennes en général.

Qualité de la neige

Enneigement très excédentaire pour un mois de février. Il faut remonter à 2015 pour trouver un enneigement encore plus abondant à cette période de l'année.
Données observées : 154 cm à la nivôse de Millefonts, 126 cm à Isola 2000.

Enneigement skiable dès 1300 m en ubacs en terrains favorables et 1600 m en adrets

État de la neige en surface :
jeudi matin, souvent 10/15 cm de neige fraîche modérément ventée. Elle repose sur une couche parfois épaisse de neige récente souvent durcie par le vent en altitude, restée légère et poudreuse en ubacs abrités du vent, notamment en forêts de moyenne altitude ; elle est plus tassée voire finement croûtée sous 2000/2200 m. En journée, transport et densification de la neige fraîche par le vent de nord-ouest.

Aperçu météo pour le jeudi 19 février

	nuit	matin	après-midi	soir

Neige temporairement modérée en seconde partie de nuit, puis averses en journée en Haute Tinée seulement, avec vent de nord-ouest se renforçant.

Pluie-Neige	1 200 m	1 100 m		
Iso 0 °C	2 000 m	1 900 m	2 100 m	1 900 m
Vent 2000 m	→ 30 km/h	↘ 35 km/h	↘ 35 km/h	↘ 45 km/h
Vent 3000 m	↗ 55 km/h	↘ 55 km/h	↘ 80 km/h	↓ 65 km/h

Épaisseur de neige hors-piste

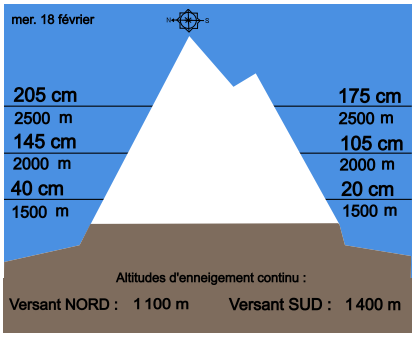

Précipitations à 1800 m

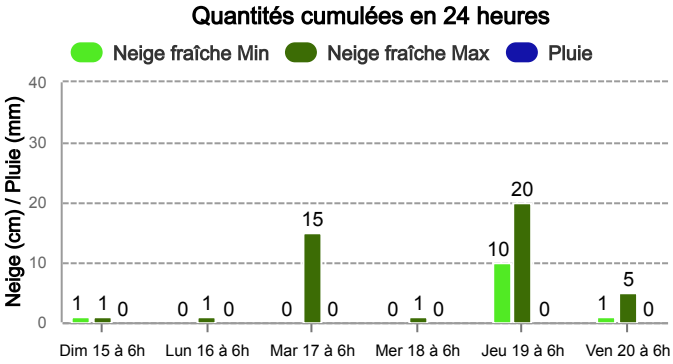

Tendance du vendredi 20 février

3 **Indice de risque marqué**

risque encore marqué, avec de nombreuses instabilités en place dans la neige récente, et de nouvelles se formant avec un vent de nord encore sensible le matin.

Pour consulter la vigilance en cours, veuillez vous rendre sur le site https://vigilance.meteofrance.fr/fr

Météo-France - 73 avenue de Paris, 94165 Saint-Mandé cedex - Contact : contact@meteo.fr

Rédigé par Météo-France avec la contribution des observateurs du réseau nivo-météorologiques. Partenariat : ANMSM (Maires de Stations de Montagne), DSF (Domaines Skiables de France), ADSP (Directeurs de Pistes et de la Sécurité des Stations de Sports d'Hiver) et autres acteurs de la montagne.

Bulletin neige & avalanches par téléphone au
0 892 68 10 20 Service 0,35 € / min + prix appel

RÉPUBLIQUE FRANÇAISE
Liberté Égalité Fraternité

METEO FRANCE
À VOS CÔTÉS, DANS UN CLIMAT QUI CHANGE

Bulletin d'estimation du risque d'avalanche

(valable en dehors des pistes balisées et ouvertes)

MASSIF : Mercantour

Rédigé le mercredi 18 février 2026 à 16h

Conditions nivo-météo des 7 derniers jours

	jeu. 12/02				ven. 13/02				sam. 14/02				dim. 15/02				lun. 16/02				mar. 17/02				mer. 18/02			
	03h	09h	15h	21h	03h	09h	15h	21h	03h	09h	15h	21h	03h	09h	15h	21h	03h	09h	15h	21h	03h	09h	15h	21h	03h	09h	15h	21h
Météo																												
Vent (km/h)	85	95	90	85	55	30	40	50	80	90	75	65	45	30	40	50	55	75	100	80	75	70	50	40	35	25	35	75
à 3000m																												
Vent (km/h)	40	65	45	40	30	20	25	20	50	75	65	50	30	10	20	30	30	40	65	40	60	50	20	20	15	15	20	40
à 2000m																												

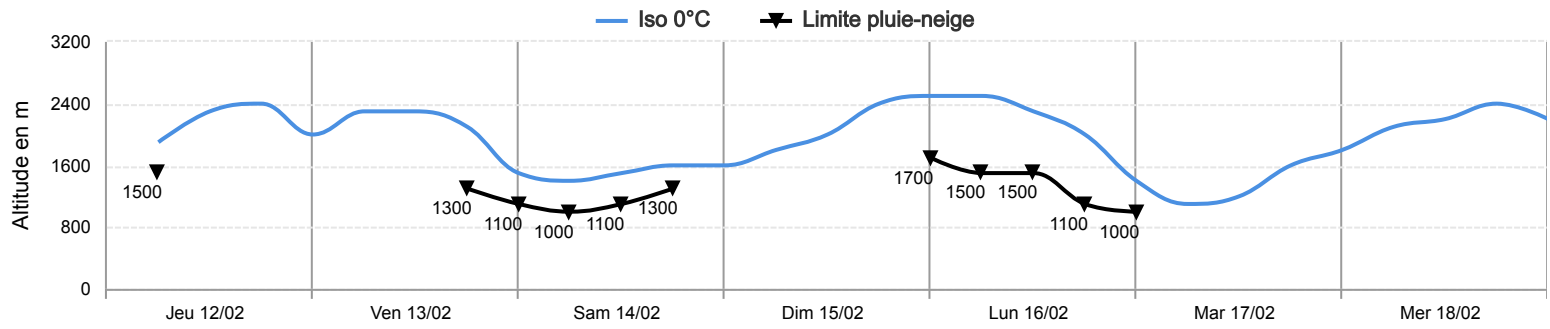

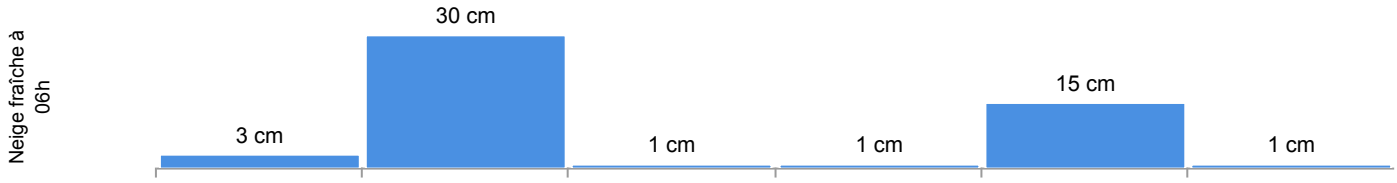

Risque d'avalanche	jeu. 12/02	ven. 13/02	sam. 14/02	dim. 15/02	lun. 16/02	mar. 17/02	mer. 18/02
	2	2	3	3	3	3	3

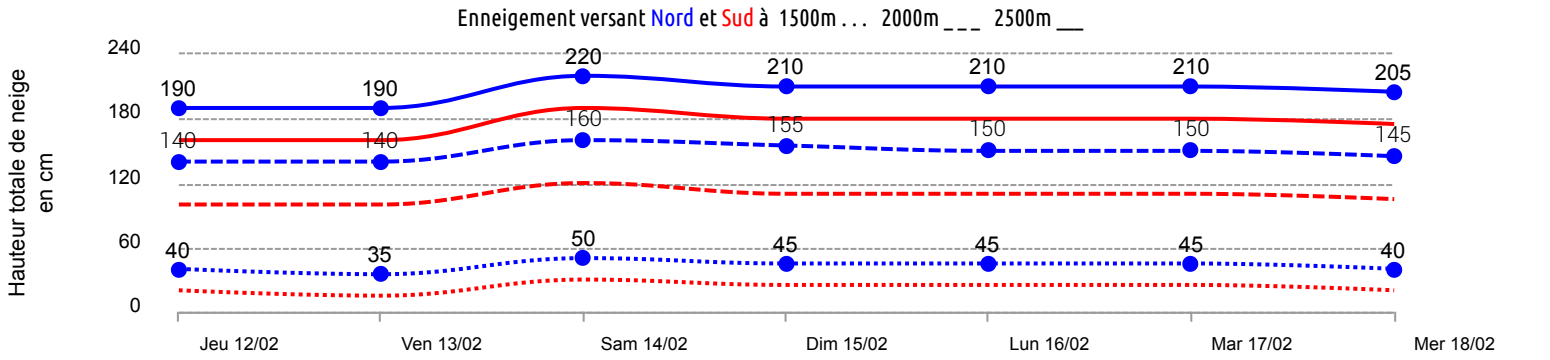

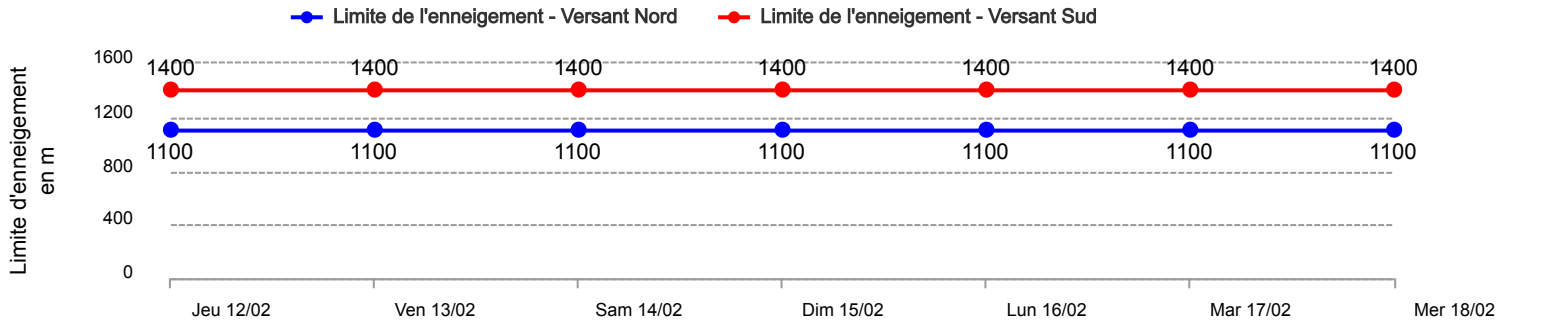

Pour consulter la vigilance en cours, veuillez vous rendre sur le site https://vigilance.meteofrance.fr/fr

Météo-France - 73 avenue de Paris, 94165 Saint-Mandé cedex - Contact : contact@meteo.fr

Rédigé par Météo-France avec la contribution des observateurs du réseau nivo-météorologiques. Partenariat : ANMSM (Maires de Stations de Montagne), DSF (Domaines Skiables de France), ADSP (Directeurs de Pistes et de la Sécurité des Stations de Sports d'Hiver) et autres acteurs de la montagne.

Bulletin neige & avalanches par téléphone au
0 892 68 10 20 Service 0,35 € / min + prix appel