Bulletin d'estimation du risque d'avalanche

(valable en dehors des pistes balisées et ouvertes)

MASSIF : Orlu St-Barthelemy

Rédigé le mercredi 18 février 2026 à 16h

Estimation des risques pour le : JEUDI 19 FÉVRIER

DÉGRADATION DES CONDITIONS, NOMBREUSES PLAQUES EN FORMATION.

3

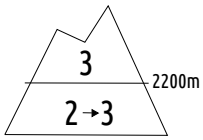

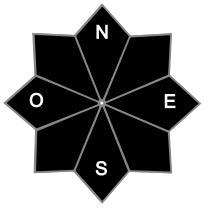

nouvelles plaques

Au-dessus de 2200m indice de risque marqué, plus bas indice limité évoluant en marqué.

Départs spontanés : Quelques départs linéaires par surcharge, départs ponctuels pendant les chutes.

Déclenchements provoqués : Nombreuses plaques en formation

Indices de risque : 5 très fort - 4 fort - 3 marqué - 2 limité - 1 faible -- En noir : les pentes les plus dangereuses

Stabilité du manteau neigeux

Situation avalancheuse typique : neige ventée neige fraîche

Déclenchements provoqués : De **nombreuses plaques déjà en place** en altitude avec le vent soutenu ce mercredi. Les chutes de neige ventées attendues cette nuit (10 à 15cm) dès 1200m d'altitude favorisent la formation de **nouvelles plaques** pouvant reposer sur une couche de neige fraîche moins ventée faisant office de couche fragile temporaire. Ces structures, encore assez fines jeudi matin, prendront de l'épaisseur au fil de la journée surtout l'après-midi avec le renforcement des chutes de neige. Elles sont facilement déclenchables.

Observables : Traces de montée disparaissant rapidement (chasse-neige), fissures devant les skis, Neige compacte sous le vent.

Départs spontanés : Quelques départs ponctuels peuvent se produire dans les pentes raides pendant les chutes de neige par accumulation. Il s'agit surtout de petites coulées ou avalanches de taille 1. De plus, par effet de surcharge, quelques plaques friables pourront céder spontanément.

Autres :

Qualité de la neige

Enneigement : Malgré l'épisode de fonte de lundi, l'enneigement reste largement supérieur à celui des cinq dernières années et se situe à un très bon niveau par rapport aux statistiques plus anciennes. La barre des 2m de neige est souvent atteinte dès 2000m d'altitude. Une nouvelle couche de neige devrait blanchir la montagne dès 1200 à 1300m puis l'enneigement augmente rapidement.

Qualité de la neige :
Une belle petite couche de neige fraîche devrait être présente en surface jeudi matin dès 1200 à 1300m et un sol simplement blanchi mais difficilement skiable en dessous. Cette neige repose sur un manteau compacté soit par la pluie du début de semaine jusqu'à 2200m, soit par le vent en altitude. On peut donc trouver un peu de poudreuse jeudi matin à l'abri du vent d'Ouest mais cette neige sera souvent irrégulière et cartonnée en prenant de l'altitude. Les crêtes et sommets peuvent se retrouver décapés par le vent violent.

Aperçu météo pour le jeudi 19 février

	nuit	matin	après-midi	soir
	Vent fort, chutes de neige et baisse des températures.			
Pluie-Neige	1 200 m	900 m	1 200 m	1 100 m
Iso 0 °C	2 200 m	1 400 m	1 700 m	1 600 m
Vent 2000 m	↘ 55 km/h	↘ 60 km/h	↘ 85 km/h	↘ 85 km/h
Vent 3000 m	→ 95 km/h	↘ 105 km/h	↘ 110 km/h	↘ 110 km/h

Épaisseur de neige hors-piste

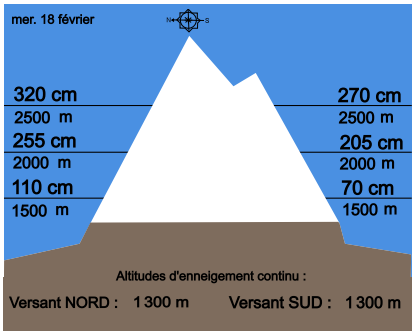

Précipitations à 1800 m

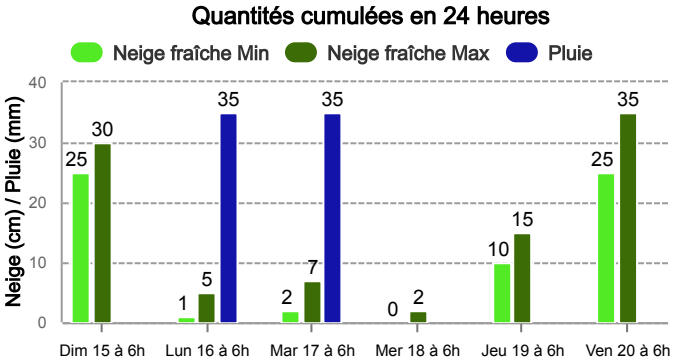

Tendance du vendredi 20 février

Indice de risque fort

Le passage à un risque 4 provoqué est envisagé pour vendredi si les quantités de neige fraîche ventée deviennent critiques...

Pour consulter la vigilance en cours, veuillez vous rendre sur le site https://vigilance.meteofrance.fr/fr

Météo-France - 73 avenue de Paris, 94165 Saint-Mandé cedex - Contact : contact@meteo.fr

Rédigé par Météo-France avec la contribution des observateurs du réseau nivo-météorologiques. Partenariat : ANMSM (Maires de Stations de Montagne), DSF (Domaines Skiables de France), ADSP (Directeurs de Pistes et de la Sécurité des Stations de Sports d'Hiver) et autres acteurs de la montagne.

Bulletin neige & avalanches par téléphone au

0 892 68 10 20 Service 0,35 € / min + prix appel

RÉPUBLIQUE FRANÇAISE
Liberté Égalité Fraternité

METEO FRANCE
À VOS CÔTÉS, DANS UN CLIMAT QUI CHANGE

Bulletin d'estimation du risque d'avalanche

(valable en dehors des pistes balisées et ouvertes)

MASSIF : Orlu St-Barthelemy

Rédigé le mercredi 18 février 2026 à 16h

Conditions nivo-météo des 7 derniers jours

	jeu. 12/02				ven. 13/02				sam. 14/02				dim. 15/02				lun. 16/02				mar. 17/02				mer. 18/02			
	03h	09h	15h	21h	03h	09h	15h	21h	03h	09h	15h	21h	03h	09h	15h	21h	03h	09h	15h	21h	03h	09h	15h	21h	03h	09h	15h	21h
Météo																												
Vent (km/h)	135	135	125	100	75	75	60	90	100	90	85	75	85	70	75	85	95	100	105	120	120	110	90	75	65	55	70	80
à 3000m																												
Vent (km/h)	95	90	85	60	40	55	40	65	80	65	70	60	70	45	45	55	50	65	80	85	85	65	50	40	30	25	35	50
à 2000m																												

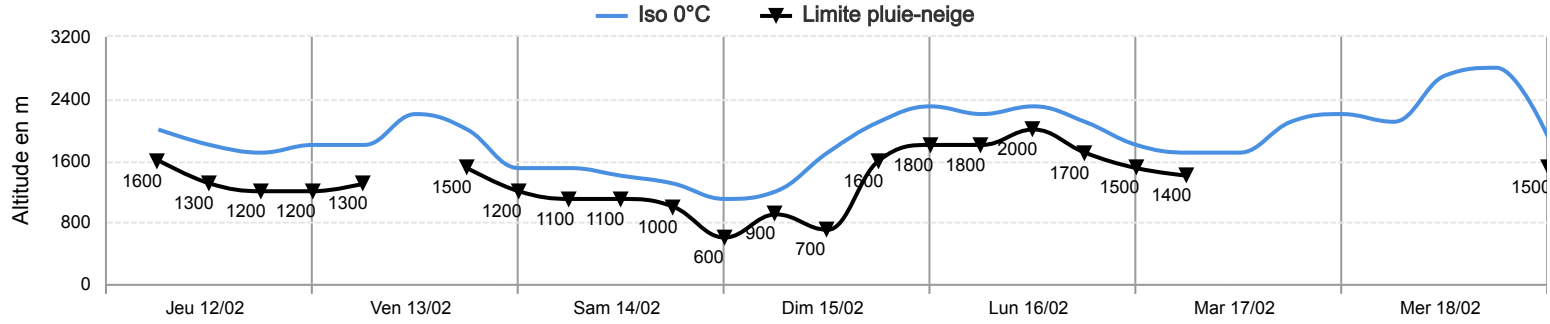



Risque d'avalanche	jeu. 12/02	ven. 13/02	sam. 14/02	dim. 15/02	lun. 16/02	mar. 17/02	mer. 18/02
	3	2	3	4	4	4	3

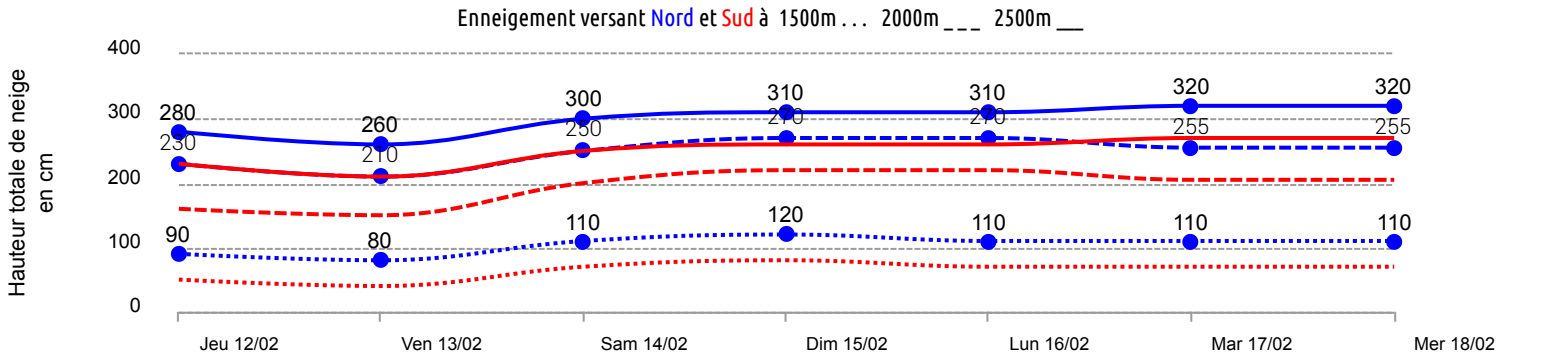

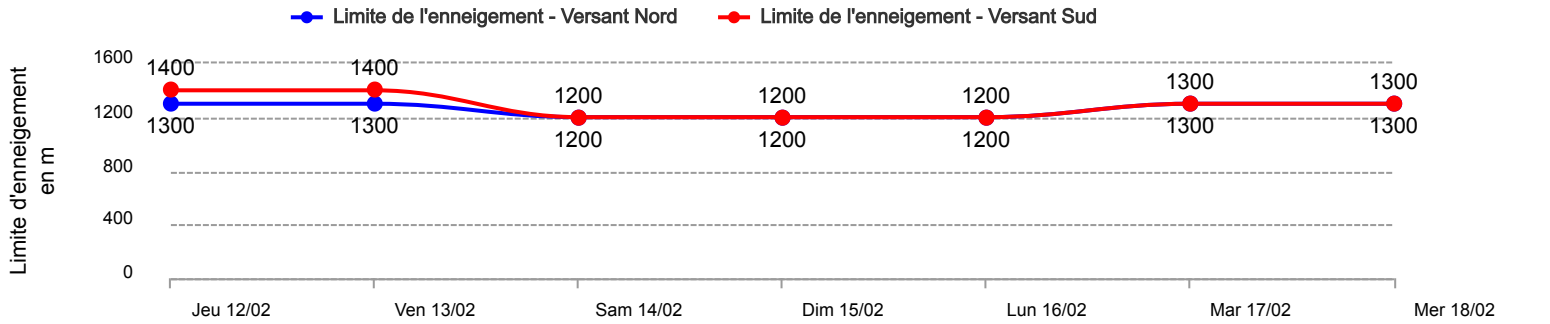

Pour consulter la vigilance en cours, veuillez vous rendre sur le site https://vigilance.meteofrance.fr/fr

Météo-France - 73 avenue de Paris, 94165 Saint-Mandé cedex - Contact : contact@meteo.fr

Bulletin neige & avalanches par téléphone au

0 892 68 10 20 Service 0,35 € / min + prix appel

Rédigé par Météo-France avec la contribution des observateurs du réseau nivo-météorologiques. Partenariat : ANMSM (Maires de Stations de Montagne), DSF (Domaines Skiables de France), ADSP (Directeurs de Pistes et de la Sécurité des Stations de Sports d'Hiver) et autres acteurs de la montagne.