Bulletin d'estimation du risque d'avalanche

(valable en dehors des pistes balisées et ouvertes)

MASSIF : Pelvoux

Rédigé le mercredi 18 février 2026 à 16h

Estimation des risques pour le : JEUDI 19 FÉVRIER

MANTEAU NEIGEUX TRÈS INSTABLE. FORMATION DE NOMBREUSES INSTABILITÉS DANS LA NEIGE FRAÎCHE VENTÉE - VIGILANCE ORANGE AVALANCHES

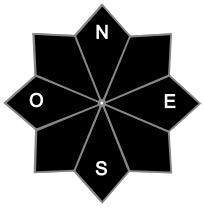

Indices de risque : 5 très fort - 4 fort - 3 marqué - 2 limité - 1 faible -- En noir : les pentes les plus dangereuses

Indice de risque fort.

Départs spontanés : nombreuses avalanches de neige fraîche pendant les chutes, départs parfois volumineux.

Déclenchements provoqués : nombreuses plaques dans la neige fraîche, facilement déclenchables.

Vigilance orange avalanches en cours ou prévue sur le massif

Stabilité du manteau neigeux

Situation avalancheuse typique : neige fraîche couche fragile persistante

Déclenchements provoqués : très nombreuses plaques dans la neige fraîche ventée. Elles sont présentes en toutes orientations, même jusqu'à basse altitude, et peuvent être facilement déclenchées par le passage d'un seul skieur. D'aspect poudreux dans les combes bien abritées du vent, elles sont difficilement identifiables. À proximité des crêtes et sommets, ces plaques sont plutôt durcies par le vent et réparties de manière plus hétérogène, avec des accumulations localement épaisses. Cassures épaisses, parfois sur de grandes largeurs, engendrant des avalanches de taille moyenne à grande (taille 2 à 3). Une très grande avalanche (taille 4) est possible en cas de sollicitation d'une couche fragile persistante enfouie en ubacs, emportant une grande partie du manteau neigeux en place. Ce type de départ peut être initié par la surcharge liée au passage d'une première avalanche de surface.

Départs spontanés : très nombreuses avalanches de neige fraîche au fil des chutes de neige ventées qui se déposent sur un manteau neigeux encore peu stabilisé. Avalanches de taille moyenne (taille 2) ou grande (taille 3) en cas de déstabilisation d'une plaque en place. Certaines avalanches peuvent être de grande ampleur et menacer des infrastructures de montagne ou atteindre certains fonds de vallées à plus basse altitude (Haute-Guisane et secteur Lautaret notamment). Avalanches de très grande taille (taille 4) dans ce cas.

Qualité de la neige

L'enneigement est excédentaire pour un mois de février, notamment à basse altitude. Les chutes de neige se succèdent depuis le début du mois de janvier.
Hauteurs de neige observées : 317 cm à la Nivôse de Écrins vers 3000 m, 246 cm au Pré de Mme Carle à 1900 m, 142 cm au hameau de Dormillouse à 1730 m.

Limite d'enneigement skiable : la plupart des itinéraires sont skiables dès les fonds de vallées.

État de la neige de surface : jeudi matin, les chutes de neige de la nuit ont apporté entre 20 et 30 cm et se poursuivent en journée. Elles apportent des quantités de neige plus importantes au cœur des Écrins, ainsi qu'en Haute-Guisane. Cette neige tombe froide et légère dans les endroits bien abrités du vent, mais est plus travaillée par le vent dans les endroits exposés. Crêtes souvent décapées par le vent de nord-ouest fort des derniers jours, alternant avec de grosses accumulations / corniches.

Aperçu météo pour le jeudi 19 février

	nuit	matin	après-midi	soir
Pluie-Neige	1 300 m	1 100 m	1 100 m	1 100 m
Iso 0 °C	1 600 m	1 500 m	1 500 m	1 500 m
Vent 2000 m	25 km/h	20 km/h	30 km/h	35 km/h
Vent 3000 m	40 km/h	35 km/h	45 km/h	55 km/h

Fortes chutes de neige en seconde partie de nuit. Maintien de chutes de neige en journée vers l'Isère. Vent de nord-ouest en altitude.

Épaisseur de neige hors-piste

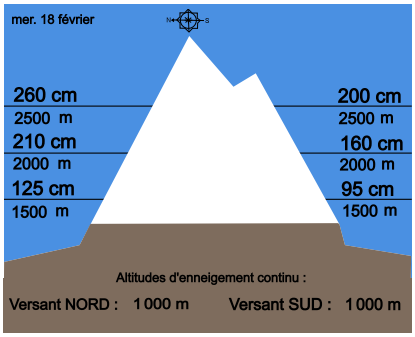

Précipitations à 1800 m

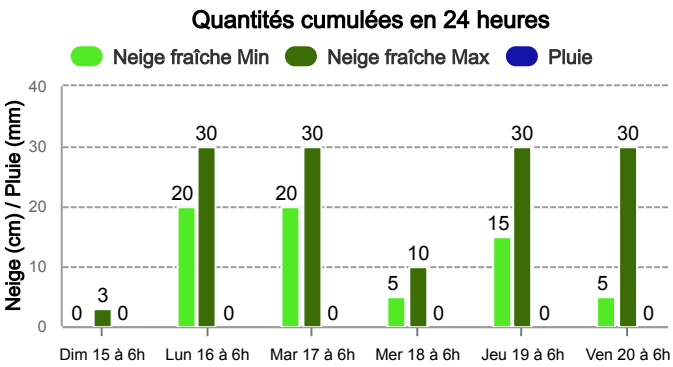

Tendance du vendredi 20 février

Indice de risque fort

Maintien d'un risque fort d'avalanches. Le fort vent de nord entraine la formation de nouvelles plaques faciles à déclencher.

Pour consulter la vigilance en cours, veuillez vous rendre sur le site https://vigilance.meteofrance.fr/fr

Météo-France - 73 avenue de Paris, 94165 Saint-Mandé cedex - Contact : contact@meteo.fr

Rédigé par Météo-France avec la contribution des observateurs du réseau nivo-météorologiques. Partenariat : ANMSM (Maires de Stations de Montagne), DSF (Domaines Skiables de France), ADSP (Directeurs de Pistes et de la Sécurité des Stations de Sports d'Hiver) et autres acteurs de la montagne.

Bulletin neige & avalanches par téléphone au **0 892 68 10 20** Service 0,35 € / min + prix appel

RÉPUBLIQUE FRANÇAISE
Liberté Égalité Fraternité

METEO FRANCE
À VOS CÔTÉS, DANS UN CLIMAT QUI CHANGE

Bulletin d'estimation du risque d'avalanche
(valable en dehors des pistes balisées et ouvertes)

MASSIF : Pelvoux

Rédigé le mercredi 18 février 2026 à 16h

Conditions nivo-météo des 7 derniers jours

	jeu. 12/02				ven. 13/02				sam. 14/02				dim. 15/02				lun. 16/02				mar. 17/02				mer. 18/02			
	03h	09h	15h	21h	03h	09h	15h	21h	03h	09h	15h	21h	03h	09h	15h	21h	03h	09h	15h	21h	03h	09h	15h	21h	03h	09h	15h	21h
Météo																												
Vent (km/h)	90	80	120	110	65	25	25	30	40	40	60	70	80	80	60	45	70	90	130	110	90	80	75	65	40	30	30	55
à 3000m	↘	↘	↘	↘	↘	↗	↖	↖	↙	↙	↘	↘	↓	↘	↘	→	→	→	↘	↘	↘	↘	↘	↘	↘	↘	↗	↑
Vent (km/h)	30	35	65	55	35	15	20	15	15	15	30	45	40	35	30	25	30	60	80	70	70	55	50	30	25	15	15	30
à 2000m	↗	↘	→	→	↘	↗	↖	←	←	↙	↓	↘	↓	→	↘	↘	→	↘	→	↘	↘	↘	↘	↘	↘	↘	↗	↗

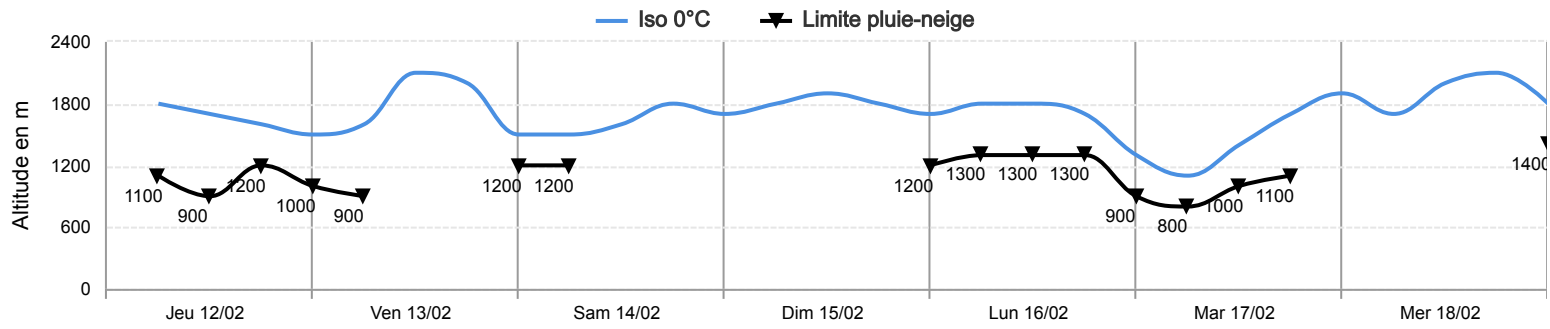

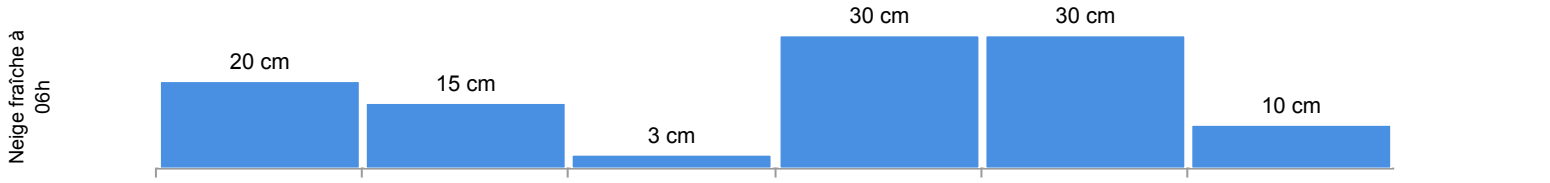

Risque d'avalanche	jeu. 12/02	ven. 13/02	sam. 14/02	dim. 15/02	lun. 16/02	mar. 17/02	mer. 18/02
	4	4	4	3	4	4	4

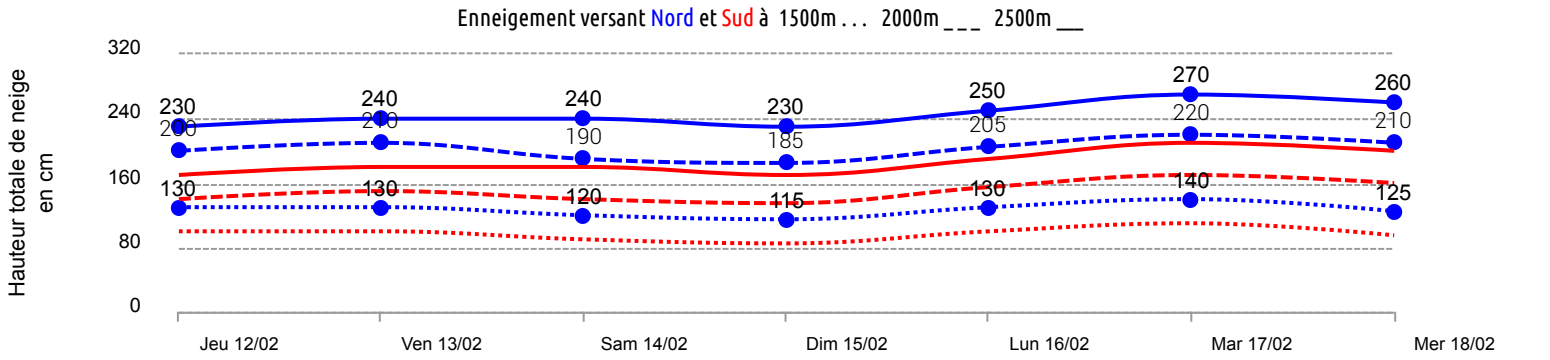

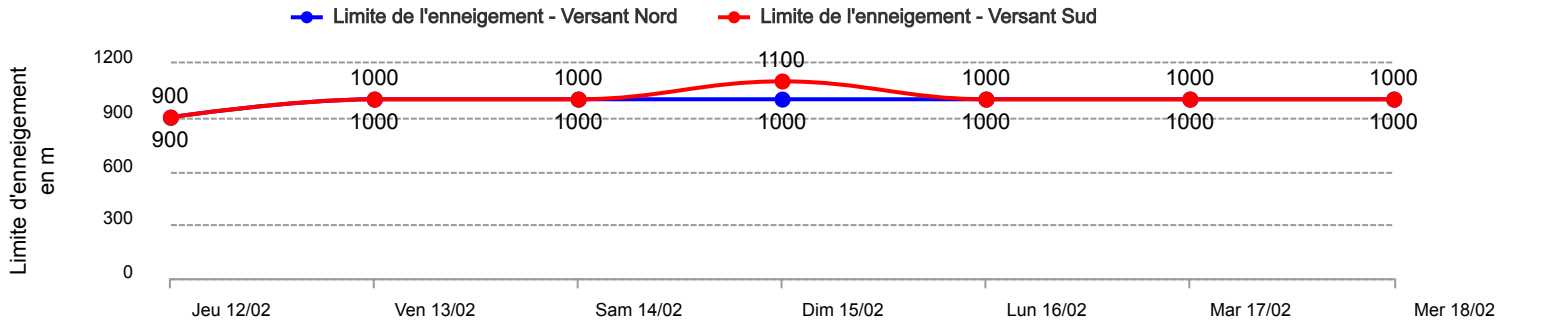

Pour consulter la vigilance en cours, veuillez vous rendre sur le site https://vigilance.meteofrance.fr/fr

Météo-France - 73 avenue de Paris, 94165 Saint-Mandé cedex - Contact : contact@meteo.fr

Bulletin neige & avalanches par téléphone au

0 892 68 10 20 Service 0,35 € / min + prix appel

Rédigé par Météo-France avec la contribution des observateurs du réseau nivo-météorologiques. Partenariat : ANMSM (Maires de Stations de Montagne), DSF (Domaines Skiables de France), ADSP (Directeurs de Pistes et de la Sécurité des Stations de Sports d'Hiver) et autres acteurs de la montagne.