GOBIERNO DE ESPAÑA
VICEPRESIDENCIA TERCERA DEL GOBIERNO
MINISTERIO PARA LA TRANSICIÓN ECOLÓGICA Y EL RETO DEMOGRÁFICO

Boletín de información nivológica y de peligro de aludes

Pirineo Navarro y Aragonés

aemet Agencia Estatal de Meteorología

jueves, 19 de febrero de 2026

Pronóstico hasta las 24 horas del viernes, día 20 de febrero

(Válido fuera de pistas de esquí balizadas y abiertas)

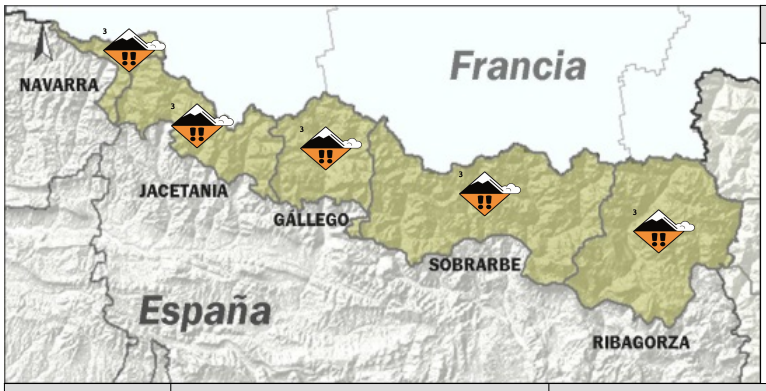

Problemas de aludes

Placas de viento

Nieve reciente

Macizo	Peligro	Problemas de aludes, cota, orientación, tamaño	Innivación observada (m)
Navarra	3 Notable	Placas de viento: 2000, N O E S, 2 Nieve reciente: N O E S, 2	2026-02-19 N S Cotas bajas
Jacetania	3 Notable	Placas de viento: 2000, N O E S, 2 Nieve reciente: N O E S, 2	2026-02-19 N S Cotas bajas
Gállego	3 Notable	Placas de viento: 2000, N O E S, 2 Nieve reciente: N O E S, 2	2026-02-19 N S Cotas bajas

AEMET. Se autoriza la reproducción de su contenido citando la fuente.

Boletín de información nivológica y de peligro de aludes

Pirineo Navarro y Aragonés

Sobrarbe	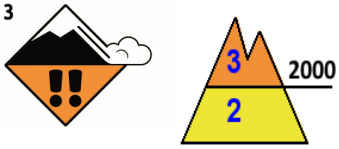 **Notable**	**Placas de viento** 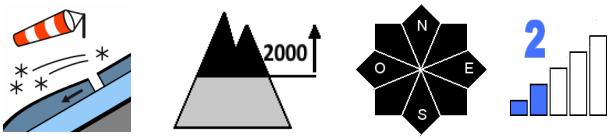 **Nieve reciente** 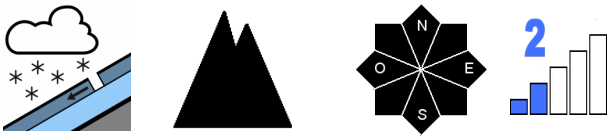	2026-02-19 Cotas bajas
Ribagorza	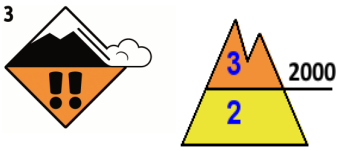 **Notable**	**Placas de viento** 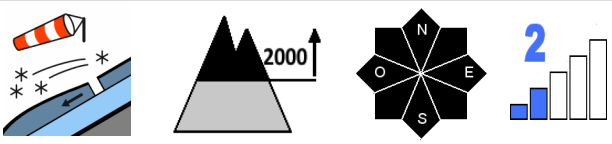 **Nieve reciente** 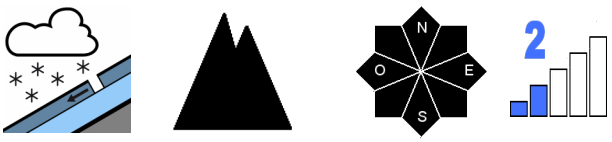	2026-02-19 Cotas bajas

Estado del manto y observaciones recientes

Ayer por la tarde comenzaron a producirse precipitaciones, que hasta las 08 UTC de hoy habían alcanzado en torno a 10-20 l/m2, localmente algo más, salvo en la Ribagorza donde rondaban los 5-10 l/m2, con la cota de nieve descendiendo ayer hasta unos 1100 metros y esta madrugada hasta unos 800 metros. También han soplado fuertes vientos del noroeste que han levantado ventiscas. Así, se han depositado algunos cm de nieve nueva, por lo general no más de 10 cm, aunque en algún punto de la red de observación se han superado los 25 cm. Las nevadas van a continuar durante el día de hoy, pudiendo acumularse otros 10-20 cm, incluso algo más en los macizos occidentales.

El manto es continuo desde fondos de valle y presenta espesores muy por encima de lo que sería habitual a estas alturas de la temporada. En torno a 2100 metros se superan fácilmente los 150-200 cm, aún más en ventisqueros, hoyas y otras zonas propensas a la acumulación.

En cotas medias y bajas el manto se ha humidificado en los últimos días, gracias a las lluvias y al ambiente más templado. En cotas altas la nieve se mantiene más seca y se han formado numerosas placas en muchas orientaciones, las más recientes en vertientes este y sur. Además, en las altas umbrías, todavía pueden persistir algunas capas débiles en el interior del manto, que podrían colapsar ante una sobrecarga, especialmente en zonas de poco espesor.

En las últimas 24 horas se han reportado 2 aludes pequeños en el Gállego, de placa friable, con salida a 2000-2250 metros y orientación sur, así como algunos disparos positivos.

Evolución del manto y peligro de aludes para el viernes, día 20

Problema de nieve reciente. Problema de placas de viento en cotas altas. En cotas bajas, especialmente en solanas, problema de nieve húmeda.

AEMET. Se autoriza la reproducción de su contenido citando la fuente.

Las nevadas van a continuar hasta el mediodía del viernes, sumando algunos centímetros más a los acumulados en las últimas horas. Durante todo el episodio se podrían alcanzar unos 20-30 cm nuevos en los macizos occidentales, y alrededor de 10-15 cm en los orientales, localmente más. Así, serán probables las purgas de nieve reciente en las laderas suficientemente inclinadas, de tamaño pequeño (riesgo de caída) o mediano (capaz de enterrar a una persona), sin descartar alguno de mayores dimensiones en las áreas de más acumulación. Con el paso de las horas la nubosidad se irá retirando, especialmente en el sector oriental y hacia el sur, y también subirán las temperaturas, por lo que también se podrán producir algunos aludes de nieve húmeda, principalmente en solanas de cotas bajas, por lo general pequeños.

En cotas altas existen placas de viento en muchas orientaciones, las más recientes en vertientes este y sur, y se formarán nuevas en las próximas horas, con preferencia a sotavento del flujo del noroeste, que todavía será muy intenso durante la primera mitad del día de mañana, viernes. Todas estas estructuras se mantendrán inestables, y podrán colapsar ante una sobrecarga débil (paso de un solo esquiador), ocasionando aludes de dimensión 1 o 2, aunque si se implica parte del manto subyacente podrían alcanzar tamaño suficiente como para enterrar a un grupo de personas, siendo esto más probable en umbrías, donde todavía las capas débiles persistentes pueden ser reactivas, especialmente en las zonas de poco espesor.

Predicción meteorológica para el viernes, día 20

Pirineo navarro:

Nuboso o muy nuboso, con nubes bajas que localmente podrán reducir la visibilidad. Al final del día se irán abriendo grandes claros, sobre todo en el sur, donde quedará poco nuboso. Se esperan precipitaciones, débiles en general, más frecuentes en el norte, que irán remitiendo por la tarde. Cota de nieve en torno a 1100 metros, subiendo a 1400 metros por la tarde. Temperaturas en ligero ascenso. Heladas débiles, moderadas en cotas altas. Viento fuerte del noroeste y norte, con rachas muy fuertes durante la primera mitad del día, perdiendo intensidad por la tarde.

Pirineo aragonés:

Nuboso o muy nuboso en los macizos occidentales y resto de la divisoria, con nubes bajas que localmente podrán reducir la visibilidad, e intervalos nubosos en las demás zonas. En el transcurso de la tarde se irán abriendo grandes claros, hasta quedar poco nuboso o despejado. Se esperan precipitaciones en los macizos occidentales y resto de la divisoria, por lo general débiles y durante la primera mitad del día, sin descartar algunas dispersas y ocasionales en las demás zonas. Cota de nieve en torno a 1100 metros, subiendo a 1400-1500 metros por la tarde. Temperaturas en ligero ascenso, localmente moderado en las máximas. Heladas débiles, moderadas en cotas altas, donde podrán ser localmente fuertes. Viento fuerte del noroeste y norte, con rachas muy fuertes en cotas altas y zonas expuestas durante la primera mitad del día, que podrían superar los 100 km/h, perdiendo intensidad por la tarde.

AEMET. Se autoriza la reproducción de su contenido citando la fuente.

Datos en la atmósfera libre:

Altitud de la isoterma de 0 ºC: 1700 m (W) - 2200 m (E)
Altitud de la isoterma de -10 ºC: 4500 m

Viento a 1500 m: N 40 km/h (W) - N 30 km/h (E)
Viento a 3000 m: NW 70 km/h

Evolución para el sábado día 21

Con la mayor insolación y el ascenso térmico tenderán a asentarse las placas de viento, pero se acentuará el problema de nieve húmeda.

(Información elaborada a partir de los datos recibidos de los refugios de Linza, Lizara, Panticosa, Bachimaña, Góriz, Pineta, Estós, Angel Orús, La Renclusa, Cap de Llauset y Belagua, de las estaciones de esquí de Candanchú, Astún, Formigal y Panticosa (lagos) y de la estación de esquí de fondo de Llanos del Hospital)

Escala europea de peligro de aludes

Débil | Limitado | Notable | Fuerte | Muy Fuerte

Problemas de aludes

Nieve reciente | Placas de viento | Capas débiles persistentes | Nieve húmeda | Deslizamientos basales | Sin problema evidente

Nota1: Se recuerda que, siempre que haya nieve, la ausencia total de peligro no existe. Hay que tener presente que en circunstancias desfavorables, con aludes de tamaño 1 (alud pequeño o colada) y tamaño 2 (alud mediano), se pueden sufrir severos daños personales.

Nota2: Los BPA se elaboran en base a información meteorológica así como al estado del manto nivoso a través de sondeos puntuales. Se advierte a los usuarios de la variabilidad de esta información al extrapolarla a zonas extensas de montaña. Por ello, AEMET no se hace responsable de su uso para la toma de decisiones que conciernen a la seguridad personal, ni de los riesgos físicos o materiales de ellas derivadas.

AEMET. Se autoriza la reproducción de su contenido citando la fuente.