Freitag 20.02.2026

Veröffentlicht am 19.02.2026 um 17:00

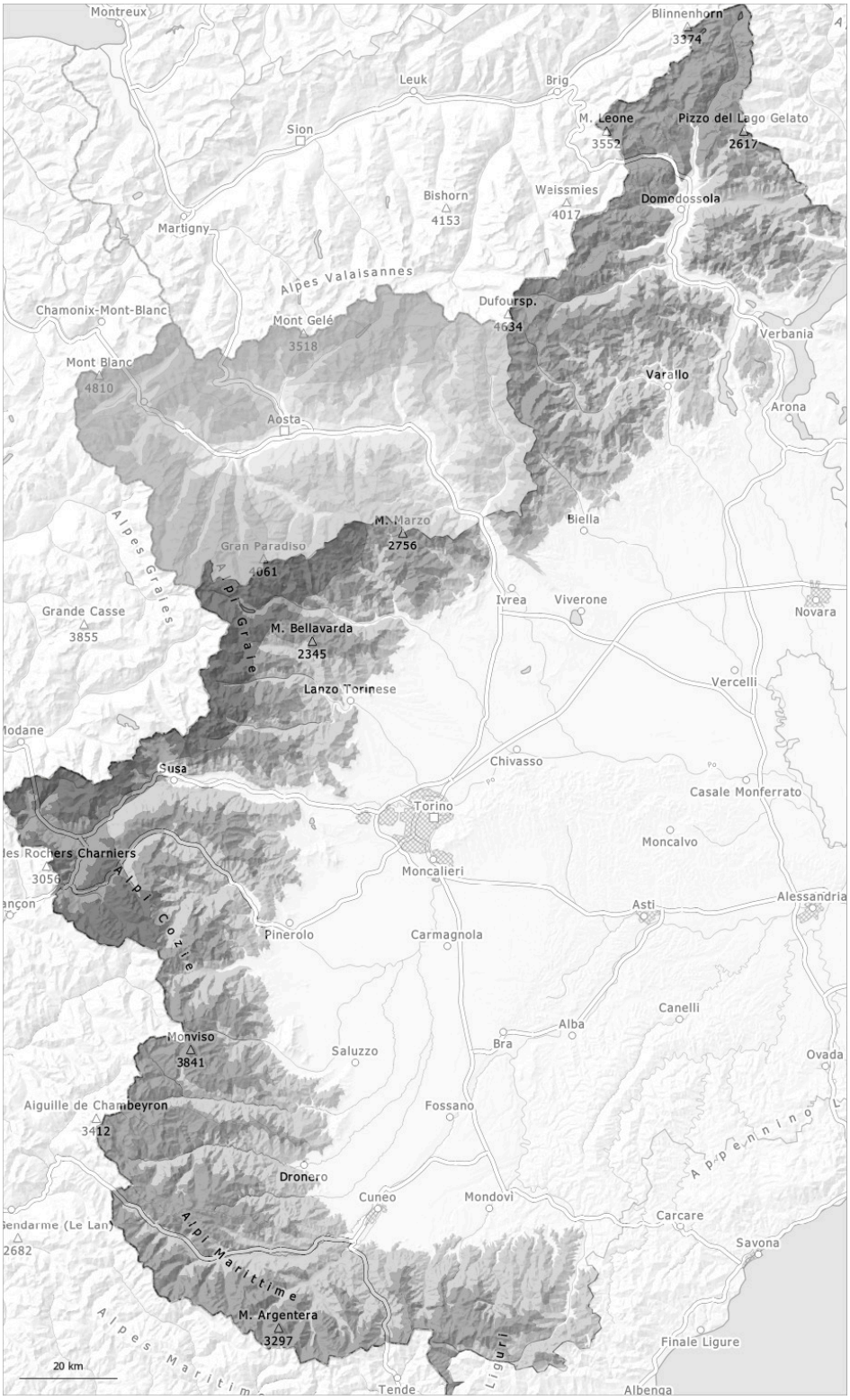

1	2	3	4	5
gering	mäßig	erheblich	groß	sehr groß

Gefahrenstufe 4 - Groß

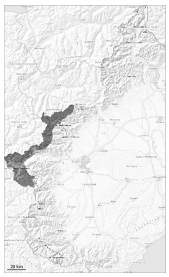

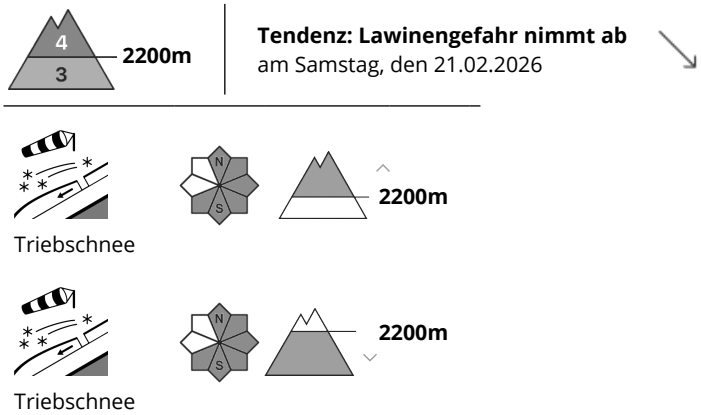

Mit Neuschnee und Wind gebietsweise noch gefährliche Lawinensituation.

Mit Schneefall und teils stürmischem Nordwestwind entstanden in den letzten Tagen frische Triebschneeansammlungen. Dies vor allem in den Föhngebieten oberhalb der Waldgrenze und in Kammlagen, Rinnen und Mulden.
Die störanfälligen Triebschneeansammlungen können schon von einzelnen Wintersportlern leicht ausgelöst werden.
Entlang der Grenze zu Frankreich sind die Gefahrenstellen weiter verbreitet und die Gefahr "groß", Stufe 4.

An Triebschneehängen und aus noch nicht entladenen Einzugsgebieten sind mit der Erwärmung einzelne große und vereinzelt sehr große Staublawinen möglich.

Schneedecke

Gefahrenmuster gm.6: lockerer schnee und wind

Seit Montag fielen gebietsweise verbreitet 60 bis 100 cm Schnee, lokal auch mehr. Gestern fielen in allen Höhenlagen verbreitet 15 bis 20 cm Schnee. Der teilweise stürmische Wind hat viel Schnee verfrachtet. V.a. in Gipfellagen liegen je nach Windeinfluss sehr unterschiedliche Schneehöhen.
Verschiedene Triebschneeschichten liegen stellenweise auf Oberflächenreif.
Die durchgeführten ECTs und Beobachtungen im Gelände bestätigten den schwachen Schneedeckenaufbau.

Tendenz

Die spontane Lawinenaktivität nimmt mit dem Abflauen des Windes allmählich ab.

Gefahrenstufe 3 - Erheblich

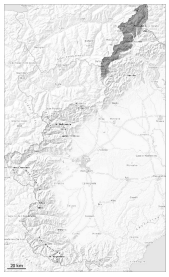

Tendenz: Lawinengefahr nimmt ab
am Samstag, den 21.02.2026

Triebschnee

Triebschnee ist die Hauptgefahr.

Mit Schneefall und teils stürmischem Nordwestwind entstanden in den letzten drei Tagen frische Triebschneeansammlungen. Dies vor allem in den Föhngebieten und im Bereich der Waldgrenze und in Rinnen, Mulden und hinter Geländekanten.
Die störanfälligen Triebschneeansammlungen können schon von einzelnen Wintersportlern leicht ausgelöst werden.

An Triebschneehängen und aus noch nicht entladenen Einzugsgebieten sind mit der Erwärmung mittlere und große trockene und feuchte Lawinen möglich.

Schneedecke

Gefahrenmuster gm.6: lockerer schnee und wind

Seit Montag fielen gebietsweise verbreitet 40 bis 80 cm Schnee, lokal auch mehr.
Der teilweise stürmische Wind hat viel Schnee verfrachtet.
V.a. in Gipfellagen liegen je nach Windeinfluss sehr unterschiedliche Schneehöhen.

In der Altschneedecke sind vor allem an steilen Nordwest-, Nord- und Osthängen störanfällige Schwachschichten vorhanden.

Gefahrenstufe 3 - Erheblich

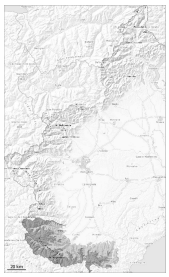

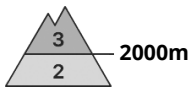

Tendenz: Lawinengefahr bleibt gleich
am Samstag, den 21.02.2026

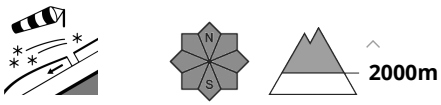

Triebschnee

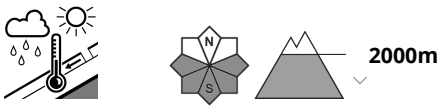

Nassschnee

Schneebrettlawinen sind die Hauptgefahr. Feuchte und nasse Lawinen sind in der zweiten Tageshälfte möglich.

Mit starkem Nordwestwind entstanden in den letzten Tagen frische Triebschneeansammlungen.
Vor allem mittlere und hohe Lagen sowie in windgeschützten Lagen: Weiche Triebschneeansammlungen können im Bereich der Waldgrenze von einzelnen Wintersportlern ausgelöst werden. Die Triebschneeansammlungen sind gut erkennbar.
Vor allem steile Sonnenhänge und Felswandfüße: Mit der Erwärmung sind mittlere und vereinzelt große trockene und feuchte Lawinen möglich.

Schneedecke

Gefahrenmuster gm.6: lockerer schnee und wind

Gestern fielen in allen Höhenlagen verbreitet 15 bis 20 cm Schnee. Der starke Wind hat Neu- und Altschnee verfrachtet.
V.a. in Gipfellagen liegen je nach Windeinfluss sehr unterschiedliche Schneehöhen. Schattenhänge: Die Schneedecke ist trocken, mit einer lockeren Oberfläche.
Sonnenhänge: Die Sonneneinstrahlung führt im Tagesverlauf zu einer zunehmenden Anfeuchtung der Schneedecke.

Gefahrenstufe 3 - Erheblich

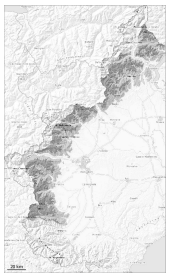

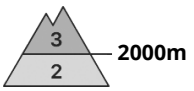

Tendenz: Lawinengefahr bleibt gleich
am Samstag, den 21.02.2026

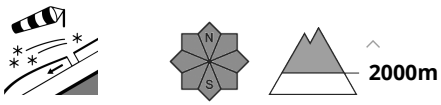

Triebschnee

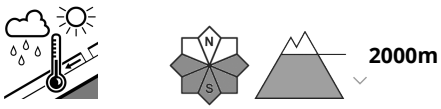

Nassschnee

Schneebrettlawinen sind die Hauptgefahr.

Der teilweise starke Wind hat den Neuschnee intensiv verfrachtet. Mit starkem Nordwestwind entstanden in den letzten Tagen frische Triebschneeansammlungen.
Vor allem mittlere und hohe Lagen sowie in windgeschützten Lagen: Weiche Triebschneeansammlungen können im Bereich der Waldgrenze von einzelnen Wintersportlern ausgelöst werden. Die Triebschneeansammlungen sind gut erkennbar.
Vor allem steile Sonnenhänge und Felswandfüße: Mit der Erwärmung sind kleine und mittlere trockene und feuchte Lawinen möglich.

Schneedecke

Gefahrenmuster gm.6: lockerer schnee und wind

Gestern fielen in allen Höhenlagen verbreitet 15 bis 20 cm Schnee. Der starke Wind hat Neu- und Altschnee verfrachtet.
V.a. in Gipfellagen liegen je nach Windeinfluss sehr unterschiedliche Schneehöhen. Sonnenhänge: Die Sonneneinstrahlung führt im Tagesverlauf zu einer zunehmenden Anfeuchtung der Schneedecke.