Freitag 20.02.2026

Veröffentlicht am 19.02.2026 um 17:00

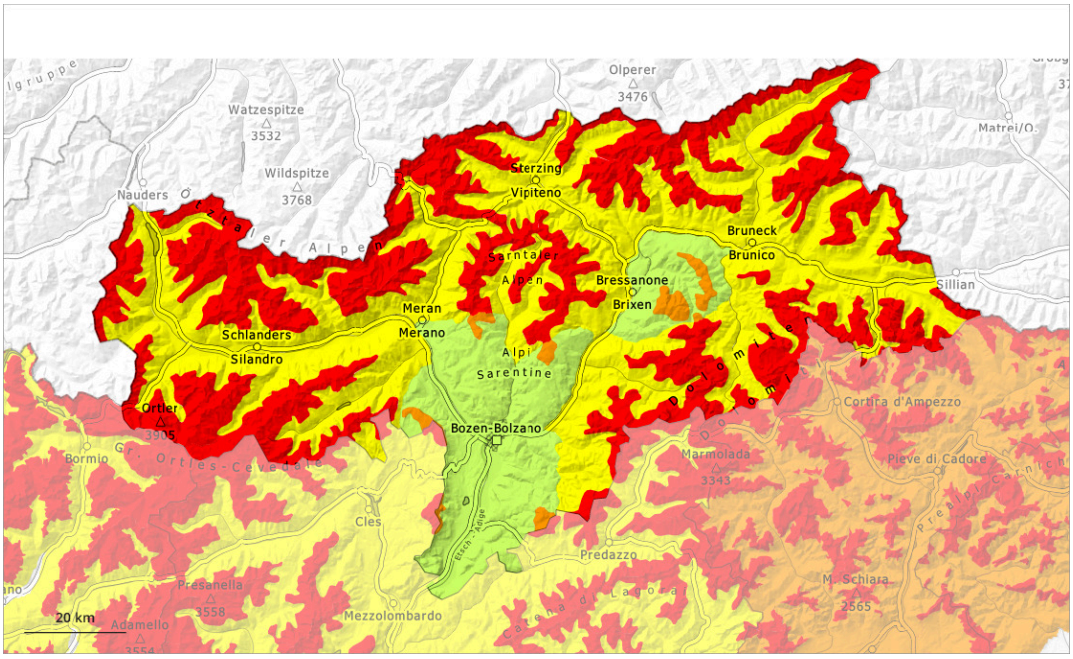

1	2	3	4	5
gering	mäßig	erheblich	groß	sehr groß

Gefahrenstufe 4 - Groß

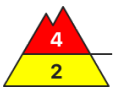

Waldgrenze

Tendenz: Lawinengefahr bleibt gleich
am Samstag, den 21.02.2026

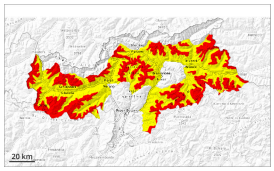

Altschnee

Waldgrenze

Triebschnee

Waldgrenze

Neuschnee

Waldgrenze

Abseits gesicherter Pisten sehr gefährliche Lawinensituation. Die Gefährdung bezieht sich vor allem auf alpines Schneesportgelände.

Triebschneeansammlungen sind an allen Expositionen oberhalb der Waldgrenze sehr störanfällig, Vorsicht auch im Bereich der Waldgrenze. Lawinen können in oberflächennahen Schichten der Schneedecke ausgelöst werden.
Zudem können Lawinen auch in bodennahe Schichten der Schneedecke durchreißen und an West-, Nord- und Osthängen groß werden. Wummgeräusche und Risse beim Betreten der Schneedecke sowie frische Lawinen sind Alarmzeichen und weisen auf die Gefahr hin. Fernauslösungen sind möglich.

Mit dem starken bis stürmischen Nordföhn sind weiterhin spontane Lawinen zu erwarten. Dies aus sehr steilen windabgewandten Einzugsgebieten, v.a. an Felswandfüßen und hinter Geländekanten.

An sehr steilen Hängen sind kleine und mittlere Lockerschneelawinen möglich.

Schneedecke

Gefahrenmuster gm.1: bodennahe schwachschicht | gm.6: lockerer schnee und wind

Seit Donnerstag fielen 20 bis 40 cm Schnee. Am Freitag bläst der Wind stark bis stürmisch.
Der Wind verfrachtet den Neuschnee. Es entstehen weitere Triebschneeansammlungen.

Die Schneedecke ist verbreitet störanfällig. Neu- und Triebschnee überlagern eine schwache Altschneedecke. Schon etwas ältere Triebschneeansammlungen liegen auf Oberflächenreif. Im unteren Teil der Altschneedecke sind ausgeprägte Schwachschichten vorhanden. Dies vor allem an West-, Nord- und Osthängen oberhalb der Waldgrenze.

Tendenz

Die Verhältnisse abseits der Pisten sind sehr gefährlich. Schwachschichten im Altschnee sind die Hauptgefahr.

Gefahrenstufe 4 - Groß

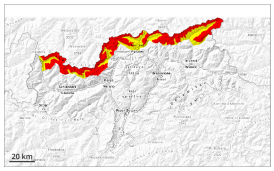

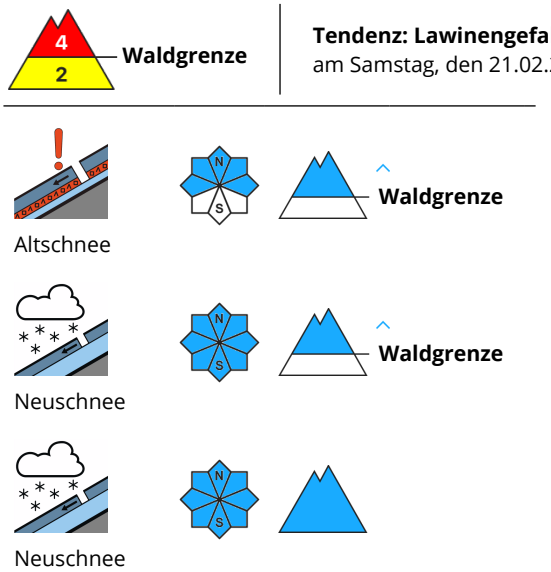

Sehr gefährliche Lawinensituation. Die Gefährdung bezieht sich vor allem auf alpines Schneesportgelände.

Der viele Neuschnee und die mit dem starken Westwind entstehenden, umfangreichen Triebschneeansammlungen sind an allen Expositionen oberhalb der Waldgrenze sehr störanfällig. Solche Gefahrenstellen liegen auch im Bereich der Waldgrenze.

Mit Neuschnee und Wind sind bis in die Nacht hinein spontane Lawinen zu erwarten. Lawinen können teilweise in tiefe Schichten durchreißen und groß werden. Dies an West-, Nord- und Osthängen.

Die spontane Lawinenaktivität nimmt mit dem Ende der Schneefälle langsam ab. Vor allem in den Föhngebieten sind mit dem starken bis stürmischen Nordwestwind weiterhin spontane Lawinen möglich. Vorsicht vor allem in windabgewandten Einzugsgebieten.

Schneedecke

Gefahrenmuster gm.1: bodennahe schwachschicht | gm.6: lockerer schnee und wind

Bis am Vormittag fallen gebietsweise 10 bis 20 cm Schnee. Der Wind bläst mäßig bis stark. Der Wind bläst vor allem in den Südlichen Zillertaler Alpen und den Hohen Tauern und entlang der Grenze zu Südtirol zeitweise stürmisch. Der Wind verfrachtet den Neuschnee. Es entstehen weitere Triebschneeansammlungen.

Die Schneedecke ist verbreitet störanfällig. Neu- und Triebschnee überlagern eine schwache Altschneedecke. Schon etwas ältere Triebschneeansammlungen liegen auf Oberflächenreif. Im unteren Teil der Altschneedecke sind ausgeprägte Schwachschichten vorhanden. Dies vor allem an West-, Nord- und Osthängen oberhalb der Waldgrenze.

Tendenz

Es fällt gebietsweise etwas Schnee. Der Regen führt in tiefen und mittleren Lagen zu einer Aufweichung der Schneedecke. Mit teils stürmischem Wind aus westlichen Richtungen entstehen am Samstag weitere Triebschneeansammlungen.
Die Verhältnisse für Schneesport abseits gesicherter Pisten bleiben sehr gefährlich. Lawinen können sehr leicht ausgelöst werden. Es sind weiterhin spontane Lawinen möglich.

Gefahrenstufe 3 - Erheblich

Waldgrenze

Tendenz: Lawinengefahr bleibt gleich
am Samstag, den 21.02.2026

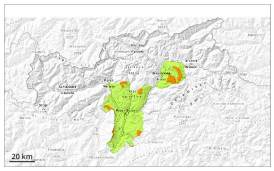

Altschnee

Waldgrenze

Triebschnee

Waldgrenze

Frischen Triebschnee kritisch beurteilen. Schwachschichten im Altschnee können vereinzelt ausgelöst werden.

Schwachschichten im Altschnee können besonders im selten befahrenen Gelände vereinzelt von einzelnen Wintersportlern ausgelöst werden. Vorsicht vor allem an steilen West-, Nord- und Osthängen oberhalb der Waldgrenze. Die Gefahrenstellen sind schwer zu erkennen. Lawinen sind meist mittelgroß.

Zudem sind die Triebschneeansammlungen in Rinnen, Mulden und hinter Geländekanten teils noch störanfällig. Solche Gefahrenstellen liegen an Nord-, Ost- und Südosthängen oberhalb der Waldgrenze.

Zurückhaltung ist angebracht.

Schneedecke

Gefahrenmuster gm.1: bodennahe schwachschicht | gm.8: eingeschneiter oberflächenreif

Seit Donnerstag fielen 10 bis 20 cm Schnee, lokal auch mehr. Bis am Vormittag fallen gebietsweise 10 bis 20 cm Schnee. Der Wind bläst lokal stark bis stürmisch.
Der teilweise stürmische Wind verfrachtet den Neuschnee. Es entstehen teils störanfällige Triebschneeansammlungen.

Die Schneedecke ist teilweise störanfällig. Neu- und Triebschnee überlagern eine schwache Altschneedecke. Dies vor allem an West-, Nord- und Osthängen oberhalb der Waldgrenze.

Tendenz

Schwachschichten im Altschnee sind die Hauptgefahr.