Venerdì 20.02.2026

Pubblicato il 19.02.2026 alle ore 17:00

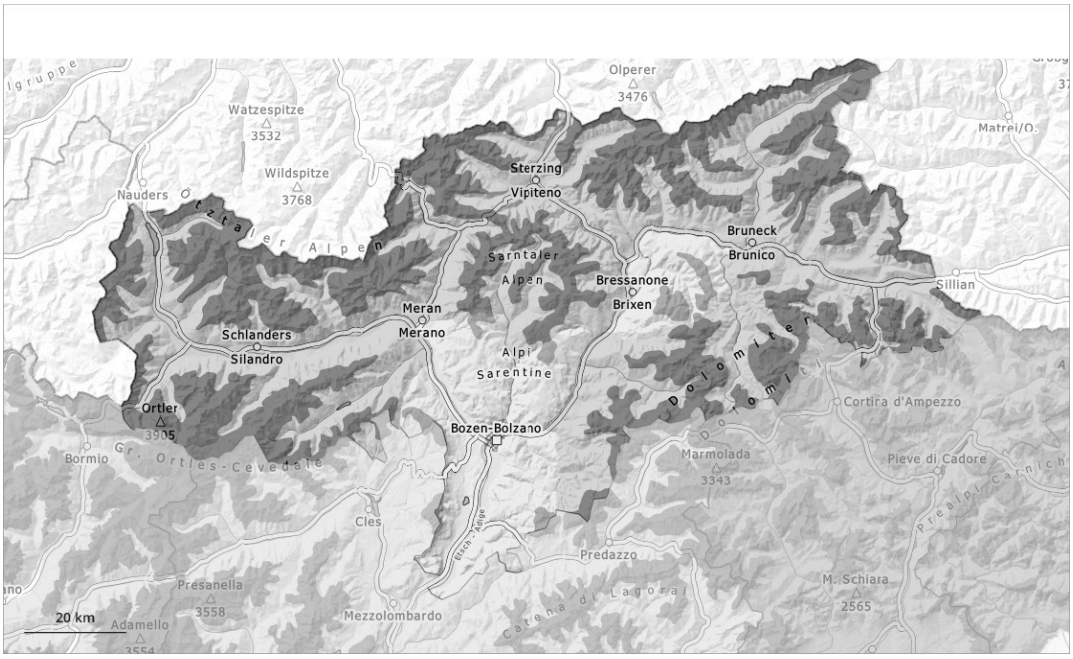

1	2	3	4	5
debole	moderato	marcato	forte	molto forte

Grado di pericolo 4 - Forte

Limite del bosco

Tendenza: pericolo valanghe stabile
per Sabato il 21.02.2026

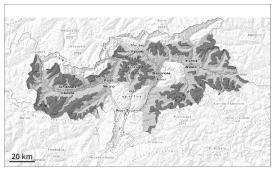

Strati deboli persistenti

Limite del bosco

Lastrone da vento

Limite del bosco

Neve fresca

Limite del bosco

Al di fuori delle piste assicurate, la situazione valanghiva è molto pericolosa. Il pericolo si riferisce principalmente alle zone alpine frequentate dagli appassionati di sport invernali.

Gli accumuli di neve ventata sono molto instabili a tutte le esposizioni al di sopra del limite del bosco, attenzione, anche in prossimità del limite del bosco. Le valanghe possono distaccarsi coinvolgendo gli strati superficiali del manto.
Inoltre, le valanghe possono anche distaccarsi coinvolgendo gli strati basali del manto e, sui pendii esposti a ovest, nord ed est, raggiungere grandi dimensioni. I rumori di "whum" e la formazione di fessure quando si calpesta la coltre di neve così come nuove valanghe sono campanelli di allarme che rimandano a questo pericolo. Sono possibili distacchi a distanza.

Con il Föhn da nord da forte a tempestoso, sono ancora previste valanghe spontanee. Ciò dai bacini di alimentazione molto ripidi riparati dal vento, principalmente ai piedi di pareti rocciose e dietro ai cambi di pendenza.

Sui pendii molto ripidi sono possibili valanghe di neve a debole coesione di piccole e medie dimensioni.

Manto nevoso

Situazione tipo st.1: strato debole persistente basale | st.6: neve a debole coesione e vento

Da giovedì sono caduti da 20 a 40 cm di neve. Venerdì il vento sarà da forte a tempestoso.
Il vento causerà il trasporto della neve fresca. Si formeranno ulteriori accumuli di neve ventata.

Il manto nevoso è instabile in molti punti. La neve fresca e la neve ventata ricoprono un debole manto di neve vecchia. Gli accumuli di neve ventata meno recenti poggiano su brina di superficie. Nella parte basale del manto di neve vecchia si trovano pronunciati strati fragili. Ciò soprattutto sui pendii esposti a ovest, nord ed est al di sopra del limite del bosco.

Tendenza

Le condizioni al di fuori delle piste sono molto pericolose. Gli strati deboli presenti nella neve vecchia rappresentano la principale fonte di pericolo.

Grado di pericolo 4 - Forte

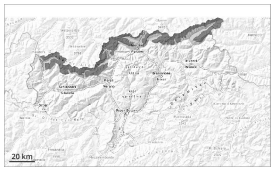

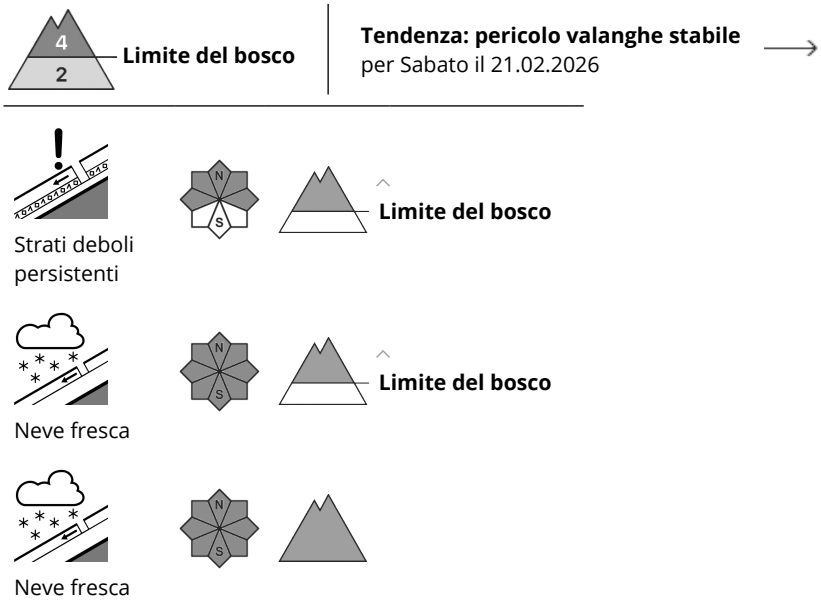

La situazione valanghiva è molto pericolosa. Il pericolo si riferisce principalmente alle zone alpine frequentate dagli appassionati di sport invernali.

L'abbondante neve fresca e gli accumuli di neve ventata che si formeranno con il vento proveniente da ovest di forte intensità ed estesi sono molto instabili a tutte le esposizioni al di sopra del limite del bosco. Tali punti pericolosi si trovano anche in prossimità del limite del bosco.

Con neve fresca e vento, sino alla notte sono previste valanghe spontanee. Le valanghe possono in parte coinvolgere gli strati più profondi e raggiungere grandi dimensioni. Ciò sui pendii esposti a ovest, nord ed est.

Con il cessare delle nevicate, l'attività di valanghe spontanee diminuirà lentamente. Con il vento proveniente da nord ovest da forte a tempestoso, soprattutto nelle aree esposte al Föhn sono ancora possibili valanghe spontanee. Attenzione soprattutto ai bacini di alimentazione riparati dal vento.

Manto nevoso

Situazione tipo st.1: strato debole persistente basale | st.6: neve a debole coesione e vento

In alcune aree fino alla mattinata cadranno da 10 a 20 cm di neve. Il vento sarà da moderato a forte. Soprattutto sulle Alpi della Zillertal meridionali e Alti Tauri e lungo il confine con l'Alto Adige, il vento sarà a tratti tempestoso. Il vento causerà il trasporto della neve fresca. Si formeranno ulteriori accumuli di neve ventata.

Il manto nevoso è instabile in molti punti. La neve fresca e la neve ventata ricoprono un debole manto di

neve vecchia. Gli accumuli di neve ventata meno recenti poggiano su brina di superficie. Nella parte basale del manto di neve vecchia si trovano pronunciati strati fragili. Ciò soprattutto sui pendii esposti a ovest, nord ed est al di sopra del limite del bosco.

Tendenza

In alcune aree, cadrà un po' di neve. La pioggia causerà alle quote di bassa e media montagna un ammorbidimento del manto nevoso. Con vento a tratti tempestoso proveniente dai quadranti occidentali nella giornata di sabato si formeranno ulteriori accumuli di neve ventata.
Le condizioni per gli sport invernali al di fuori delle piste assicurate rimangono molto pericolose. Le valanghe possono distaccarsi molto facilmente. Sono ancora possibili valanghe spontanee.

Grado di pericolo 3 - Marcato

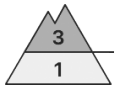

Limite del bosco

Tendenza: pericolo valanghe stabile
per Sabato il 21.02.2026

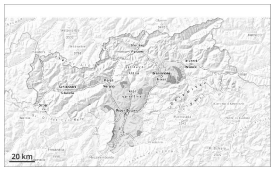

Strati deboli persistenti

Limite del bosco

Lastrone da vento

Limite del bosco

La neve ventata recente deve essere valutata con spirito critico. Gli strati deboli presenti nella neve vecchia possono distaccarsi a livello isolato.

Principalmente nelle zone poco frequentate, gli strati deboli presenti nella neve vecchia possono distaccarsi a livello isolato in seguito al passaggio di un singolo appassionato di sport invernali. Attenzione soprattutto sui pendii ripidi esposti a ovest, nord ed est al di sopra del limite del bosco. I punti pericolosi sono difficili da individuare. Le valanghe sono per lo più di dimensioni medie.

Inoltre nelle conche, nei canaloni e dietro ai cambi di pendenza gli accumuli di neve ventata sono in parte ancora instabili. Tali punti pericolosi si trovano sui pendii esposti a nord, est e sud est al di sopra del limite del bosco.

È consigliata prudenza.

Manto nevoso

Situazione tipo st.1: strato debole persistente basale | st.8: brina di superficie sepolta

Da giovedì sono caduti da 10 a 20 cm di neve, localmente anche di più. In alcune aree fino alla mattinata cadranno da 10 a 20 cm di neve. Il vento sarà localmente da forte a tempestoso.
Il vento a tratti tempestoso causerà il trasporto della neve fresca. Si formeranno accumuli di neve ventata in parte instabili.

Il manto nevoso è instabile in alcuni punti. La neve fresca e la neve ventata ricoprono un debole manto di neve vecchia. Ciò soprattutto sui pendii esposti a ovest, nord ed est al di sopra del limite del bosco.

Tendenza

Gli strati deboli presenti nella neve vecchia rappresentano la principale fonte di pericolo.