ICGC Institut Cartogràfic i Geològic de Catalunya

Servei Meteorològic de Catalunya meteo.cat

# Boletín de peligro de aludes para el Pirineo de Catalunya
# Del 19/02/2026 al 20/02/2026

(Válido fuera pistas de esquí y zonas no controladas)

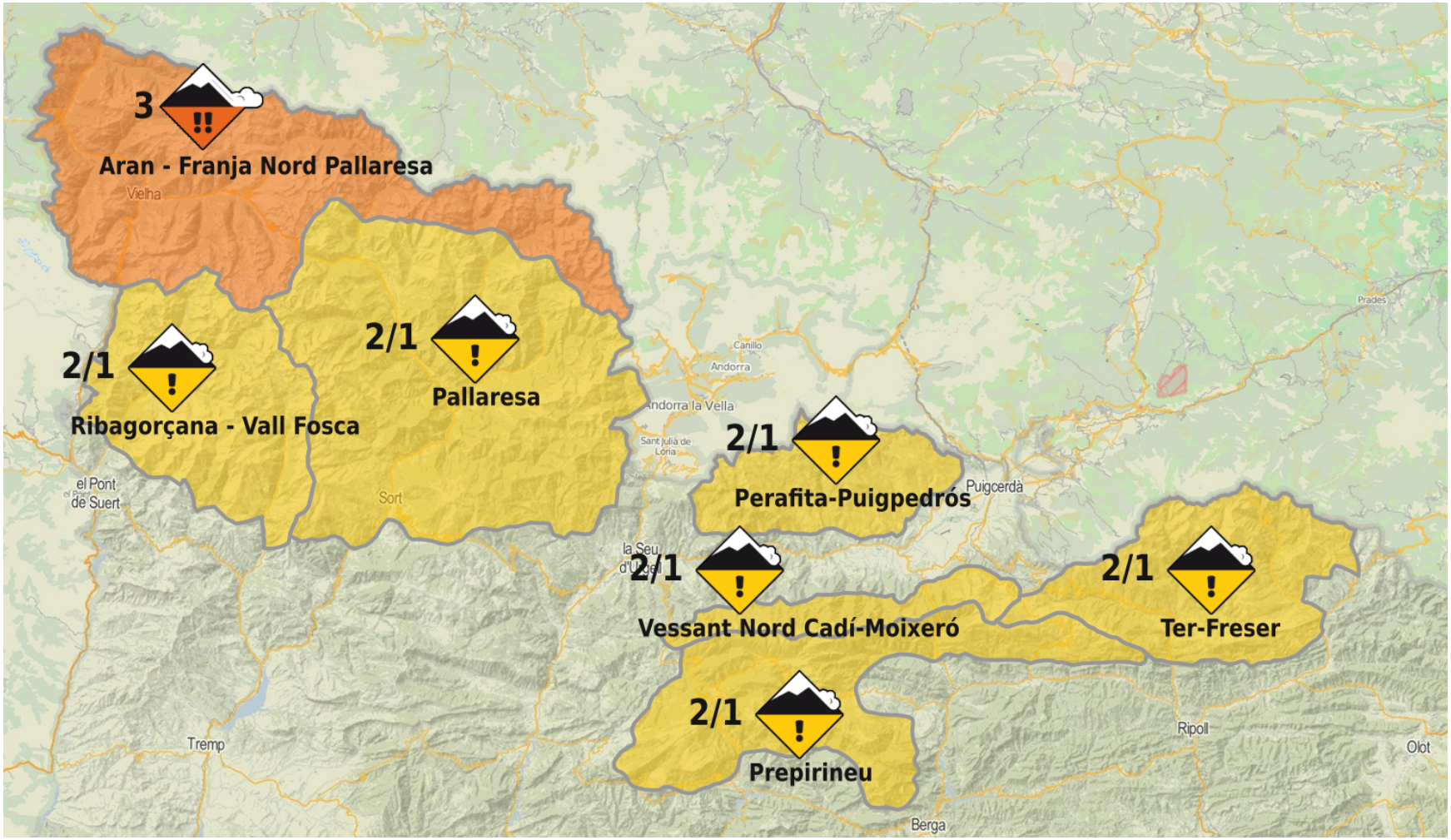


| 5 MUY FUERTE | 4 FUERTE | 3 NOTABLE | 2 LIMITADO | 1 DÉBIL |
|---|---|---|---|---|

ICGC Institut Cartogràfic i Geològic de Catalunya

meteo.cat Servei Meteorològic de Catalunya

# Boletín de peligro de aludes Aran - Franja Nord Pallaresa Del 19/02/2026 al 20/02/2026

(Válido fuera pistas de esquí y zonas no controladas)

NOTABLE (3)

## Situación primaria

**Nieve venteada**

**Distribución**

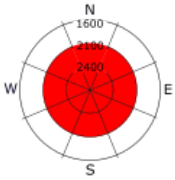


**Tamaño**

**Origen**

**Tendencia**

## Situación secundaria

**Nieve reciente**

**Distribución**

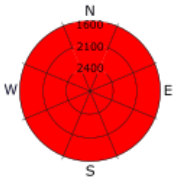


**Tamaño**

**Origen**

**Tendencia**

**Estado del manto nivoso**

El jueves, con las precipitaciones poco abundantes hasta la tarde y fuerte viento, se ha observado transporte efectivo de nieve. El transporte de nieve continuará hasta mañana viernes por la mañana con la continuación de la nevada seca y el fuerte viento de NW-N.

Con estas condiciones, se forman nuevas placas en cualquier orientación, más frecuentes en S y E, y por encima de unos 2.000 m. Se encontrarán sobre todo bajo collados y crestas y cubetas resguardadas. Se mostrarán muy reactivas y sensibles, pudiendo ceder tanto por sobrecarga débil como a veces de forma natural. Por lo general podrán alcanzar tamaño medio, pero localmente alguna podría llegar a tamaño grande.

Por otra parte, se esperan también aludes de nieve reciente, sobre todo en vertientes de pendiente moderada o fuerte, donde el viento no haya trabajado demasiado. Estos aludes serán de tamaño pequeño o medio, y se podrán dar en cualquier orientación y cota.

**Distribución del manto nivoso**

El nuevo episodio de nieve podrá dejar nieve en el suelo por encima de unos 800-1.000 m y incrementar los espesores en cotas medias y altas no afectadas por el fuerte viento. Los espesores a unos 2.200 m son superiores a los normales y rondan los 120-140 cm en el norte de Arán y los 160-200 cm en la Franja Norte Pallaresa y en el sur de Aran.

**Tendencia para las próximas 48-72h**

Las placas tenderán a estabilizarse progresivamente y podrán aparecer problemas de nieve húmeda. Peligro: en leve DESCENSO.

**El próximo boletín será emitido el día 2026-02-20**

| | | | | |
|---|---|---|---|---|
| 5 MUY FUERTE | 4 FUERTE | 3 NOTABLE | 2 LIMITADO | 1 DÉBIL |

EAWS EUROPEAN AVALANCHE WARNING SERVICES

ICGC Institut Cartogràfic i Geològic de Catalunya

Servei Meteorològic de Catalunya meteo.cat

# Boletín de peligro de aludes Ribagorçana - Vall Fosca Del 19/02/2026 al 20/02/2026

(Válido fuera pistas de esquí y zonas no controladas)

LIMITADO (2), sobre todo en el extremo N por encima del límite de bosque. DÉBIL (1), en el resto.

**Situación primaria**

**Nieve venteada**

**Distribución**

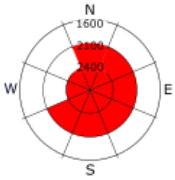


**Tamaño**

**Origen**

**Tendencia**

**Estado del manto nivoso**

El manto se encuentra endurecido superficialmente por la presencia de costras o nieve venteada compacta. Pese a la poca disponibilidad de nieve transportable, el nuevo episodio de precipitaciones y viento fuerte de N y NW del jueves y el viernes provocará la formación de nuevas placas de viento, especialmente en el extremo N, el sector más afectado por este nuevo episodio.

Estas placas se encontrarán principalmente en orientaciones E y S, por encima del bosque, bajo collados y cordales y en cuencas más resguardadas. Serán por lo general placas de poco grosor, pero muy sensibles y podrán ser desencadenadas muy fácilmente por sobrecarga débil, por ejemplo, al paso de una persona. Se pueden esperar aludes de tamaño pequeño, o de tamaño medio allí donde las sobreacumulaciones de nieve venteada sean mayores o se formen sobre placas antiguas. Localmente, algún alud podría llegar a tamaño 3, grande.

La ventisca recomienda circular con mucha prudencia.

**Distribución del manto nivoso**

Hay nieve en el suelo a 1.500 m. El manto es esquiable por encima de unos 1500-1600 m. Los grosores alcanzan los 130-160 cm. Estos valores son muy superiores a los normales en la época.

**Tendencia para las próximas 48-72h**

Las placas tenderán a estabilizarse progresivamente y podrá existir nuevos problemas de nieve húmeda. Peligro: en leve DESCENSO.

**El próximo boletín será emitido el día 2026-02-20**

| | | | | |
|---|---|---|---|---|
| 5 MUY FUERTE | 4 FUERTE | 3 NOTABLE | 2 LIMITADO | 1 DÉBIL |

EAWS EUROPEAN AVALANCHE WARNING SERVICES

ICGC Institut Cartogràfic i Geològic de Catalunya

Servei Meteorològic de Catalunya meteo.cat

# Boletín de peligro de aludes Pallaresa
# Del 19/02/2026 al 20/02/2026

(Válido fuera pistas de esquí y zonas no controladas)

LIMITADO (2), sobre todo en el extremo N por encima del límite de bosque. DÉBIL (1), en el resto.

**Situación primaria**

**Nieve venteada**

**Distribución**

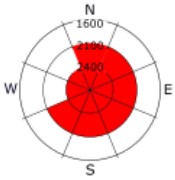


**Tamaño**

**Origen**

**Tendencia**

**Estado del manto nivoso**

El manto se encuentra endurecido superficialmente por la presencia de costras o nieve venteada compacta. Pese a la poca disponibilidad de nieve transportable, el nuevo episodio de precipitaciones y viento fuerte de N y NW del jueves y el viernes provocará la formación de nuevas placas de viento, especialmente en el extremo N, el sector más afectado por este nuevo episodio.

Estas placas se encontrarán principalmente en orientaciones E y S, por encima del bosque, bajo collados y cordales y en cuencas más resguardadas. Serán por lo general placas de poco grosor, pero muy sensibles y podrán ser desencadenadas muy fácilmente por sobrecarga débil, por ejemplo, al paso de una persona. Se pueden esperar aludes de tamaño pequeño, o de tamaño medio allí donde las sobreacumulaciones de nieve venteada sean mayores o se formen sobre placas antiguas. Localmente, algún alud podría llegar a tamaño 3, grande.

La ventisca recomienda circular con mucha prudencia.

**Distribución del manto nivoso**

Hay nieve en el suelo a 1.500 m. El manto es esquiable por encima de unos 1500-1600 m. Los grosores alcanzan los 130-160 cm. Estos valores son muy superiores a los normales para la época.

**Tendencia para las próximas 48-72h**

Las placas tenderán a estabilizarse progresivamente pero aparecerán problemas de nieve húmeda. Peligro: en leve DESCENSO.

**El próximo boletín será emitido el día 2026-02-20**

| | | | | |
|---|---|---|---|---|
| 5 MUY FUERTE | 4 FUERTE | 3 NOTABLE | 2 LIMITADO | 1 DÉBIL |

EAWS EUROPEAN AVALANCHE WARNING SERVICES

ICGC Institut Cartogràfic i Geològic de Catalunya

Servei Meteorològic de Catalunya

# Boletín de peligro de aludes Perafita-Puigpedrós Del 19/02/2026 al 20/02/2026

(Válido fuera pistas de esquí y zonas no controladas)

LIMITADO (2), sobre todo en el extremo N por encima del límite de bosque. DÉBIL (1), en el resto.

**Situación primaria**

**Nieve venteada**

**Distribución**

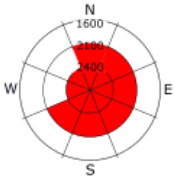


**Tamaño**

**Origen**

**Tendencia**

**Estado del manto nivoso**

En el extremo N del sector principalmente, las precitaciones más frecuentes y el viento fuerte de N y NW de jueves y viernes, dará lugar a la formación de nuevas placas de viento en orientaciones E y S preferentemente, por encima del límite del bosque, bajo collados y crestas y sectores más resguardados con sobreacumulaciones.
Las placas de nueva formación tendrán poco grosor en general pero serán sensibles y podrán ser desencadenadas muy fácilmente de forma accidental. Se pueden esperar aludes de tamaño 1, pequeño, en general, o hasta tamaño medio, donde las sobreacumulaciones locales de nieve venteada sean mayores o impliquen placas antiguas.
La ventisca y la mala visibilidad, especialmente en cotas altas, recomienda circular con mucha prudencia.

**Distribución del manto nivoso**

Hay nieve en el suelo por encima de 1.400-1500 m. Sin embargo, el manto es esquiable por encima de 1.500-1.600 m. Los grosores alcanzan los 130-150 cm a 2.200 m. Son grosores muy por encima de los habituales para la época.

**Tendencia para las próximas 48-72h**

Las placas tenderán a estabilizarse progresivamente, pero aparecerán problemas de nieve húmeda. Peligro: en leve DESCENSO.

**El próximo boletín será emitido el día 2026-02-20**

| | | | | |
|---|---|---|---|---|
| 5 MUY FUERTE | 4 FUERTE | 3 NOTABLE | 2 LIMITADO | 1 DÉBIL |

EAWS EUROPEAN AVALANCHE WARNING SERVICES

ICGC Institut Cartogràfic i Geològic de Catalunya

Servei Meteorològic de Catalunya meteo.cat

# Boletín de peligro de aludes
# Vessant Nord Cadí-Moixeró
# Del 19/02/2026 al 20/02/2026

(Válido fuera pistas de esquí y zonas no controladas)

LIMITADO (2), por encima del límite de bosque. DÉBIL (1), por debajo.

**Situación primaria**

**Nieve venteada**

**Distribución**

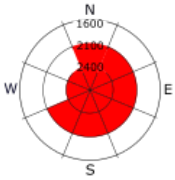


**Tamaño**

**Origen**

**Tendencia**

**Estado del manto nivoso**

Durante el jueves y el viernes por la mañana, con el fuerte viento de N y NW y las precipitaciones de nieve, habrá transporte de nieve efectivo. Con estas condiciones, se formarán nuevas placas de viento por encima del límite de bosque preferentemente, en orientaciones E y S sobre todo, bajo collados y cordales y en las canales resguardadas.

Por lo general, las placas de nueva formación serán de poco grosor, pero serán sensibles y podrán ser desencadenadas muy fácilmente de forma accidental. Se pueden esperar aludes de tamaño 1, pequeño, en general, o hasta tamaño medio, donde las sobreacumulaciones locales de nieve venteada sean mayores o impliquen manto antiguo.

Se recomienda prudencia al circular por la montaña por la presencia de ventisca.

**Distribución del manto nivoso**

Hay manto continuo por encima de unos 1.600 m y esquiable por encima de unos 1.700 m. Los espesores están alrededor de 150-170 cm en cotas medias. Estos valores son muy excedentarios para la época del año.

**Tendencia para las próximas 48-72h**

Las placas tenderán a estabilizarse progresivamente, pero aparecerán problemas de nieve húmeda. Peligro: en leve DESCENSO.

**El próximo boletín será emitido el día 2026-02-20**

| | | | | |
|---|---|---|---|---|
| 5 MUY FUERTE | 4 FUERTE | 3 NOTABLE | 2 LIMITADO | 1 DÉBIL |

EAWS EUROPEAN AVALANCHE WARNING SERVICES

ICGC Institut Cartogràfic i Geològic de Catalunya

meteo.cat Servei Meteorològic de Catalunya

# Boletín de peligro de aludes Prepirineu
# Del 19/02/2026 al 20/02/2026

(Válido fuera pistas de esquí y zonas no controladas)

LIMITADO (2), por encima del límite de bosque. DÉBIL (1), por debajo.

**Situación primaria**

**Nieve venteada**

**Distribución**

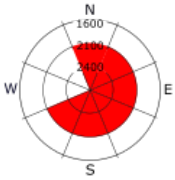


**Tamaño**

**Origen**

**Tendencia**

**Estado del manto nivoso**

Durante el jueves y el viernes por la mañana se formarán nuevas placas por el viento fuerte del NW y N y el episodio de precipitaciones poco abundantes, más frecuentes en las vertientes del Cadí-Moixeró. Estas placas se formarán en orientaciones E y S preferentemente, por encima del límite del bosque, bajo collados y cordales así como en pequeñas cuencas y canales resguardados.

Estas placas serán poco gruesas en general, pero sensibles, y su rotura se podrá producir fácilmente con sobrecargas débiles y desencadenar aludes de pequeño tamaño en general, o de tamaño medio en lugares donde se haya acumulado más la nieve venteada o las placas nuevas se hayan formado sobre placas viejas.

Se recomienda prudencia al circular por la montaña por la presencia de ventisca.

**Distribución del manto nivoso**

Hay nieve desde 1400-1500 m. El manto es esquiable a partir de 1600 m. Los grosores están alrededor de 110-130 cm a unos 2.200 m y son superiores a los habituales.

**Tendencia para las próximas 48-72h**

Las placas tenderán a estabilizarse progresivamente pero aparecerán problemas de nieve húmeda. Peligro: en leve DESCENSO.

**El próximo boletín será emitido el día 2026-02-20**

| | | | | |
|---|---|---|---|---|
| 5 MUY FUERTE | 4 FUERTE | 3 NOTABLE | 2 LIMITADO | 1 DÉBIL |

EAWS EUROPEAN AVALANCHE WARNING SERVICES

ICGC Institut Cartogràfic i Geològic de Catalunya

Servei Meteorològic de Catalunya meteo.cat

# Boletín de peligro de aludes Ter-Freser
# Del 19/02/2026 al 20/02/2026

(Válido fuera pistas de esquí y zonas no controladas)

LIMITADO (2), sobre todo en el extremo N por encima del límite de bosque. DÉBIL (1), en el resto.

**Situación primaria**

**Nieve venteada**

**Distribución**

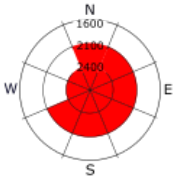


**Tamaño**

**Origen**

**Tendencia**

**Estado del manto nivoso**

Durante el jueves y el viernes por la mañana se formarán nuevas placas de viento por el viento fuerte del NW y N y el episodio de precipitaciones poco abundantes, en orientaciones E y S preferentemente, por encima del límite del bosque, bajo collados y cordales así como en cuencas y laderas resguardadas. Afectará sobre todo al extremo N del sector.

Estas placas de nueva formación tendrán poco grosor en general, pero serán sensibles y podrán ser desencadenadas muy fácilmente de forma accidental. Se pueden esperar aludes de tamaño 1, pequeño, en general, o hasta tamaño medio, donde las sobreacumulaciones locales de nieve venteada sean mayores o impliquen manto antiguo.

Se recomienda prudencia al circular por la montaña por la presencia de ventisca.

**Distribución del manto nivoso**

El manto nivoso presenta grosores muy excedentarios para la época del año. En lugares no afectados por el viento, los espesores oscilan entre 100-140 cm a unos 2.000 m, siendo esquiable a partir de unos 1.500 m.

**Tendencia para las próximas 48-72h**

Las placas tenderán a estabilizarse progresivamente y podrán aparecer nuevos problemas de nieve húmeda. Peligro: en leve DESCENSO.

**El próximo boletín será emitido el día 2026-02-20**

| | | | | |
|---|---|---|---|---|
| 5 MUY FUERTE | 4 FUERTE | 3 NOTABLE | 2 LIMITADO | 1 DÉBIL |

EAWS EUROPEAN AVALANCHE WARNING SERVICES