BUTLLETÍ DEL PERILL D'ALLAUS DEL PRINCIPAT D'ANDORRA

Elaborado el 19/02/2026 16:00
Proxima actualización 20/02/2026 a las 16h

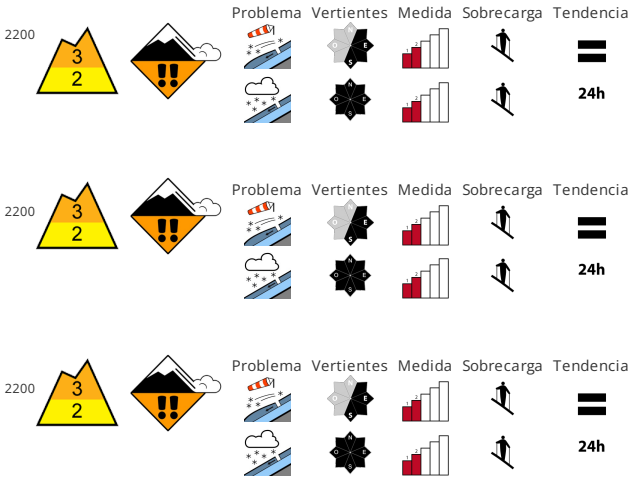

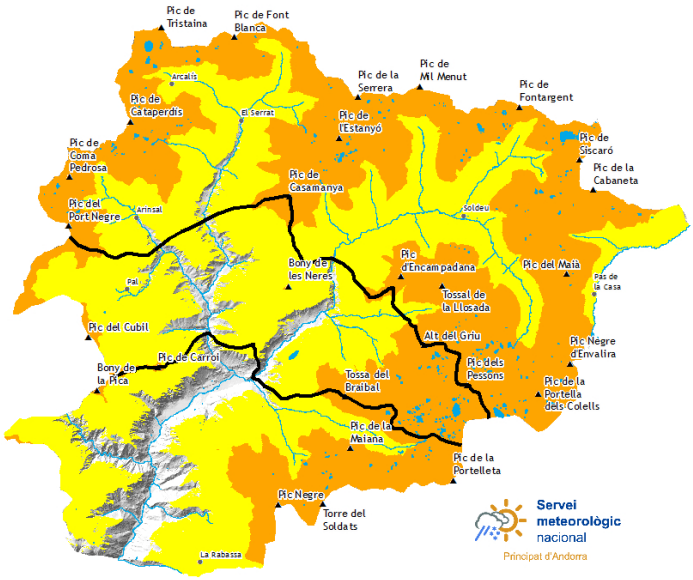

CALIDAD DE LA NIEVE

La nieve reciente y en particular las placas de viento a veces gruesas pueden fácilmente desencadenarse de manera accidental o, de manera aislada, natural en orientaciones nordeste a sur por el este por encima de los 2200 m aproximadamente. Estas se volverán cada vez más inestables. Son especialmente peligrosas las laderas expuestas a nordeste, este y sudeste , donde hay capas débiles persistentes en el manto de nieve antigua. Además se debe tener cuidado con las placas de viento tapadas con nieve reciente. Con la subida de la temperatura diurna y la radiación solar, son probables solo de manera aislada purgas de nieve húmeda de tamaño pequeño. Esto se da especialmente en la base de las paredes rocosas , y en terreno pendiente y escarpado.

ESTABILIDAD DEL MANTO NIVOSO

En las últimas horas se han acumulado 10 cm de nieve por encima de los 2000 m aproximadamente, localmente más. Los espesores de nieve varían mucho por encima de los 2500 m aproximadamente por la influencia del viento. Acumulaciones de nieve venteada más recientes descansan encima de una costra.

ESPESORES DEL MANTO NIVOSO FUERA DE PISTA

Zona norte		Espesor nieve		
Manto Nival		1500m	2000m	2500m
N	1300 m	30 cm	150 cm	200 cm
S	1500 m	0 cm	100 cm	150 cm

zona centro		Espesor nieve		
Manto Nival		1500m	2000m	2500m
N	1300 m	20 cm	150 cm	200 cm
S	1500 m	0 cm	100 cm	150 cm

Zona sur		Espesor nieve		
Manto Nival		1500m	2000m	2500m
N	1300 m	20 cm	120 cm	150 cm
S	1500 m	0 cm	60 cm	100 cm

Govern d'Andorra

Aquest butlletí ha estat elaborat seguint les normes i recomanacions de l'**European Avalanche Warning Services**, del qual el **Servei meteorològic Nacional** n'és membre

BUTLLETÍ DEL PERILL D'ALLAUS DEL PRINCIPAT D'ANDORRA

Servei meteorològic nacional
Principat d'Andorra

Información detallada por espacios naturales protegidos

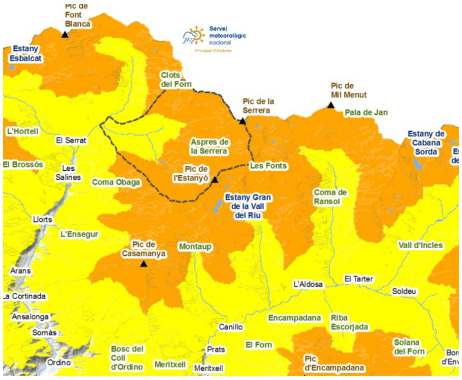

SORTENY

La nevada de este jueves ha añadido algunos centímetros a cotas bajas por encima de la corteza de rehielo. En cotas altas se ha acumulado más nieve, lo que hará más agradables las excursiones, sobre todo por debajo del límite del bosque. En altura la nieve estará más ventolera. Encontramos nieve en todos los caminos desde Llorts y el acceso en esquís hasta el Refugio se puede hacer como hacía años que no se veía durante tantas semanas seguidas. Deberemos seguir las recomendaciones de la estabilidad del manto nivoso para evitar ponernos en peligro en las vertientes este. De cara al fin de semana, con el aumento de temperaturas aparecerán problemas de nieve húmeda en las vertientes sur.

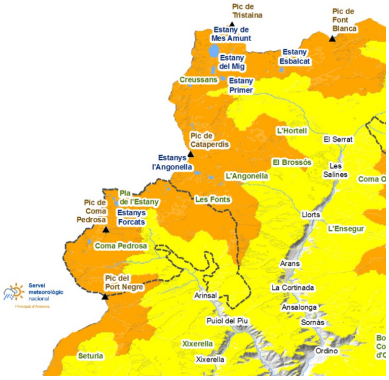

COMAPEDROSA

En cotas bajas la nieve se ha compactado y ha reducido su grosor debido a la humidificación provocada por las últimas lluvias. Pero por encima de esta costra hay algo de nieve nueva. Dentro del bosque será menos abundante y deberemos vigilar a no resbalar, pero en los claros y en las partes altas aislará el hielo. En las vertientes orientadas a este, como puede ser el acceso desde Arinsal por el Port Negre (Sanfons) deberemos extremar las precauciones o evitarlos para no desencadenar las placas de viento formadas estos últimos días. Ya el viernes pueden bajar algunas purgas o pequeños aludes de nieve húmeda en las vertientes sur más escarpadas, problema que irá a más durante el fin de semana.

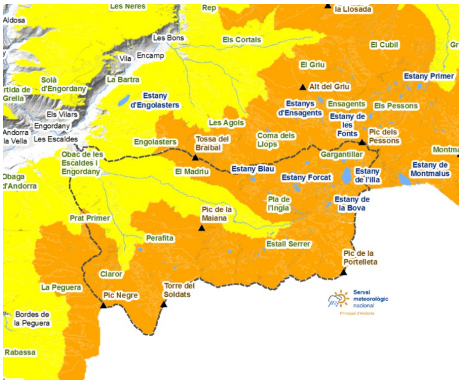

MADRIU-PERAFITA-CLAROR

En las vertientes este se debe circular con mucha cautela, ya que es donde están las acumulaciones de nieve venteada más importantes y peligrosas. En cotas altas el viento habrá dejado la nieve dura al descubierto y con condiciones difíciles de bajar en algunas ocasiones.

Govern d'Andorra

EAWS EUROPEAN AVALANCHE WARNING SERVICES

Aquest butlletí ha estat elaborat seguint les normes i recomanacions de l'**European Avalanche Warning Services**, del qual el **Servei meteorològic Nacional** n'és membre

BUTLLETÍ DEL PERILL D'ALLAUS DEL PRINCIPAT D'ANDORRA

Servei meteorològic nacional
Principat d'Andorra

Espesores de nieve nueva de los últimos días (de las ultimas 24h mesurado a las 06:00h UTC)

	15/02/2026	16/02/2026	17/02/2026	18/02/2026
FEDA (Central)	0 cm	0 cm	0 cm	0 cm
Engolasters - FEDA	0 cm	0 cm	0 cm	0 cm
Bony de les Neres	0 cm	0 cm	0 cm	0 cm
Sorteny	2 cm	6 cm	0 cm	3 cm
Perafita	0 cm	0 cm	0 cm	0 cm
Tossa Espiolets	0 cm	0 cm	0 cm	1 cm
Grau Roig - FEDA	0 cm	0 cm	0 cm	3 cm
Fontverd	0 cm	0 cm	0 cm	3 cm
Ransol - FEDA	0 cm	0 cm	2 cm	0 cm
Setúria	0 cm	0 cm	0 cm	2 cm
Caborreu	4 cm	6 cm	0 cm	0 cm
La Solana	0 cm	0 cm	0 cm	6 cm
Envalira Antenes	0 cm	0 cm	3 cm	2 cm