BUTLLETÍ DEL PERILL D'ALLAUS DEL PRINCIPAT D'ANDORRA

Préparé le 19/02/2026 16:00
Prochaine mise à jour le 20/02/2026 à 16h

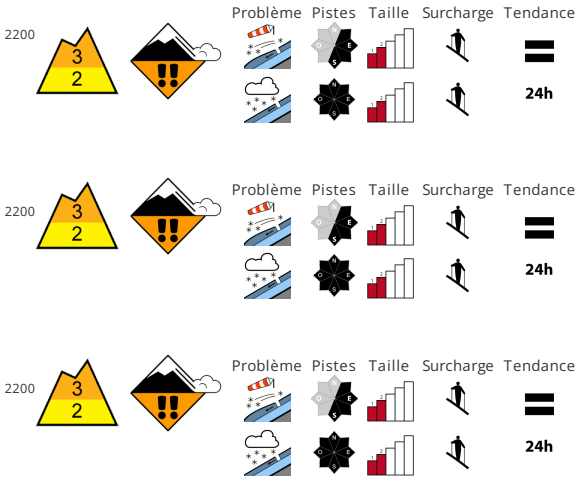

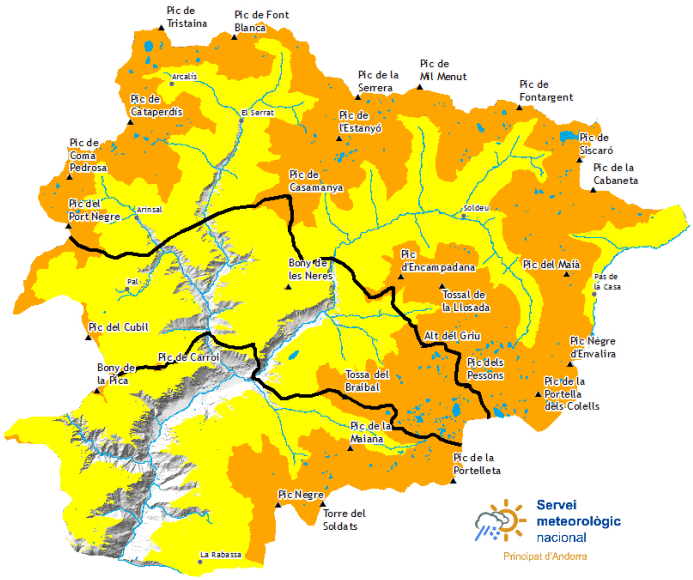

STABILITÉ DU MANTEAU NEIGEUX

La neige fraîche et en particulier les accumulations de neige soufflée parfois épaisses peuvent être déclenchées facilement ou glisser spontanément de manière isolée au sur les pentes exposées au nord-est à sud en passant par l'est au-dessus d'environ 2200 m. Elles deviennent de plus en plus fragiles. Ce sont les pentes exposées au nord-est , à l'est et au sud-est où des endroits fragiles sont présents dans la neige ancienne qui sont particulièrement dangereuses. En outre les accumulations de neige soufflée recouvertes de neige fraîche doivent être prises en considération. Des coulées humides seulement encore isolées de petite taille sont ils sont à attendre avec le réchauffement diurne et le rayonnement solaire. Ceci surtout au pied des parois rocheuses comme en terrain raide rocheux.

QUALITÈ DE LA NEIGE

Au cours des dernières heures il est tombé au-dessus d'environ 2000 m 10 cm de neige , localement plus.. On trouve suivant l'influence du vent des hauteurs de neiges très différentes au-dessus d'environ 2500 m. Des accumulations plus récentes de neige soufflée reposent sur une surface croûtée.

EPAISSEUR DE NEIGE HORS PISTE

Zone nord		Epaisseur de neige		
Nival manteau		1500m	2000m	2500m
N	1300 m	30 cm	150 cm	200 cm
S	1500 m	0 cm	100 cm	150 cm

Zone centre		Epaisseur de neige		
Nival manteau		1500m	2000m	2500m
N	1300 m	20 cm	150 cm	200 cm
S	1500 m	0 cm	100 cm	150 cm

Zone sud		Epaisseur de neige		
Nival manteau		1500m	2000m	2500m
N	1300 m	20 cm	120 cm	150 cm
S	1500 m	0 cm	60 cm	100 cm

Govern d'Andorra

EAWS EUROPEAN AVALANCHE WARNING SERVICES

Aquest butlletí ha estat elaborat seguint les normes i recomanacions de l'**European Avalanche Warning Services**, del qual el **Servei meteorològic Nacional** n'és membre

BUTLLETÍ DEL PERILL D'ALLAUS DEL PRINCIPAT D'ANDORRA

Servei meteorològic nacional
Principat d'Andorra

Des informations détaillées par espace naturel protégé

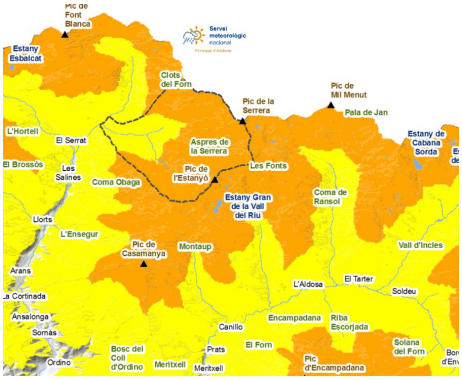

SORTENY

Les chutes de neige de jeudi ont ajouté quelques centimètres aux basses altitudes au-dessus de la croûte de glace. Plus de neige s'est accumulée en haute altitude, ce qui rendra les randonnées plus agréables, surtout en dessous de la limite forestière. En altitude la neige sera plus venteuse. Nous trouvons de la neige sur toutes les routes depuis Llorts et l'accès à skis au Refuge peut se faire car on ne l'a pas vu depuis tant de semaines d'affilée depuis des années. Il faudra suivre les recommandations de stabilité du manteau neigeux pour éviter de se mettre en danger sur les versants Est. Vers le week-end, avec l'augmentation des températures, des problèmes de neige mouillée apparaîtront sur le versant sud. , , , , , , , , , , , ,

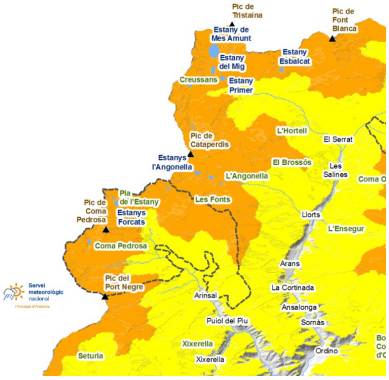

COMAPEDROSA

À basse altitude, la neige s'est compactée et a réduit son épaisseur en raison de l'humidification provoquée par les récentes pluies. Au-dessus de cette croûte, il y a cependant un peu de neige fraîche. A l'intérieur de la forêt, ce sera moins abondant et il faudra faire attention à ne pas glisser, mais dans les clairières et dans les parties supérieures la glace s'isolera. Sur les versants orientés Est, comme l'accès depuis Arinsal par Port Negre (Sanfons), il faudra prendre d'extrêmes précautions ou les éviter afin de ne pas déclencher les plaques de vent formées ces derniers jours. Dès vendredi, quelques averses de neige ou petites avalanches de neige mouillée pourraient tomber sur les pentes sud les plus raides, un problème qui s'accentuera au cours du week-end. , , , , , , , , , ,

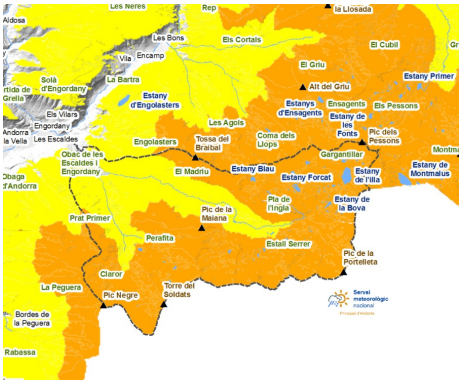

MADRIU-PERAFITA-CLAROR

Les pentes orientales doivent être parcourues avec beaucoup de prudence, car c'est là que se trouvent les accumulations de neige soufflée les plus importantes et les plus dangereuses. À haute altitude, le vent aura laissé la neige dure exposée et avec des conditions difficiles à descendre à certaines occasions. , , ,

Govern d'Andorra

EAWS
EUROPEAN AVALANCHE WARNING SERVICES

Aquest butlletí ha estat elaborat seguint les normes i recomanacions de l'**European Avalanche Warning Services**, del qual el **Servei meteorològic Nacional** n'és membre

BUTLLETÍ DEL PERILL D'ALLAUS DEL PRINCIPAT D'ANDORRA

Servei meteorològic nacional
Principat d'Andorra

Couche de neige fraiche des derniers jours (De 24 h mesurée à 06:00 h UTC)

	15/02/2026	16/02/2026	17/02/2026	18/02/2026
FEDA (Central)	0 cm	0 cm	0 cm	0 cm
Engolasters - FEDA	0 cm	0 cm	0 cm	0 cm
Bony de les Neres	0 cm	0 cm	0 cm	0 cm
Sorteny	2 cm	6 cm	0 cm	3 cm
Perafita	0 cm	0 cm	0 cm	0 cm
Tossa Espiolets	0 cm	0 cm	0 cm	1 cm
Grau Roig - FEDA	0 cm	0 cm	0 cm	3 cm
Fontverd	0 cm	0 cm	0 cm	3 cm
Ransol - FEDA	0 cm	0 cm	2 cm	0 cm
Setúria	0 cm	0 cm	0 cm	2 cm
Caborreu	4 cm	6 cm	0 cm	0 cm
La Solana	0 cm	0 cm	0 cm	6 cm
Envalira Antenes	0 cm	0 cm	3 cm	2 cm