MINISTERO DELLA DIFESA

meteomont
Servizio Nazionale di previsione neve e valanghe

EAWS EUROPEAN AVALANCHE WARNING SERVICES

CARABINIERI

AERONAUTICA MILITARE SERVIZIO METEOROLOGICO

ALPI GIULIE

Bollettino Valanghe N. 351/2026 del 19/02/2026 ore 14.00
Validità 48 ore prossima emissione 20/02/2026

A cura del Servizio METEOMONT dell'ARMA dei CARABINIERI
In collaborazione con Servizio Meteorologico dell'Aeronautica militare

SITUAZIONE alle 14:00 del 19/02/2026

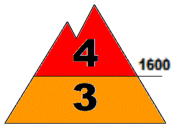

SITUAZIONE TIPO: neve a debole coesione e vento.



SITUAZIONE TIPO: neve a debole coesione e vento.

Quota neve (mslm)	Nord	Sud
	700	700

Altezza Neve (cm)	Neve al suolo	Neve Fresca	Quota (mslm)
	125	005	1750
	46	003	872

VALANGHE OSSERVATE: -.

PREVISIONI 20/02/2026

GRADO DI PERICOLO: FORTE 4

SITUAZIONE TIPO: neve a debole coesione e vento.



SITUAZIONE TIPO: neve a debole coesione e vento.

MANTO NEVOSO: La stabilità del manto nevoso è scarsa su molti punti (aree) per tutte le esposizioni al di sopra di 1600 mslm, possibili valanghe di dimensioni grandi.
La stabilità del manto nevoso è scarsa su alcuni punti (aree) per tutte le esposizioni al di sotto di 1600 mslm, possibili valanghe di dimensioni grandi.

AVVERTENZE

In considerazione dei recenti apporti di neve fresca, è richiesta un'ottima valutazione locale della stabilità ed individuazione dell'itinerario.

SCALA EUROPEA DEL GRADO DI PERICOLO VALANGHE

LEGENDA PROBLEMA

Bollettino realizzato su scala sinottica-regionale (standard EAWS). La sua valutazione non può escludere in alcun modo la necessità di una seria e capace valutazione locale del pericolo (singolo pendio) che può essere anche sensibilmente diverso. Le previsioni meteorologiche sono relative all'orario UTC (per l'Italia +1 in inverno e +2 in estate).

MINISTERO DELLA DIFESA

meteomont
Servizio Nazionale di previsione neve e valanghe

EAWS EUROPEAN AVALANCHE WARNING SERVICES

CARABINIERI

ALPI GIULIE

PREVISIONE METEO

Quota		20/02/2026 h6:00	20/02/2026 h12:00	20/02/2026 h18:00
1000	Venti	04 Nodi da N-Est	06 Nodi da N-Est	02 Nodi da Nord
	Temperature	-03 °C	-02 °C	-03 °C
	Temp.percepita	-6 °C	-6 °C	-3 °C
2000	Venti	17 Nodi da Nord	23 Nodi da Nord	15 Nodi da Nord
	Temperature	-07 °C	-05 °C	-05 °C
	Temp.percepita	-16 °C	-14 °C	-13 °C
3000	Venti	19 Nodi da N-Est	24 Nodi da N-Est	17 Nodi da N-Est
	Temperature	-11 °C	-10 °C	-09 °C
	Temp.percepita	-22 °C	-21 °C	-18 °C
Zero termico		0900-1100 m.	1100-1300 m.	0700-0900 m.
Fenomeno			—	—
Stato del cielo				

LEGENDA FENOMENI

— Assenza Fenomeni · Nebbia · Foschia · Pioggia debole · Pioggia moderata · Pioggia forte · Temporali

Nevicata debole · Nevicata moderata · Nevicata forte

STATO DEL CIELO

Sereno · Poco nuvoloso · Nuvoloso · Molto nuvoloso · Coperto

Parametri meteonivometrici registrati presso i campi di rilevamento il 19/02/2026.

Località	Comune	Quota (m.s.l.m.)	Altezza neve (cm)	Neve caduta nelle 24 ore (cm)	Temp. Min (°C)	Temp. Max (°C)	Condizioni del tempo
MALBORGHETTO - VAL SAISERA	Tarvisio (UD)	875	46	3	-6	+10	Nevicata moderata
PASSO PRAMOLLO	Pontebba (UD)	1530	123	7	-10	+4	Nevicata forte
MONTE LUSSARI	Tarvisio (UD)	1750	125	10	-5	+7	Nevicata forte
PASSO PREDIL	Tarvisio (UD)	1130	77	6	-3	+2	Nevicata moderata

(*) Rilievi fuori campo

L'INFORMAZIONE E' PREVENZIONE - LEGGI L'ATTUALE GRADO DI PERICOLO VALANGHE!

IL CAPO DEL CENTRO NAZIONALE METEOMONT
(Ten. Col. RFI Emanuela Gini)
FIRMA AUTOGRAFA OMESSA AI SENSI
DELL'ART.3 DEL D.LGS N.39/1993