MINISTERO DELLA DIFESA

meteomont Servizio Nazionale di previsione neve e valanghe

EAWS EUROPEAN AVALANCHE WARNING SERVICES

CARABINIERI

## ALPI OROBICHE

Bollettino Valanghe N. 349/2026 del 18/02/2026 ore 14.00
Validità 48 ore prossima emissione 19/02/2026

**A cura del Servizio METEOMONT dell'ARMA dei CARABINIERI**
**In collaborazione con Servizio Meteorologico dell'Aeronautica militare**

## SITUAZIONE alle 14:00 del 18/02/2026

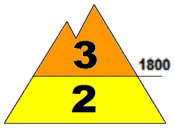


**SITUAZIONE TIPO: strato debole persistente basale.**




**SITUAZIONE TIPO: passaggio da poca a molta neve.**

| Quota neve (mslm) | Nord | Sud |
|---|---|---|
| | 1200 - 1300 | 1300 - 1400 |

| Altezza Neve (cm) | Neve al suolo | Neve Fresca | Quota (mslm) |
|---|---|---|---|
| | 120 | 0 | 2050 |
| | 064 | 0 | 1635 |

**VALANGHE OSSERVATE: Nessuna valanga.**

## PREVISIONI 19/02/2026

# GRADO DI PERICOLO: FORTE 4

## SITUAZIONE TIPO: neve a debole coesione e vento.

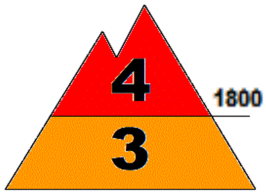


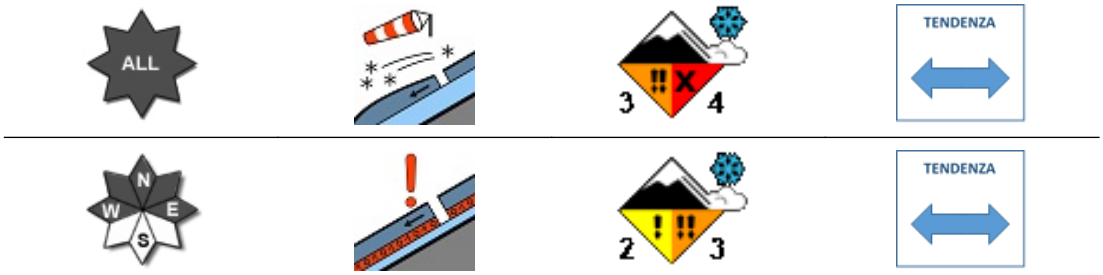


## SITUAZIONE TIPO: strato debole persistente basale.

**MANTO NEVOSO: La stabilità del manto nevoso è molto scarsa su molti punti (aree) per tutte le esposizioni al di sopra di 1800 mslm, possibili valanghe di dimensioni grandi.**
**La stabilità del manto nevoso è scarsa su molti punti (aree) per versanti da ovest a est al di sotto di 1800 mslm, possibili valanghe di dimensioni medie.**

## AVVERTENZE

In considerazione delle avverse condizioni meteorologiche previste , le attività al di fuori delle piste battute e segnalate sono sconsigliate.

## SCALA EUROPEA DEL GRADO DI PERICOLO VALANGHE

5 - MOLTO FORTE | 4 - FORTE | 3 - MARCATO | 2 - MODERATO | 1 - DEBOLE | NO NEVE | NO INFO

## LEGENDA PROBLEMA

NEVE FRESCA | LASTRONI DA VENTO | STRATI DEBOLI PERSISTENTI | NEVE BAGNATA | SLITTAMENTO | CORNICI | NESSUN PROBLEMA VALANGHIVO EVIDENTE | NO_INFO

**Bollettino realizzato su scala sinottica-regionale (standard EAWS). La sua valutazione non può escludere in alcun modo la necessità di una seria e capace valutazione locale del pericolo (singolo pendio) che può essere anche sensibilmente diverso. Le previsioni meteorologiche sono relative all'orario UTC (per l'Italia +1 in inverno e +2 in estate).**

MINISTERO DELLA DIFESA

meteomont
Servizio Nazionale di previsione neve e valanghe

EAWS EUROPEAN AVALANCHE WARNING SERVICES

CARABINIERI

# ALPI OROBICHE

## PREVISIONE METEO

| Quota | | 19/02/2026 h6:00 | 19/02/2026 h12:00 | 19/02/2026 h18:00 |
|---|---|---|---|---|
| 1000 | Venti | 02 Nodi da S-Est | 01 nodi da N-Ovest | 04 Nodi da Nord |
| | Temperature | -03 °C | -01 °C | -01 °C |
| | Temp.percepita | -3 °C | -1 °C | -4 °C |
| 2000 | Venti | 04 Nodi da S-Est | 03 nodi da N-Ovest | 08 Nodi da Nord |
| | Temperature | -03 °C | -03 °C | -02 °C |
| | Temp.percepita | -6 °C | -5 °C | -7 °C |
| 3000 | Venti | 20 Nodi da Sud | 05 Nodi da Nord | 16 Nodi da Nord |
| | Temperature | -08 °C | -09 °C | -09 °C |
| | Temp.percepita | -18 °C | -14 °C | -18 °C |
| Zero termico | | 1300-1500 m. | 1600-1800 m. | 1400-1600 m. |
| Fenomeno | | | | — |
| Stato del cielo | | | | |

## LEGENDA FENOMENI

— Assenza Fenomeni · Nebbia · Foschia · Pioggia debole · Pioggia moderata · Pioggia forte · Temporali

Nevicata debole · Nevicata moderata · Nevicata forte

## STATO DEL CIELO

Sereno · Poco nuvoloso · Nuvoloso · Molto nuvoloso · Coperto

## Parametri meteonivometrici registrati presso i campi di rilevamento il 18/02/2026.

| Località | Comune | Quota (m.s.l.m.) | Altezza neve (cm) | Neve caduta nelle 24 ore (cm) | Temp. Min (°C) | Temp. Max (°C) | Condizioni del tempo |
|---|---|---|---|---|---|---|---|
| CIMA VALZELLI | Castione della Presolana (BG) | 1622 | 56 | 0 | N.P. | N.P. | Assenza di precipitazioni |
| VODALA | Gromo (BG) | 1635 | 64 | 0 | -4 | +2 | Assenza di precipitazioni |
| QUARTA BAITA | Foppolo (BG) | 1760 | 61 | 0 | -4 | +5 | Assenza di precipitazioni |
| PASSO DELLA PRESOLANA * | Colere (BG) | 1351 | 10 | 0 | N.P. | N.P. | Assenza di precipitazioni |

(*) Rilievi fuori campo

**L'INFORMAZIONE E' PREVENZIONE - LEGGI L'ATTUALE GRADO DI PERICOLO VALANGHE!**

**IL CAPO DEL CENTRO NAZIONALE METEOMONT**
**(Ten. Col. RFI Emanuela Gini)**
**FIRMA AUTOGRAFA OMESSA AI SENSI**
**DELL'ART.3 DEL D.LGS N.39/1993**

Bollettino realizzato su scala sinottica-regionale (standard EAWS). La sua valutazione non può escludere in alcun modo la necessità di una seria e capace valutazione locale del pericolo (singolo pendio) che può essere anche sensibilmente diverso. Le previsioni meteorologiche sono relative all'orario UTC (per l'Italia +1 in inverno e +2 in estate).