MINISTERO DELLA DIFESA

meteomont Servizio Nazionale di previsione neve e valanghe

EAWS EUROPEAN AVALANCHE WARNING SERVICES

CARABINIERI

In collaborazione con: MARCHE

APPENNINO UMBRO-MARCHIG. MERID. - MONTI SIBILLINI

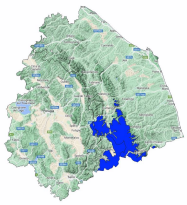

Bollettino Valanghe N. 304/2026 del 19/02/2026 ore 14.00
Validità 48 ore prossima emissione 20/02/2026

A cura del Servizio METEOMONT dell'ARMA dei CARABINIERI
In collaborazione con Servizio Meteorologico dell'Aeronautica militare

SITUAZIONE alle 14:00 del 19/02/2026

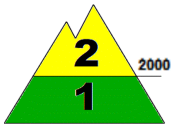

SITUAZIONE TIPO: neve a debole coesione e vento.



SITUAZIONE TIPO: pioggia su neve.

Quota neve (mslm)	Nord	Sud
	1500	1600 - 1700

Altezza Neve (cm)	Neve al suolo	Neve Fresca	Quota (mslm)
	110-160	000	2000
	30 - 50	000	1700

VALANGHE OSSERVATE: Nessuna valanga.

PREVISIONI 20/02/2026

GRADO DI PERICOLO: MODERATO 2

SITUAZIONE TIPO: neve a debole coesione e vento.

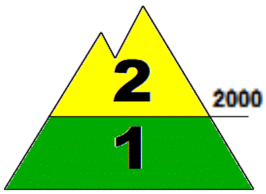

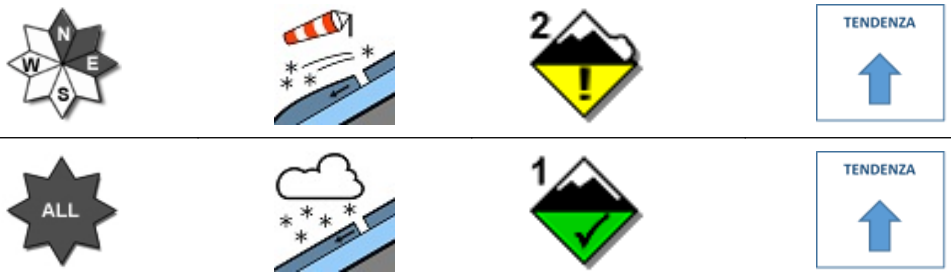

SITUAZIONE TIPO: neve a debole coesione e vento.

MANTO NEVOSO: La stabilità del manto nevoso è scarsa su alcuni punti (aree) per versanti nord orientali al di sopra di 2000 mslm, possibili valanghe di dimensioni medie.
La stabilità del manto nevoso è buona su alcuni punti (aree) per tutte le esposizioni al di sotto di 2000 mslm, possibili valanghe di dimensioni medie.

AVVERTENZE

In considerazione dei recenti apporti di neve fresca, è richiesta un'ottima valutazione locale della stabilità ed individuazione dell'itinerario.

SCALA EUROPEA DEL GRADO DI PERICOLO VALANGHE

LEGENDA PROBLEMA

Bollettino realizzato su scala sinottica-regionale (standard EAWS). La sua valutazione non può escludere in alcun modo la necessità di una seria e capace valutazione locale del pericolo (singolo pendio) che può essere anche sensibilmente diverso. Le previsioni meteorologiche sono relative all'orario UTC (per l'Italia +1 in inverno e +2 in estate).

MINISTERO DELLA DIFESA

meteomont Servizio Nazionale di previsione neve e valanghe

EAWS EUROPEAN AVALANCHE WARNING SERVICES

CARABINIERI

In collaborazione con: MARCHE

APPENNINO UMBRO-MARCHIG. MERID. - MONTI SIBILLINI

PREVISIONE METEO

Quota		20/02/2026 h6:00	20/02/2026 h12:00	20/02/2026 h18:00
1000	Venti	04 Nodi da Ovest	03 nodi da N-Ovest	07 Nodi da Nord
	Temperature	+00 °C	+01 °C	-03 °C
	Temp.percepita	-3 °C	-1 °C	-8 °C
2000	Venti	10 nodi da Ovest	06 nodi da N-Ovest	23 Nodi da Nord
	Temperature	-03 °C	-04 °C	-07 °C
	Temp.percepita	-9 °C	-8 °C	-17 °C
3000	Venti	17 nodi da N-Ovest	08 nodi da N-Ovest	25 Nodi da Nord
	Temperature	-09 °C	-09 °C	-08 °C
	Temp.percepita	-18 °C	-15 °C	-19 °C
Zero termico		1500-1700 m.	1500-1700 m.	0900-1100 m.
Fenomeno		—		
Stato del cielo				

LEGENDA FENOMENI

Assenza Fenomeni — Nebbia — Foschia — Pioggia debole — Pioggia moderata — Pioggia forte — Temporali

Nevicata debole — Nevicata moderata — Nevicata forte

STATO DEL CIELO

Sereno — Poco nuvoloso — Nuvoloso — Molto nuvoloso — Coperto

Parametri meteonivometrici registrati presso i campi di rilevamento il 19/02/2026.

Località	Comune	Quota (m.s.l.m.)	Altezza neve (cm)	Neve caduta nelle 24 ore (cm)	Temp. Min (°C)	Temp. Max (°C)	Condizioni del tempo
FORCA DI GUALDO	Castelsantangelo sul Nera (MC)	1496	48	0	-1	+4	Assenza di precipitazioni
LA VALLETTA	Bolognola (MC)	1352	0	0	+2	+7	Assenza di precipitazioni
COLLE	Montegallo (AP)	1036	0	0	+2	+9	Assenza di precipitazioni
PARCO GUARNIERI	Montemonaco (AP)	980	0	0	+3	+11	Assenza di precipitazioni
RIFUGIO PERUGIA	Norcia (PG)	1500	0	0	N.P.	N.P.	Assenza di precipitazioni
FRONTIGNANO *	Ussita (MC)	1696	40	0	N.P.	N.P.	Assenza di precipitazioni

(*) Rilievi fuori campo

L'INFORMAZIONE E' PREVENZIONE - LEGGI L'ATTUALE GRADO DI PERICOLO VALANGHE!

IL CAPO DEL CENTRO NAZIONALE METEOMONT
(Ten. Col. RFI Emanuela Gini)
FIRMA AUTOGRAFA OMESSA AI SENSI
DELL'ART.3 DEL D.LGS N.39/1993

Bollettino realizzato su scala sinottica-regionale (standard EAWS). La sua valutazione non può escludere in alcun modo la necessità di una seria e capace valutazione locale del pericolo (singolo pendio) che può essere anche sensibilmente diverso. Le previsioni meteorologiche sono relative all'orario UTC (per l'Italia +1 in inverno e +2 in estate).