MINISTERO DELLA DIFESA

meteomont
Servizio Nazionale di previsione neve e valanghe

EAWS EUROPEAN AVALANCHE WARNING SERVICES

CARABINIERI

AERONAUTICA MILITARE SERVIZIO METEOROLOGICO

P.N. ABRUZZO

Bollettino Valanghe N. 305/2026 del 18/02/2026 ore 14.00
Validità 48 ore prossima emissione 19/02/2026

A cura del Servizio METEOMONT dell'ARMA dei CARABINIERI
In collaborazione con Servizio Meteorologico dell'Aeronautica militare

SITUAZIONE alle 14:00 del 18/02/2026

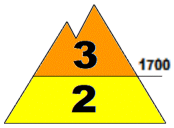

SITUAZIONE TIPO: neve a debole coesione e vento.



SITUAZIONE TIPO: situazione primaverile.

	Nord	Sud
Quota neve (mslm)	*1400 - 1600*	*1500 - 1700*

	Neve al suolo	Neve Fresca	Quota (mslm)
Altezza Neve (cm)	*040*	*002*	*1480*
	019	*000*	*1470*

VALANGHE OSSERVATE: Nessuna valanga.

PREVISIONI 19/02/2026

GRADO DI PERICOLO: MARCATO 3

SITUAZIONE TIPO: neve a debole coesione e vento.

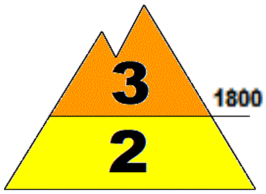

SITUAZIONE TIPO: situazione primaverile.

MANTO NEVOSO: La stabilità del manto nevoso è scarsa su alcuni punti (aree) per versanti sud orientali al di sopra di 1800 mslm, possibili valanghe di dimensioni grandi.
La stabilità del manto nevoso è discreta su alcuni punti (aree) per isolati pendii al di sotto di 1800 mslm, possibili valanghe di dimensioni medie.

AVVERTENZE

In considerazione degli importanti accumuli di neve ventata in conche, canaloni, cambi di pendenza e pendii sotto vento in genere, è richiesta un'ottima valutazione locale della stabilità ed individuazione dell'itinerario.

SCALA EUROPEA DEL GRADO DI PERICOLO VALANGHE

LEGENDA PROBLEMA

Bollettino realizzato su scala sinottica-regionale (standard EAWS). La sua valutazione non può escludere in alcun modo la necessità di una seria e capace valutazione locale del pericolo (singolo pendio) che può essere anche sensibilmente diverso. Le previsioni meteorologiche sono relative all'orario UTC (per l'Italia +1 in inverno e +2 in estate).

P.N. ABRUZZO

PREVISIONE METEO

Quota		19/02/2026 h6:00	19/02/2026 h12:00	19/02/2026 h18:00
1000	Venti	07 Nodi da S-Ovest	09 Nodi da S-Ovest	06 Nodi da Ovest
	Temperature	+04 °C	+04 °C	+00 °C
	Temp.percepita	1 °C	0 °C	-4 °C
2000	Venti	21 Nodi da S-Ovest	23 Nodi da S-Ovest	18 Nodi da Ovest
	Temperature	+01 °C	+01 °C	-04 °C
	Temp.percepita	-6 °C	-6 °C	-12 °C
3000	Venti	23 Nodi da S-Ovest	28 Nodi da S-Ovest	20 Nodi da Ovest
	Temperature	-06 °C	-05 °C	-10 °C
	Temp.percepita	-16 °C	-15 °C	-20 °C
Zero termico		2100-2300 m.	2100-2300 m.	1400-1600 m.
Fenomeno				
Stato del cielo				

LEGENDA FENOMENI

Assenza Fenomeni — Nebbia — Foschia — Pioggia debole — Pioggia moderata — Pioggia forte — Temporali

Nevicata debole — Nevicata moderata — Nevicata forte

STATO DEL CIELO

Sereno — Poco nuvoloso — Nuvoloso — Molto nuvoloso — Coperto

Parametri meteonivometrici registrati presso i campi di rilevamento il 18/02/2026.

Località	Comune	Quota (m.s.l.m.)	Altezza neve (cm)	Neve caduta nelle 24 ore (cm)	Temp. Min (°C)	Temp. Max (°C)	Condizioni del tempo
FORCA D'ACERO	Pescasseroli (AQ)	1480	40	2	-3	+8	Assenza di precipitazioni
VALLE GELATA	Pescocostanzo (AQ)	1466	Tracce di neve	Tracce di neve	-3	+5	Assenza di precipitazioni
LA PESCINA	Rivisondoli (AQ)	1470	19	Tracce di neve	-4	+2	Assenza di precipitazioni
MIMOLA	Scanno (AQ)	1495	1	0	-3	+6	Assenza di precipitazioni

(*) Rilievi fuori campo

L'INFORMAZIONE E' PREVENZIONE - LEGGI L'ATTUALE GRADO DI PERICOLO VALANGHE!

IL CAPO DEL CENTRO NAZIONALE METEOMONT
(Ten. Col. RFI Emanuela Gini)
FIRMA AUTOGRAFA OMESSA AI SENSI
DELL'ART.3 DEL D.LGS N.39/1993