MINISTERO DELLA DIFESA

meteomont
Servizio Nazionale di previsione neve e valanghe

EAWS EUROPEAN AVALANCHE WARNING SERVICES

CARABINIERI

APPENNINO LUCANO

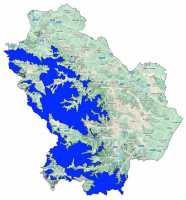

Bollettino Valanghe N. 248/2026 del 19/02/2026 ore 14.00
Validità 48 ore prossima emissione 20/02/2026

A cura del Servizio METEOMONT dell'ARMA dei CARABINIERI
In collaborazione con Servizio Meteorologico dell'Aeronautica militare

SITUAZIONE alle 14:00 del 19/02/2026

SITUAZIONE TIPO: pioggia su neve.

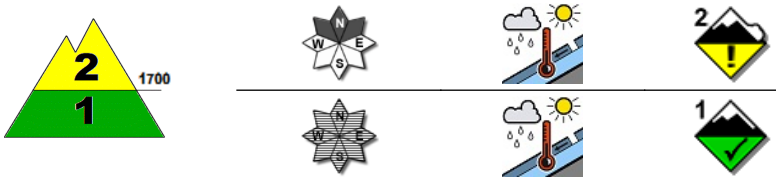

SITUAZIONE TIPO: pioggia su neve.

Quota neve (mslm)	Nord	Sud
	1500	1600

Altezza Neve (cm)	Neve al suolo	Neve Fresca	Quota (mslm)
	005	000	1530
	003	000	1380

VALANGHE OSSERVATE: -.

PREVISIONI 20/02/2026

GRADO DI PERICOLO: MODERATO 2

SITUAZIONE TIPO: pioggia su neve.



SITUAZIONE TIPO: pioggia su neve.

MANTO NEVOSO: La stabilità del manto nevoso è discreta su alcuni punti (aree) per versanti settentrionali al di sopra di 1700 mslm, possibili valanghe di dimensioni medie.
La stabilità del manto nevoso è buona su molti punti (aree) per isolati pendii al di sotto di 1700 mslm, possibili valanghe di dimensioni piccole.

AVVERTENZE

In considerazione delle avverse condizioni meteorologiche in atto, le attività al di fuori delle piste battute e segnalate sono sconsigliate.

SCALA EUROPEA DEL GRADO DI PERICOLO VALANGHE

5 - MOLTO FORTE | 4 - FORTE | 3 - MARCATO | 2 - MODERATO | 1 - DEBOLE | NO NEVE | NO INFO

LEGENDA PROBLEMA

NEVE FRESCA | LASTRONI DA VENTO | STRATI DEBOLI PERSISTENTI | NEVE BAGNATA | SLITTAMENTO | CORNICI | NESSUN PROBLEMA VALANGHIVO EVIDENTE | NO_INFO

Bollettino realizzato su scala sinottica-regionale (standard EAWS). La sua valutazione non può escludere in alcun modo la necessità di una seria e capace valutazione locale del pericolo (singolo pendio) che può essere anche sensibilmente diverso. Le previsioni meteorologiche sono relative all'orario UTC (per l'Italia +1 in inverno e +2 in estate).

APPENNINO LUCANO

PREVISIONE METEO

Quota		20/02/2026 h6:00	20/02/2026 h12:00	20/02/2026 h18:00
1000	Venti	16 Nodi da Ovest	04 Nodi da Ovest	02 Nodi da Nord
	Temperature	+05 °C	+04 °C	+05 °C
	Temp.percepita	0 °C	2 °C	5 °C
2000	Venti	19 Nodi da Ovest	08 Nodi da Ovest	05 Nodi da Nord
	Temperature	-03 °C	-02 °C	-02 °C
	Temp.percepita	-11 °C	-7 °C	-5 °C
3000	Venti	20 Nodi da Ovest	10 Nodi da Ovest	03 nodi da N-Ovest
	Temperature	-08 °C	-08 °C	-08 °C
	Temp.percepita	-18 °C	-15 °C	-11 °C
Zero termico		1200-1400 m.	1400-1600 m.	1400-1600 m.
Fenomeno				—
Stato del cielo				

LEGENDA FENOMENI

— Assenza Fenomeni · Nebbia · Foschia · Pioggia debole · Pioggia moderata · Pioggia forte · Temporali

Nevicata debole · Nevicata moderata · Nevicata forte

STATO DEL CIELO

Sereno · Poco nuvoloso · Nuvoloso · Molto nuvoloso · Coperto

Parametri meteonivometrici registrati presso i campi di rilevamento il 19/02/2026.

Località	Comune	Quota (m.s.l.m.)	Altezza neve (cm)	Neve caduta nelle 24 ore (cm)	Temp. Min (°C)	Temp. Max (°C)	Condizioni del tempo
LAUDEMIO	Lagonegro (PZ)	1532	5	0	0	+5	Nebbia con cielo non visibile
PIANO IMPERATORE	Marsicovetere (PZ)	1560	3	0	+2	+8	Nebbia con cielo non visibile

(*) Rilievi fuori campo

L'INFORMAZIONE E' PREVENZIONE - LEGGI L'ATTUALE GRADO DI PERICOLO VALANGHE!

IL CAPO DEL CENTRO NAZIONALE METEOMONT
(Ten. Col. RFI Emanuela Gini)
FIRMA AUTOGRAFA OMESSA AI SENSI
DELL'ART.3 DEL D.LGS N.39/1993