MINISTERO DELLA DIFESA

meteomont Servizio Nazionale di previsione neve e valanghe

EAWS EUROPEAN AVALANCHE WARNING SERVICES

CARABINIERI

APPENNINO CALABRO

Bollettino Valanghe N. 233/2026 del 18/02/2026 ore 14.00
Validità 48 ore prossima emissione 19/02/2026

A cura del Servizio METEOMONT dell'ARMA dei CARABINIERI
In collaborazione con Servizio Meteorologico dell'Aeronautica militare

SITUAZIONE alle 14:00 del 18/02/2026

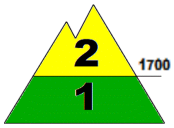

SITUAZIONE TIPO: neve a debole coesione e vento.



SITUAZIONE TIPO: situazione primaverile.

Quota neve (mslm)	Nord	Sud
	1200 - 1500	1300 - 1600

Altezza Neve (cm)	Neve al suolo	Neve Fresca	Quota (mslm)
	018	002	1600
	010	000	1530

VALANGHE OSSERVATE: Nessuna valanga.

PREVISIONI 19/02/2026

GRADO DI PERICOLO: MODERATO 2

SITUAZIONE TIPO: pioggia su neve.



SITUAZIONE TIPO: pioggia su neve.

MANTO NEVOSO: La stabilità del manto nevoso è discreta su alcuni punti (aree) per tutte le esposizioni al di sopra di 1700 mslm, possibili valanghe di dimensioni medie.
La stabilità del manto nevoso è discreta su pochi punti (aree) per tutte le esposizioni al di sotto di 1700 mslm, possibili valanghe di dimensioni piccole.

AVVERTENZE

A seguito dell'attività eolica registrata sono da evitare le zone di accumulo, conche, canaloni, cambi di pendenza e pendii sotto vento in genere.

SCALA EUROPEA DEL GRADO DI PERICOLO VALANGHE

LEGENDA PROBLEMA

Bollettino realizzato su scala sinottica-regionale (standard EAWS). La sua valutazione non può escludere in alcun modo la necessità di una seria e capace valutazione locale del pericolo (singolo pendio) che può essere anche sensibilmente diverso. Le previsioni meteorologiche sono relative all'orario UTC (per l'Italia +1 in inverno e +2 in estate).

APPENNINO CALABRO

PREVISIONE METEO

Quota		19/02/2026 h6:00	19/02/2026 h12:00	19/02/2026 h18:00
1000	Venti	03 Nodi da Ovest	07 Nodi da S-Ovest	11 Nodi da S-Ovest
	Temperature	+02 °C	+06 °C	+04 °C
	Temp.percepita	0 °C	3 °C	-0 °C
2000	Venti	09 Nodi da Ovest	17 Nodi da S-Ovest	25 Nodi da S-Ovest
	Temperature	+01 °C	+03 °C	+01 °C
	Temp.percepita	-3 °C	-3 °C	-7 °C
3000	Venti	13 Nodi da Ovest	21 Nodi da Ovest	27 Nodi da S-Ovest
	Temperature	-01 °C	-02 °C	-06 °C
	Temp.percepita	-7 °C	-10 °C	-16 °C
Zero termico		2400-2600 m.	2400-2600 m.	2000-2200 m.
Fenomeno		—	—	
Stato del cielo				

LEGENDA FENOMENI

— Assenza Fenomeni · Nebbia · Foschia · Pioggia debole · Pioggia moderata · Pioggia forte · Temporali

Nevicata debole · Nevicata moderata · Nevicata forte

STATO DEL CIELO

Sereno · Poco nuvoloso · Nuvoloso · Molto nuvoloso · Coperto

Parametri meteonivometrici registrati presso i campi di rilevamento il 18/02/2026.

Località	Comune	Quota (m.s.l.m.)	Altezza neve (cm)	Neve caduta nelle 24 ore (cm)	Temp. Min (°C)	Temp. Max (°C)	Condizioni del tempo
BIVIO NARDODIPACE	Mongiana (VV)	1339	2	0	-1	+4	Assenza di precipitazioni
GAMBARIE	Santo Stefano in Aspromonte (RC)	1367	1	Tracce di neve mista a pioggia	-2	+2	Assenza di precipitazioni
COZZO VARDO	Morano Calabro (CS)	1475	3	0	-2	+2	Assenza di precipitazioni
VALICO DI MONTE SCURO	Celico (CS)	1600	18	2	-9	+5	Assenza di precipitazioni
BUTURO	Albi (CZ)	1530	10	0	+0	+5	Assenza di precipitazioni

(*) Rilievi fuori campo

L'INFORMAZIONE E' PREVENZIONE - LEGGI L'ATTUALE GRADO DI PERICOLO VALANGHE!

IL CAPO DEL CENTRO NAZIONALE METEOMONT
(Ten. Col. RFI Emanuela Gini)
FIRMA AUTOGRAFA OMESSA AI SENSI
DELL'ART.3 DEL D.LGS N.39/1993