Bulletin d'estimation du risque d'avalanche

(valable en dehors des pistes balisées et ouvertes)

MASSIF : Renoso Incudine

Rédigé le jeudi 19 février 2026 à 15h

Estimation des risques pour le : VENDREDI 20 FÉVRIER

NOMBREUSES INSTABILITÉS DANS LA NEIGE FRAICHE VENTÉE

3

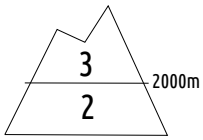

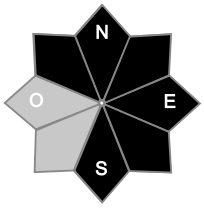

Au-dessus de 2000m indice de risque marqué, plus bas indice limité.

Départs spontanés : Avalanches de neige fraîche de taille moyenne à grande au-dessus de 2000m

Déclenchements provoqués : Nombreuses plaques à vent réactives dans la neige récente.

Indices de risque : 5 très fort - 4 fort - 3 marqué - 2 limité - 1 faible -- En noir : les pentes les plus dangereuses

Stabilité du manteau neigeux

Situation avalancheuse typique : neige ventée

Déclenchements provoqués : En soirée de jeudi et durant la nuit, les chutes de neige ventée génèrent de nouvelles plaques, souvent loin des crêtes. Elles sont plus fréquentes au-dessus de 2000 m. Certaines plaques présentent un aspect poudreux très piégeux et sont facilement déclenchables au passage d'un skieur ou randonneur y compris à distance. Les avalanches de taille 2 à 3 peuvent présenter des cassures importantes, dans les pentes d'un large secteur sud-est à nord, favorables aux accumulations. Dans les autres secteurs, plus exposés au vent, les plaques sont un peu plus minces, plus dures et plus facilement identifiables.
En dessous de 2000 mètres, voire plus haut en versants ensoleillés, on trouve des quantités variables de neige fraîche en surface mais reposant sur un manteau neigeux humidifié, ce qui limite l'ampleur d'un éventuel déclenchement. (taille 1 rarement 2) mais parfois déclenchable par un seul skieur.

Départs spontanés : Les chutes de neige à venir durant la nuit de jeudi à vendredi, entre 20 et 40 cm, augmentent le risque de départs naturels d'avalanches de poudre. Les départs concernent les pentes raides et moins raides. Des décrochements de plaques peuvent se également se produire à cause de la neige transportée par le vent, venant surcharger et déclencher une de ces plaques. De grandes avalanches sont possibles dans les pentes les plus chargées. En journée de vendredi, le risque de départ spontané concerne davantage les versants bien ensoleillés.

Autres : Risque de glissade en neige dure ou glacée aux abords des crêtes et sommets balayés par les vents.

Qualité de la neige

Qualification de l'enneigement : L'enneigement est excellent pour la saison à toutes altitudes. A Ghisoni Capanelle, on relève 1 mètre de neige à la station, 2 mètres au-dessus de 1800 m et plus de 3 mètres dans les combes abritées.
Limite d'enneigement skiable : 1300 à 1500 m selon le versant.
État de la neige : On trouve en surface une couche de neige fraîche de plus en plus significative en montant mais le vent d'Ouest à Nord-ouest soutenu rend l'enneigement très hétérogène : les orientations Nord et Est sont souvent plus garnies que les pentes Ouest rapidement pelées ou verglacées dès que l'on se rapproche des crêtes et sommets. La neige est froide et poudreuse à l'abri du vent dès 1800 à 2000 m d'altitude, elle devient plus compacte, voire cartonnée dans les secteurs ventés. On trouve localement des accumulations de neige roulée. Corniches et accumulations parfois volumineuses sont en place.

Aperçu météo pour le vendredi 20 février

	nuit	matin	après-midi	soir
RETOUR DU SOLEIL, VENT DE NORD SUR LES CRETES				
Pluie-Neige	1 300 m			
Iso 0 °C	1 600 m	2 100 m	2 100 m	2 300 m
Vent 1500 m	90 km/h	40 km/h	40 km/h	25 km/h
Vent 2000 m	80 km/h	60 km/h	60 km/h	35 km/h

Épaisseur de neige hors-piste

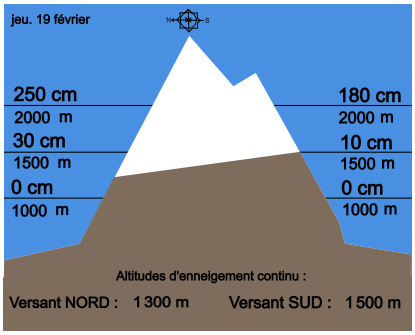

Précipitations à 1800 m

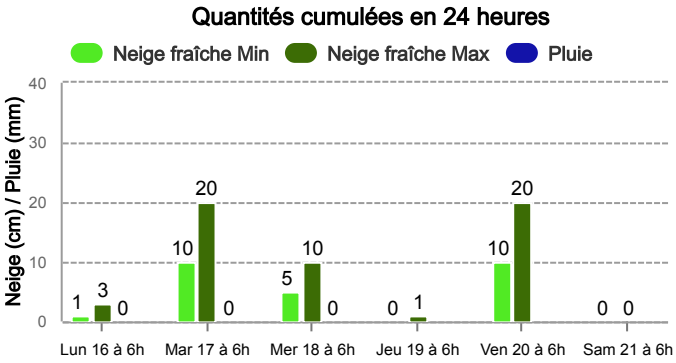

Tendance du samedi 21 février

2

Indice de risque limité

Soleil et douceur favorisent la stabilisation du manteau neigeux. Risque d'avalanche en baisse.

Pour consulter la vigilance en cours, veuillez vous rendre sur le site https://vigilance.meteofrance.fr/fr

Météo-France - 73 avenue de Paris, 94165 Saint-Mandé cedex - Contact : contact@meteo.fr

Rédigé par Météo-France avec la contribution des observateurs du réseau nivo-météorologiques. Partenariat : ANMSM (Maires de Stations de Montagne), DSF (Domaines Skiables de France), ADSP (Directeurs de Pistes et de la Sécurité des Stations de Sports d'Hiver) et autres acteurs de la montagne.

Bulletin neige & avalanches par téléphone au 0 892 68 10 20 Service 0,35 € / min + prix appel

RÉPUBLIQUE FRANÇAISE
Liberté Égalité Fraternité

METEO FRANCE
À VOS CÔTÉS, DANS UN CLIMAT QUI CHANGE

Bulletin d'estimation du risque d'avalanche

(valable en dehors des pistes balisées et ouvertes)

MASSIF : Renoso Incudine

Rédigé le jeudi 19 février 2026 à 15h

Conditions nivo-météo des 7 derniers jours

	ven. 13/02				sam. 14/02				dim. 15/02				lun. 16/02				mar. 17/02				mer. 18/02				jeu. 19/02			
	03h	09h	15h	21h	03h	09h	15h	21h	03h	09h	15h	21h	03h	09h	15h	21h	03h	09h	15h	21h	03h	09h	15h	21h	03h	09h	15h	21h
Météo																												
Vent (km/h)	60	50	35	70	50	40	30	50	40	50	50	50	90	100	110	120	110	70	60	50	45	55	45	40	60	70	80	100
à 2000m																												
Vent (km/h)	60	45	30	40	40	30	20	30	30	20	30	40	80	80	100	110	100	60	60	50	50	55	50	40	65	80	95	95
à 1500m																												

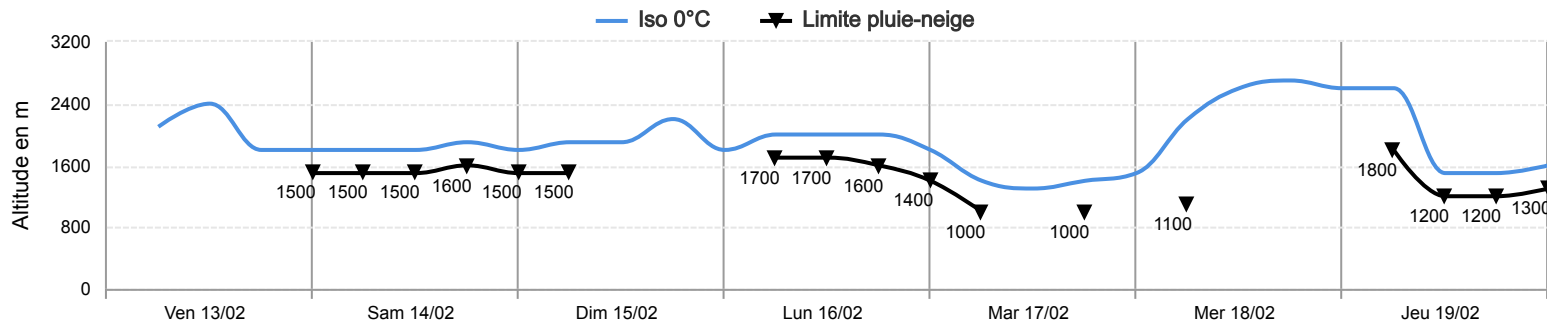

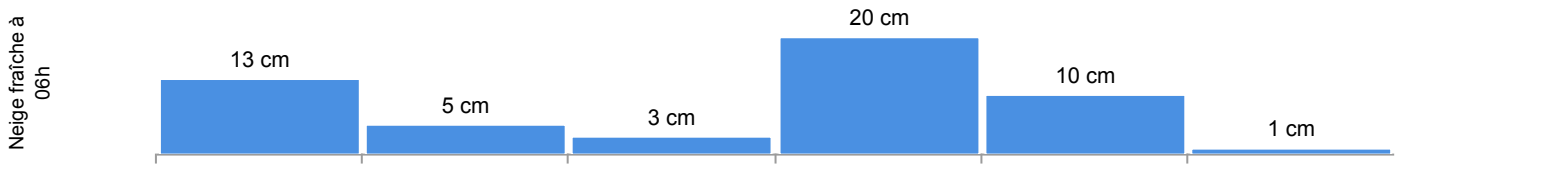

Risque d'avalanche							
	ven. 13/02	sam. 14/02	dim. 15/02	lun. 16/02	mar. 17/02	mer. 18/02	jeu. 19/02

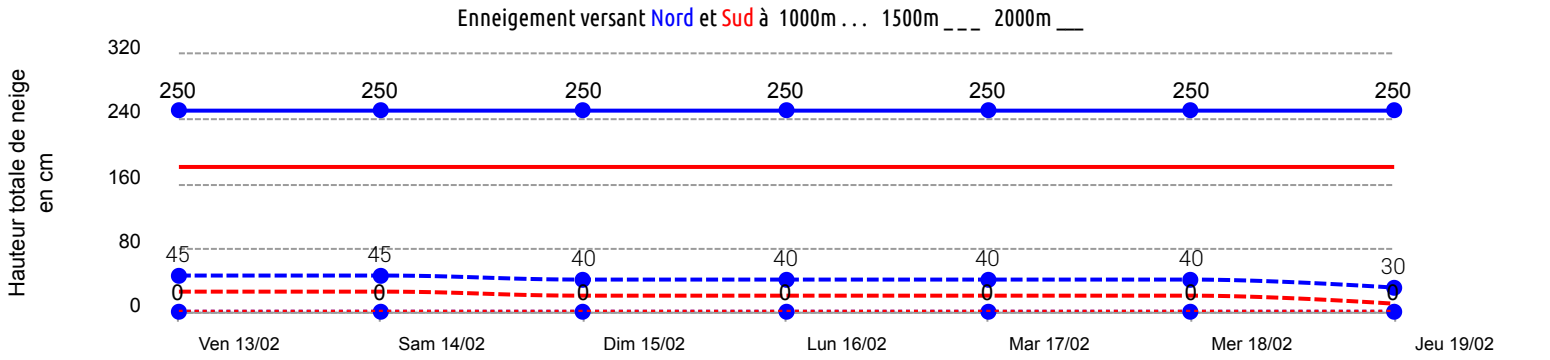

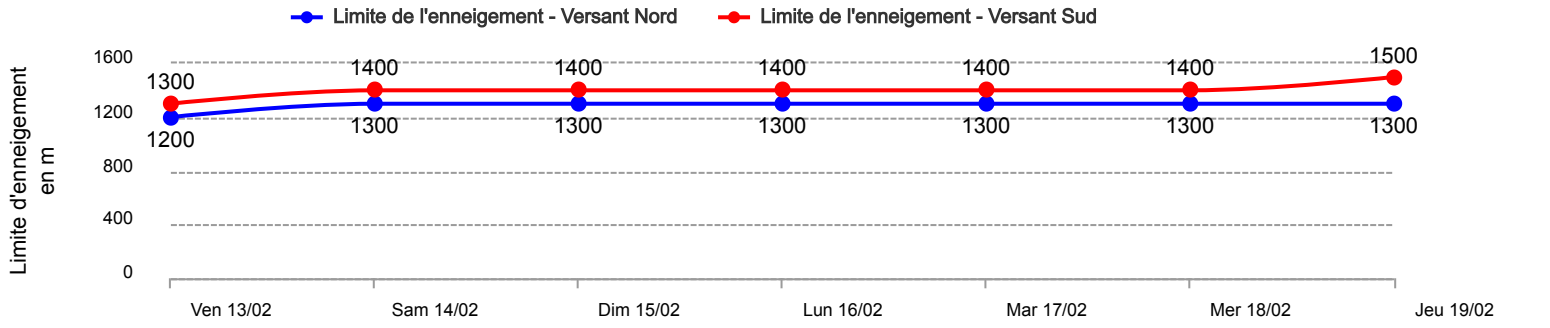

Pour consulter la vigilance en cours, veuillez vous rendre sur le site https://vigilance.meteofrance.fr/fr

Météo-France - 73 avenue de Paris, 94165 Saint-Mandé cedex - Contact : contact@meteo.fr

Rédigé par Météo-France avec la contribution des observateurs du réseau nivo-météorologiques. Partenariat : ANMSM (Maires de Stations de Montagne), DSF (Domaines Skiables de France), ADSP (Directeurs de Pistes et de la Sécurité des Stations de Sports d'Hiver) et autres acteurs de la montagne.

Bulletin neige & avalanches par téléphone au
0 892 68 10 20 Service 0,35 € / min + prix appel