RÉPUBLIQUE FRANÇAISE
Liberté Égalité Fraternité

METEO FRANCE
À VOS CÔTÉS, DANS UN CLIMAT QUI CHANGE

Bulletin d'estimation du risque d'avalanche
(valable en dehors des pistes balisées et ouvertes)
MASSIF : Capcir Puymorens

Rédigé le jeudi 19 février 2026 à 16h

Estimation des risques pour le : VENDREDI 20 FÉVRIER

NOMBREUSES PLAQUES FRIABLES

3

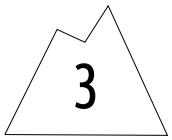

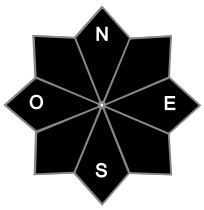

nouvelles plaques

Indice de risque marqué.

Départs spontanés : en neige récente, ponctuels et linéaires

Déclenchements provoqués : instabilités en neige récente et plaques à vent

Indices de risque : 5 très fort - 4 fort - 3 marqué - 2 limité - 1 faible -- En noir : les pentes les plus dangereuses

Stabilité du manteau neigeux

Situation avalancheuse typique : neige fraîche neige ventée

Déclenchements provoqués :
Des avalanches de **plaques** dans la neige récente sont **facilement déclenchables** par un randonneur. En effet de **nombreuses plaques** parfois friables et **difficilement détectables,** parfois un peu plus dures selon le travail du vent, se sont formées et se forment jusqu'à la mi-journée de vendredi en raison d'un vent turbulent ayant soufflé **à toutes altitudes.** Des cassures allant jusqu'à 50 cm à 1m sont à possibles à proximité de l'Ariège (Vallée du Galbe, Péric, Coma d'Or). Facteur aggravant : au-dessus de 2200m des grains anguleux ont pu se former localement les jours précédents et se retrouver enfouis sous la neige récente.
Observables : Traces de montée disparaissant rapidement (chasse-neige), fissures devant les skis, les plaques friables restent toutefois difficilement détectables car d'aspect poudreux.

Départs spontanés : Quelques départs ponctuels peuvent se produire dans les pentes raides pendant les chutes de neige par accumulation. Il s'agit surtout de petites coulées ou avalanches de taille 1. De plus, par effet de surcharge, quelques plaques friables pourront céder spontanément.
Autres :

Qualité de la neige

Enneigement : Malgré l'épisode de fonte de lundi, l'enneigement reste largement supérieur à celui des cinq dernières années et se situe à un très bon niveau par rapport aux statistiques plus anciennes. La barre des 2m de neige est souvent atteinte dès 2000m d'altitude.

Qualité de la neige :
A proximité de l'Ariège une couche de neige fraîche travaillée par le vent devrait être présente en surface vendredi matin. Cette neige repose sur un manteau compacté soit par la pluie du début de semaine jusqu'à 2200m, soit par le vent. Les crêtes et sommets peuvent se retrouver décapés par le vent violent.

Aperçu météo pour le vendredi 20 février

	nuit	matin	après-midi	soir
	Retour d'éclaircies en haute-montagne l'après-midi			
Pluie-Neige	1 200 m	1 300 m		
Iso 0 °C	1 700 m	1 900 m	2 400 m	2 400 m
Vent 2000 m	↘ 80 km/h	↘ 50 km/h	↘ 35 km/h	↘ 35 km/h
Vent 3000 m	↘ 95 km/h	↘ 80 km/h	↘ 60 km/h	↘ 45 km/h

Épaisseur de neige hors-piste

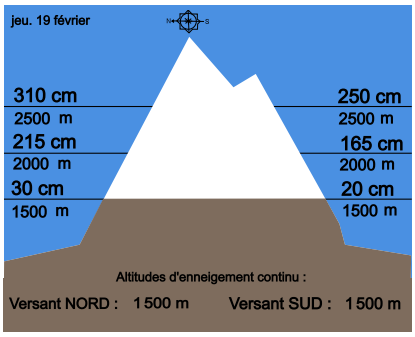

Précipitations à 1800 m

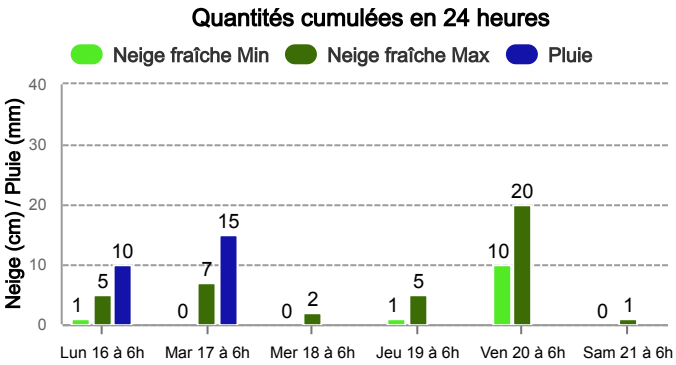

Tendance du samedi 21 février

3

Indice de risque marqué

Maintien d'un risque marqué malgré un début de stabilisation

Pour consulter la vigilance en cours, veuillez vous rendre sur le site https://vigilance.meteofrance.fr/fr

Météo-France - 73 avenue de Paris, 94165 Saint-Mandé cedex - Contact : contact@meteo.fr

Rédigé par Météo-France avec la contribution des observateurs du réseau nivo-météorologiques. Partenariat : ANMSM (Maires de Stations de Montagne), DSF (Domaines Skiables de France), ADSP (Directeurs de Pistes et de la Sécurité des Stations de Sports d'Hiver) et autres acteurs de la montagne.

Bulletin neige & avalanches par téléphone au
0 892 68 10 20 Service 0,35 € / min + prix appel

RÉPUBLIQUE FRANÇAISE
Liberté Égalité Fraternité

METEO FRANCE
À VOS CÔTÉS, DANS UN CLIMAT QUI CHANGE

Bulletin d'estimation du risque d'avalanche

(valable en dehors des pistes balisées et ouvertes)

MASSIF : Capcir Puymorens

Rédigé le jeudi 19 février 2026 à 16h

Conditions nivo-météo des 7 derniers jours

	ven. 13/02				sam. 14/02				dim. 15/02				lun. 16/02				mar. 17/02				mer. 18/02				jeu. 19/02			
	03h	09h	15h	21h	03h	09h	15h	21h	03h	09h	15h	21h	03h	09h	15h	21h	03h	09h	15h	21h	03h	09h	15h	21h	03h	09h	15h	21h
Météo																												
Vent (km/h)	55	60	50	90	80	100	110	90	105	80	70	70	95	100	105	120	120	110	90	75	65	55	70	80	70	90	105	105
à 3000m																												
Vent (km/h)	50	50	40	75	75	85	100	80	80	45	50	60	50	65	80	85	85	65	50	40	30	25	35	50	60	75	100	100
à 2000m																												

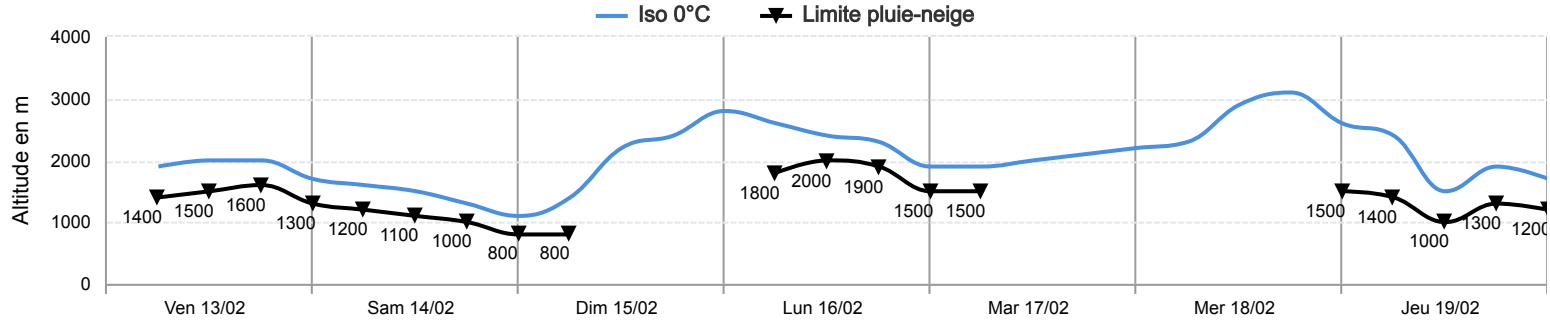

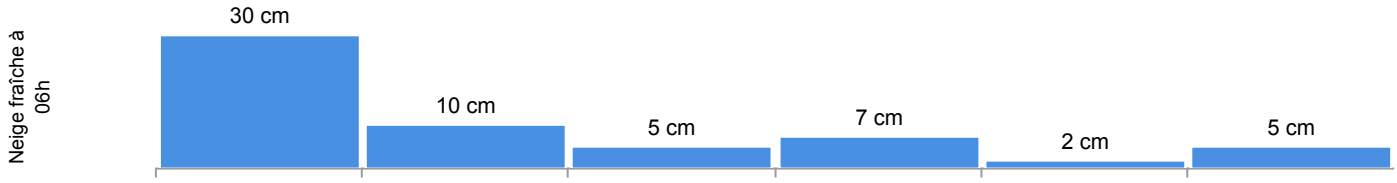

Risque d'avalanche	ven. 13/02	sam. 14/02	dim. 15/02	lun. 16/02	mar. 17/02	mer. 18/02	jeu. 19/02
	2	3	4	4	4	3	3

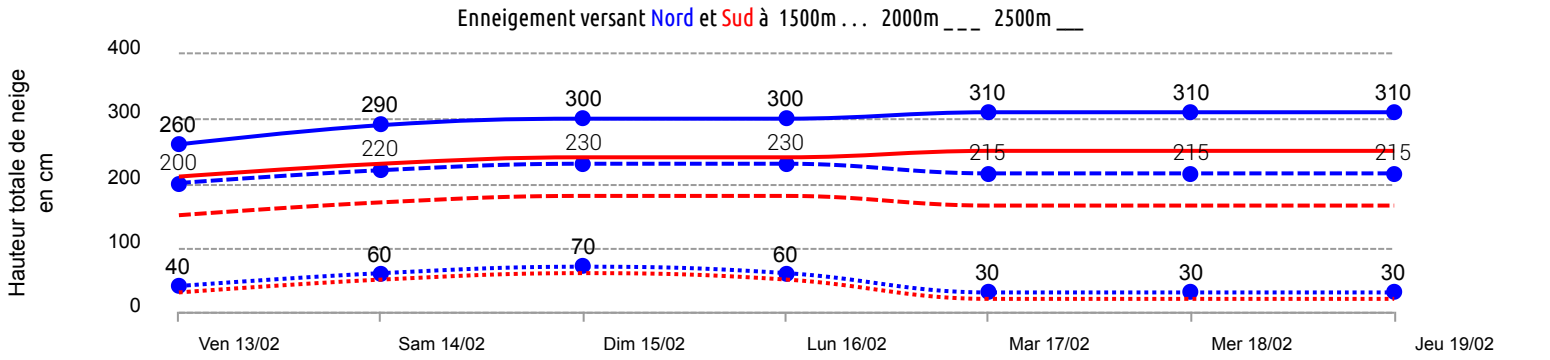

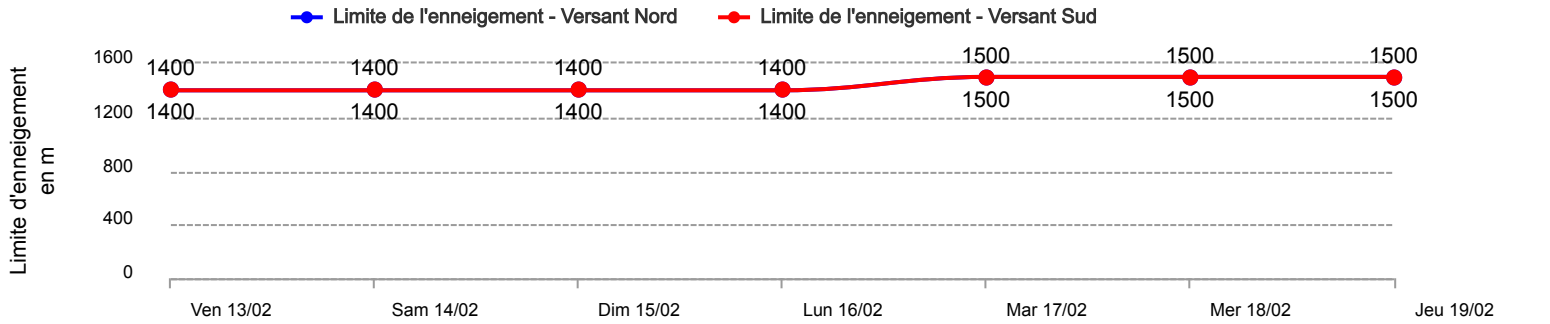

Pour consulter la vigilance en cours, veuillez vous rendre sur le site https://vigilance.meteofrance.fr/fr

Météo-France - 73 avenue de Paris, 94165 Saint-Mandé cedex - Contact : contact@meteo.fr

Rédigé par Météo-France avec la contribution des observateurs du réseau nivo-météorologiques. Partenariat : ANMSM (Maires de Stations de Montagne), DSF (Domaines Skiables de France), ADSP (Directeurs de Pistes et de la Sécurité des Stations de Sports d'Hiver) et autres acteurs de la montagne.

Bulletin neige & avalanches par téléphone au
0 892 68 10 20 Service 0,35 € / min + prix appel