Bulletin d'estimation du risque d'avalanche

(valable en dehors des pistes balisées et ouvertes)

MASSIF : Champsaur

Rédigé le jeudi 19 février 2026 à 16h

Estimation des risques pour le : VENDREDI 20 FÉVRIER

MANTEAU NEIGEUX TRÈS INSTABLE. NOMBREUSES INSTABILITÉS DANS LA NEIGE RÉCENTE VENTÉE - VIGILANCE ORANGE AVALANCHES

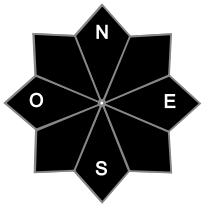

Indices de risque : 5 très fort - 4 fort - 3 marqué - 2 limité - 1 faible -- En noir : les pentes les plus dangereuses

Indice de risque fort.

Départs spontanés : principalement par surcharge du au vent ou lors des éclaircies en journée.

Déclenchements provoqués : nombreuses plaques dans la neige récente ventée, facilement déclenchables.

Vigilance orange avalanches en cours ou prévue sur le massif

Stabilité du manteau neigeux

Situation avalancheuse typique : neige fraîche — couche fragile persistante

Déclenchements provoqués : très nombreuses plaques dans la neige récente ventée, formées par les récentes chutes de neige et le fort vent. Elles sont présentes en toutes orientations, même si plus sensibles en orientations nord-est, est et sud-est, et sont encore facilement déclenchables au passage d'un seul skieur. Dans les combes bien abritées du vent, ces plaques sont encore d'aspect poudreux et donc difficilement identifiables. En revanche, à proximité des crêtes et sommets, ces plaques sont plutôt durcies par le vent et réparties de manière hétérogène, avec des accumulations localement épaisses. Cassures épaisses sur de grandes largeurs, engendrant des avalanches de taille moyenne à grande (taille 2 à 3). Une très grande avalanche (taille 4) est possible en cas de sollicitation d'une couche fragile persistante enfouie en ubacs, emportant une grande partie du manteau neigeux en place. Ce type de départ peut être initié par la surcharge liée au passage d'une première avalanche de surface.

Départs spontanés : avalanches de neige récente ventée. Départs ponctuels et superficiels au fil de l'ensoleillement : avalanches de taille petite à rarement moyenne. Départs parfois linéaires sous l'effet du transport par le vent de nord-ouest. Avalanches de taille moyenne (taille 2) ou grande (taille 3) en cas de déstabilisation d'une plaque en place. Une très grande avalanche (taille 4) n'est pas exclue.

Qualité de la neige

L'enneigement est excédentaire pour un mois de février. Les chutes de neige se succèdent depuis le début du mois de janvier.
Hauteurs de neige observées : 71 cm au hameau des Portes dans le Valgaudemar à 1270 m, 173 cm à la Nivôse d'Orcières à 2280 m, et 208 cm au-dessus de Prapic à 2480 m.

Limite d'enneigement skiable : la plupart des itinéraires sont skiables dès les fonds de vallées en ubacs, plutôt 1400/1500 m en adrets.

État de la neige de surface : épaisse couche de neige récente tombée entre jeudi et vendredi (localement jusqu'à 50/60 cm au cœur des Écrins). Neige froide et légère dans les pentes bien abritées du vent, mais plus travaillée par le vent à proximité des crêtes et sommets. Manteau neigeux hétérogène sur les crêtes parfois décapées ou avec de grosses accumulations (corniches).

Aperçu météo pour le vendredi 20 février

	nuit	matin	après-midi	soir

Quelques flocons résiduels vers l'Isère le matin puis retour d'un temps bien ensoleillé. Vent de nord fort.

Pluie-Neige	1 000 m	1 000 m		
Iso 0 °C	1 500 m	1 600 m	2 200 m	2 200 m
Vent 2000 m	55 km/h	45 km/h	40 km/h	40 km/h
Vent 3000 m	75 km/h	70 km/h	70 km/h	60 km/h

Épaisseur de neige hors-piste

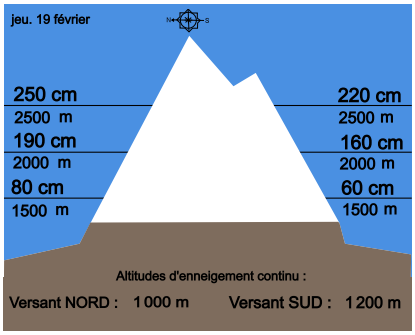

Précipitations à 1800 m

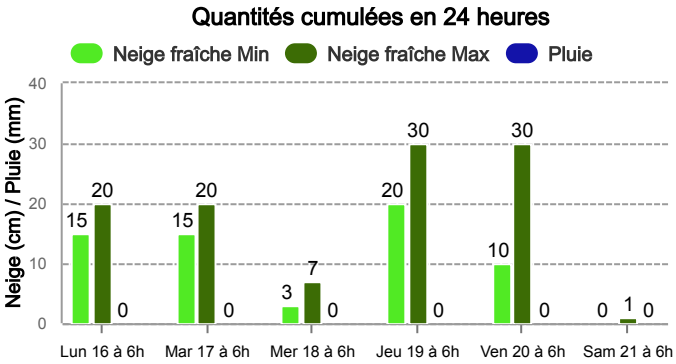

Tendance du samedi 21 février

Indice de risque marqué

Risque orienté à la baisse, mais restant bien marqué. Présence de plaques encore facilement déclenchables.

Pour consulter la vigilance en cours, veuillez vous rendre sur le site https://vigilance.meteofrance.fr/fr

Météo-France - 73 avenue de Paris, 94165 Saint-Mandé cedex - Contact : contact@meteo.fr

Rédigé par Météo-France avec la contribution des observateurs du réseau nivo-météorologiques. Partenariat : ANMSM (Maires de Stations de Montagne), DSF (Domaines Skiables de France), ADSP (Directeurs de Pistes et de la Sécurité des Stations de Sports d'Hiver) et autres acteurs de la montagne.

Bulletin neige & avalanches par téléphone au 0 892 68 10 20 Service 0,35 € / min + prix appel

Bulletin d'estimation du risque d'avalanche

(valable en dehors des pistes balisées et ouvertes)

MASSIF : Champsaur

Rédigé le jeudi 19 février 2026 à 16h

Conditions nivo-météo des 7 derniers jours

	ven. 13/02				sam. 14/02				dim. 15/02				lun. 16/02				mar. 17/02				mer. 18/02				jeu. 19/02			
	03h	09h	15h	21h	03h	09h	15h	21h	03h	09h	15h	21h	03h	09h	15h	21h	03h	09h	15h	21h	03h	09h	15h	21h	03h	09h	15h	21h
Météo																												
Vent (km/h)	60	20	40	50	80	80	60	60	60	70	50	40	80	100	130	120	105	95	80	75	45	30	25	50	45	50	65	60
à 3000m																												
Vent (km/h)	30	10	20	20	50	50	30	30	20	15	25	25	30	65	80	70	70	50	45	25	20	15	15	25	45	45	45	50
à 2000m																												

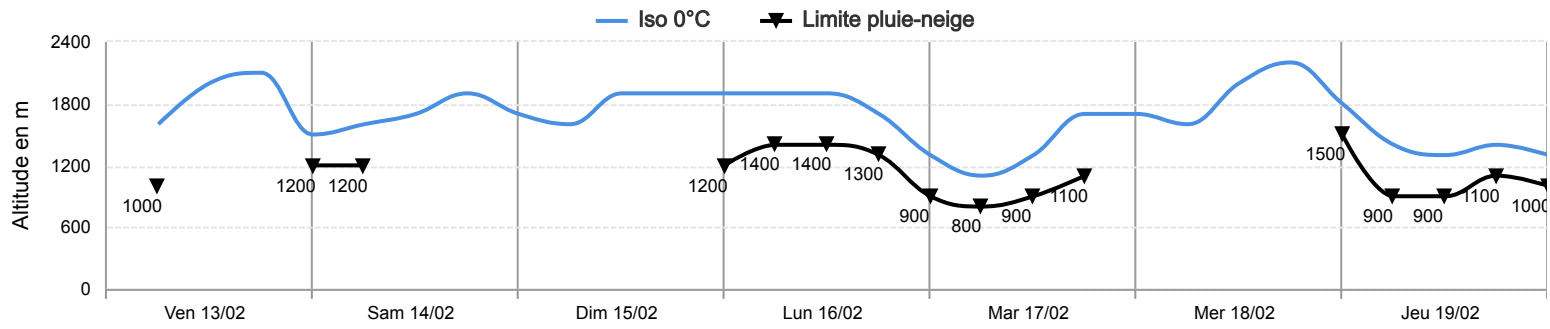

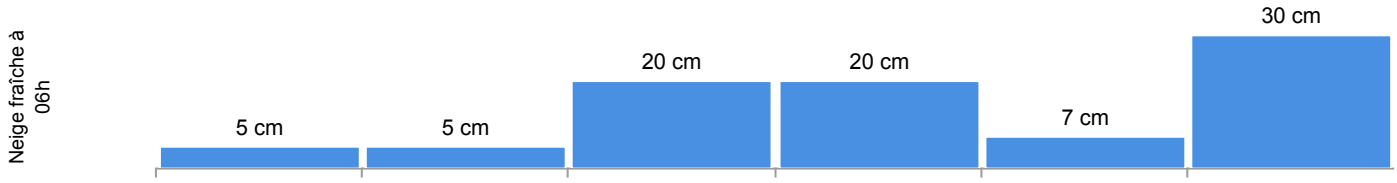

Risque d'avalanche	ven. 13/02	sam. 14/02	dim. 15/02	lun. 16/02	mar. 17/02	mer. 18/02	jeu. 19/02
	4	4	3	4	4	4	4

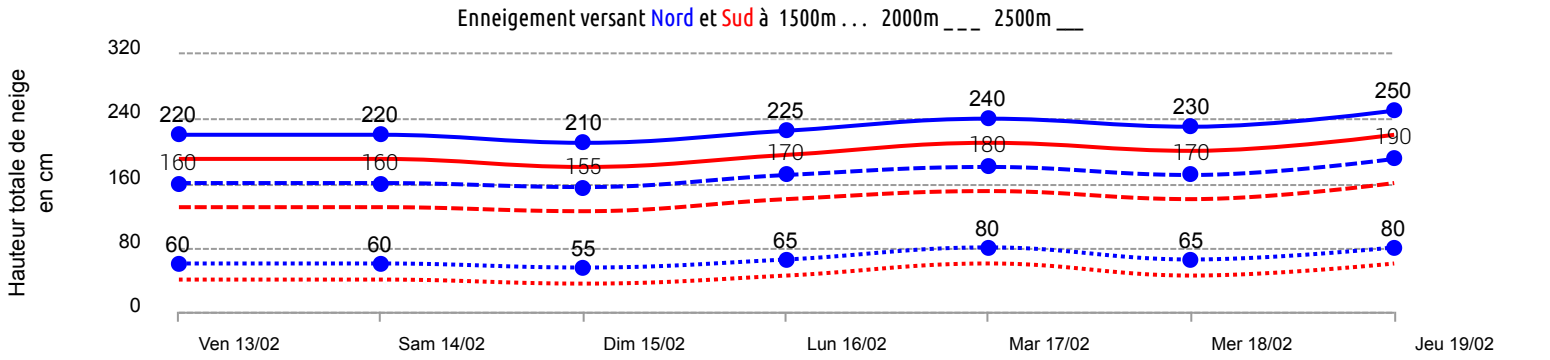

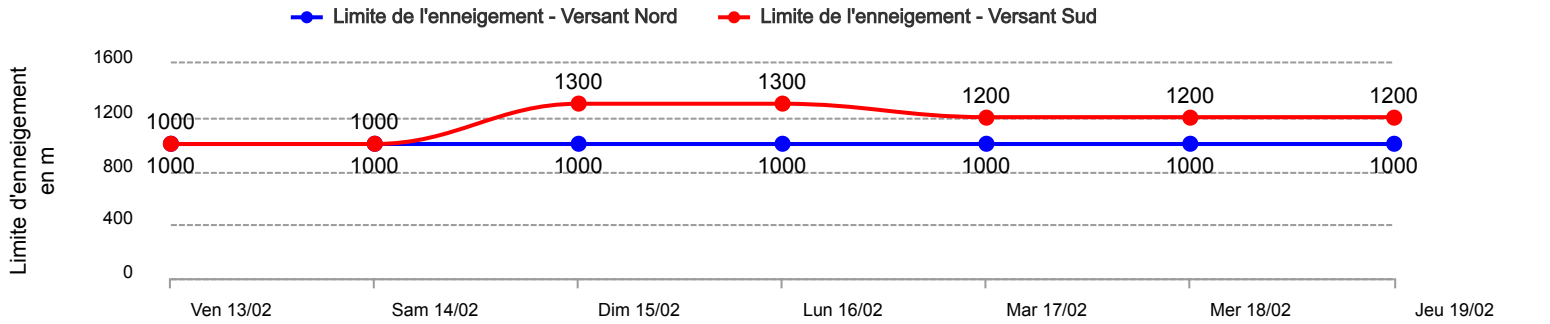

Pour consulter la vigilance en cours, veuillez vous rendre sur le site https://vigilance.meteofrance.fr/fr

Météo-France - 73 avenue de Paris, 94165 Saint-Mandé cedex - Contact : contact@meteo.fr

Rédigé par Météo-France avec la contribution des observateurs du réseau nivo-météorologiques. Partenariat : ANMSM (Maires de Stations de Montagne), DSF (Domaines Skiables de France), ADSP (Directeurs de Pistes et de la Sécurité des Stations de Sports d'Hiver) et autres acteurs de la montagne.

Bulletin neige & avalanches par téléphone au

0 892 68 10 20 Service 0,35 € / min + prix appel