Bulletin d'estimation du risque d'avalanche

(valable en dehors des pistes balisées et ouvertes)

MASSIF : Embrunais Parpaillon

Rédigé le jeudi 19 février 2026 à 16h

Estimation des risques pour le : VENDREDI 20 FÉVRIER

NOMBREUSES INSTABILITÉS DANS LA NEIGE RÉCENTE VENTÉE

3

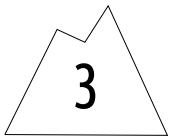

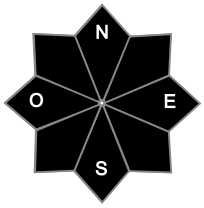

Indice de risque marqué.

Départs spontanés : principalement par surcharge du au vent ou lors des éclaircies en journée.

Déclenchements provoqués : plaques dans la neige récente ventée, facilement déclenchables.

Indices de risque : 5 très fort - 4 fort - 3 marqué - 2 limité - 1 faible -- En noir : les pentes les plus dangereuses

Stabilité du manteau neigeux

Situation avalancheuse typique : neige ventée couche fragile persistante

Déclenchements provoqués : nombreuses plaques dans la neige récente ventée, formées par les récentes chutes de neige et le fort vent. Elles sont présentes en toutes orientations, même si plus sensibles en orientations nord-est, est et sud-est, et sont encore facilement déclenchables au passage d'un seul skieur. Dans les combes bien abritées du vent, ces plaques sont encore d'aspect poudreux et donc difficilement identifiables. En revanche, à proximité des crêtes et sommets, ces plaques sont plutôt durcies par le vent et réparties de manière hétérogène, avec des accumulations localement épaisses. Ces plaques engendrent généralement des avalanches de taille petite à moyenne (taille 1 à 2). Une grande avalanche (taille 3), voire exceptionnellement une très grande (T4) est possible en cas de sollicitation d'une couche fragile persistante enfouie en ubacs, emportant une grande partie du manteau neigeux en place. Ce type de départ peut être initié par la surcharge liée au passage d'une première avalanche de surface.

Départs spontanés : nombreuses avalanches de neige fraîche au fil des chutes de neige ventées qui se déposent sur un manteau neigeux encore peu stabilisé. Avalanches de taille moyenne (taille 2) ou grande (taille 3) en cas de déstabilisation d'une plaque en place.

Qualité de la neige

L'enneigement est légèrement excédentaire pour un mois de février.
Hauteurs de neige observées : 102 cm à la Nivôse du Parpaillon à 2550 m, secteur soufflé par le vent.

Limite d'enneigement skiable : dès 1200/1400 m en ubacs sur la plupart des itinéraires, plutôt 1400/1500 m en adrets favorables.

État de la neige de surface : jeudi matin, les chutes de neige de la nuit ont apporté entre 10 et 15 cm et se poursuivent en journée mais de manière faible. Cette neige tombe froide et légère dans les endroits bien abrités du vent, mais est plus travaillée par le vent dans les endroits exposés. Crêtes souvent décapées par le vent de nord-ouest fort des derniers jours, alternant avec de grosses accumulations / corniches.

Aperçu météo pour le vendredi 20 février

	nuit	matin	après-midi	soir

Rares flocons dans la nuit de jeudi à vendredi puis temps bien ensoleillé en journée de vendredi. Vent de nord fort.

Pluie-Neige	1 000 m			
Iso 0 °C	1 500 m	1 800 m	2 200 m	2 200 m
Vent 2000 m	↘ 25 km/h	↓ 50 km/h	↙ 40 km/h	↙ 50 km/h
Vent 3000 m	↘ 70 km/h	↓ 60 km/h	↓ 60 km/h	↓ 60 km/h

Épaisseur de neige hors-piste

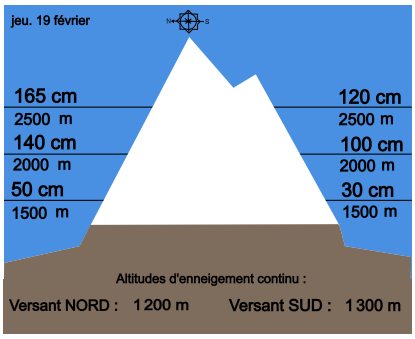

Précipitations à 1800 m

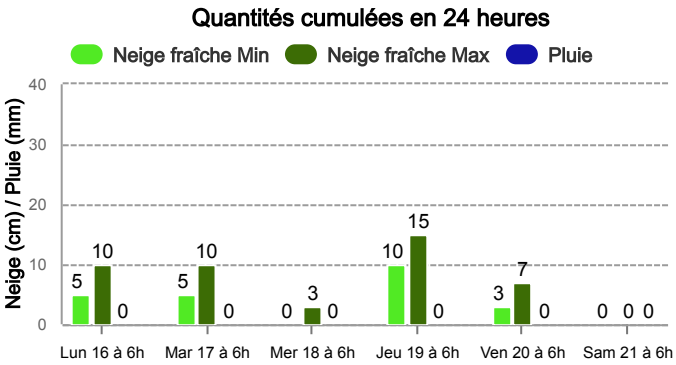

Tendance du samedi 21 février

3

Indice de risque marqué

Risque restant marqué. Des plaques sont en plaques, encore facilement déclenchables.

Pour consulter la vigilance en cours, veuillez vous rendre sur le site https://vigilance.meteofrance.fr/fr

Météo-France - 73 avenue de Paris, 94165 Saint-Mandé cedex - Contact : contact@meteo.fr

Rédigé par Météo-France avec la contribution des observateurs du réseau nivo-météorologiques. Partenariat : ANMSM (Maires de Stations de Montagne), DSF (Domaines Skiables de France), ADSP (Directeurs de Pistes et de la Sécurité des Stations de Sports d'Hiver) et autres acteurs de la montagne.

Bulletin neige & avalanches par téléphone au 0 892 68 10 20 Service 0,35 € / min + prix appel

Bulletin d'estimation du risque d'avalanche

(valable en dehors des pistes balisées et ouvertes)

MASSIF : Embrunais Parpaillon

Rédigé le jeudi 19 février 2026 à 16h

Conditions nivo-météo des 7 derniers jours

	ven. 13/02				sam. 14/02				dim. 15/02				lun. 16/02				mar. 17/02				mer. 18/02				jeu. 19/02			
	03h	09h	15h	21h	03h	09h	15h	21h	03h	09h	15h	21h	03h	09h	15h	21h	03h	09h	15h	21h	03h	09h	15h	21h	03h	09h	15h	21h
Météo																												
Vent (km/h)	50	30	30	50	60	60	40	70	60	80	50	45	70	110	130	110	95	85	75	70	45	40	35	60	55	50	70	55
à 3000m																												
Vent (km/h)	20	10	15	20	25	25	25	30	30	30	20	20	20	60	75	65	55	40	35	20	15	15	15	20	25	25	35	20
à 2000m																												

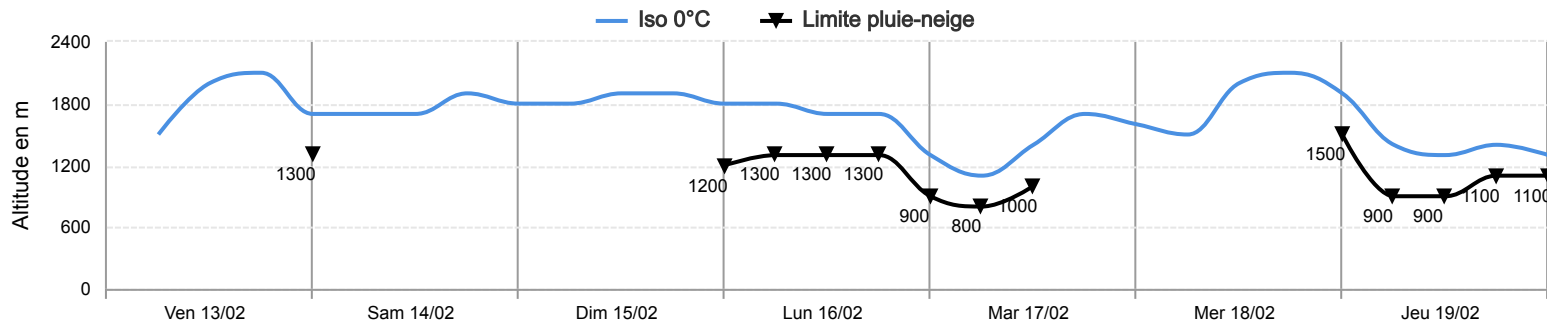

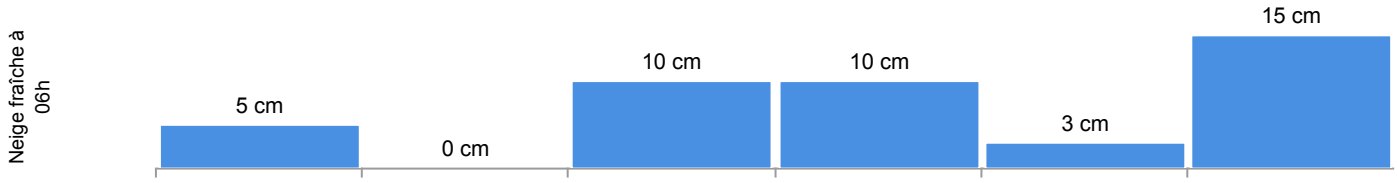

Risque d'avalanche	ven. 13/02	sam. 14/02	dim. 15/02	lun. 16/02	mar. 17/02	mer. 18/02	jeu. 19/02
	4	4	3	3	3	3	4

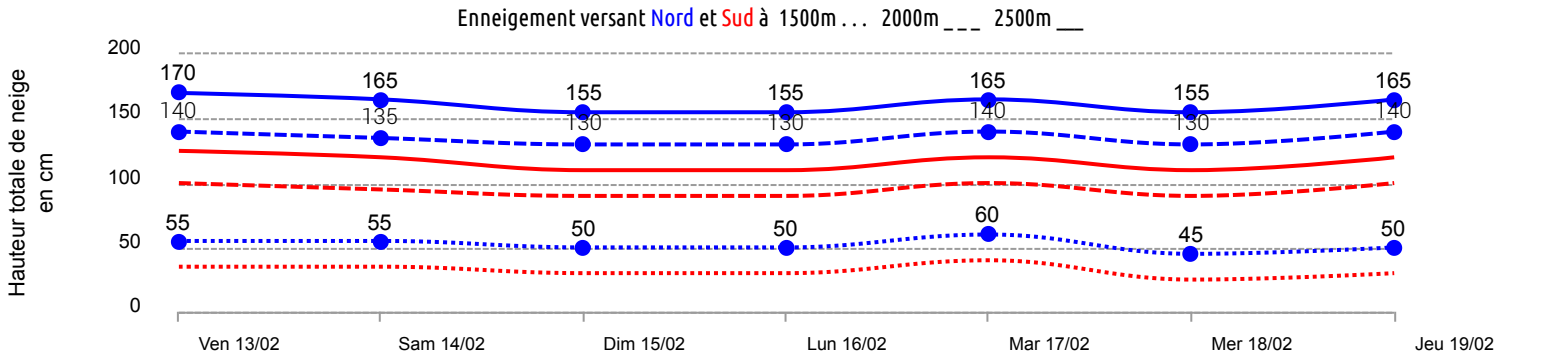

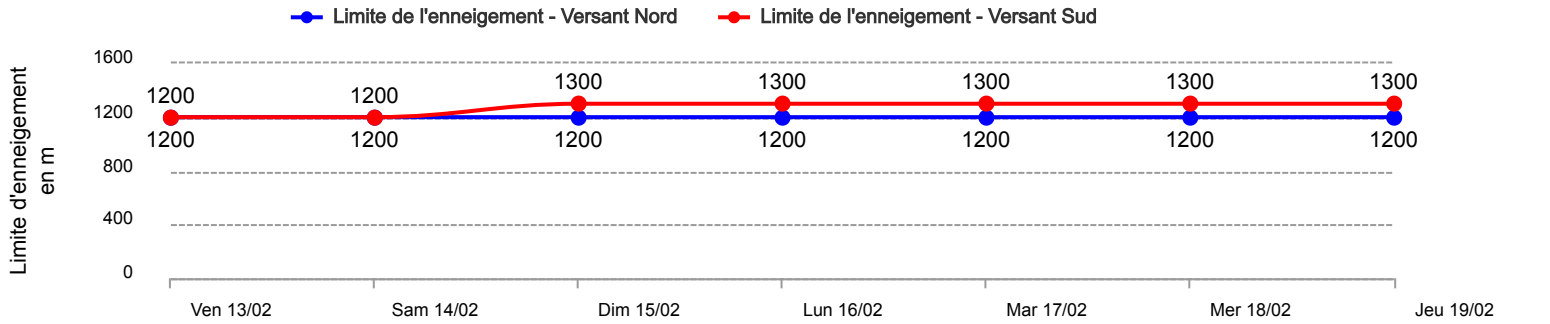

Pour consulter la vigilance en cours, veuillez vous rendre sur le site https://vigilance.meteofrance.fr/fr

Météo-France - 73 avenue de Paris, 94165 Saint-Mandé cedex - Contact : contact@meteo.fr

Bulletin neige & avalanches par téléphone au

0 892 68 10 20 Service 0,35 € / min + prix appel

Rédigé par Météo-France avec la contribution des observateurs du réseau nivo-météorologiques. Partenariat : ANMSM (Maires de Stations de Montagne), DSF (Domaines Skiables de France), ADSP (Directeurs de Pistes et de la Sécurité des Stations de Sports d'Hiver) et autres acteurs de la montagne.