Bulletin d'estimation du risque d'avalanche

(valable en dehors des pistes balisées et ouvertes)

MASSIF : Luchonnais

Rédigé le jeudi 19 février 2026 à 16h

Estimation des risques pour le : VENDREDI 20 FÉVRIER

CHUTES DE NEIGE VENTEES.

3

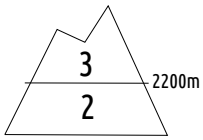

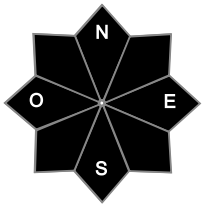

Au-dessus de 2200m indice de risque marqué, plus bas indice limité.

Départs spontanés : En neige récente, ponctuels et linéaires.

Déclenchements provoqués : Instabilités en neige récente et plaques à vent.

Indices de risque : 5 très fort - 4 fort - 3 marqué - 2 limité - 1 faible -- En noir : les pentes les plus dangereuses

Stabilité du manteau neigeux

Situation avalancheuse typique : neige fraîche neige ventée

Déclenchements provoqués : risque **marqué** de déclenchement de **plaques instables** formées ce jeudi **continuant à se former et s'épaississant en tous secteurs** sous le **vent de nord-ouest soutenu**. Une **faible sollicitation** d'un skieur ou randonneur est **suffisante pour déclencher des avalanches de plaques de taille 2 à 3,** avec dépôts de blocs, durs en versants Ouest à Nord plus ventés, plus pulvérulents partout ailleurs. Tant que l'humidification n'est pas entamée en larges secteurs sud en après-midi vendredi, **tous les secteurs** sont susceptibles de présenter ce risque.

Observables : travail du vent visible et **plaques facilement identifiables** en versants **Ouest à Nord**, mais **peu visibles et d'aspect poudreux dans les autres secteurs**.

Départs spontanés : En **neige récente**, en **tous secteurs raides**. Généralement **coulées ou avalanches moyennes en départs ponctuels en matinée. Puis des moyennes plus fréquentes en cours d'après-midi** avec les éclaircies et de rares grandes restent possibles généralement en large secteurs sud.
Autres : Cassures linéaires pouvant atteindre 30 cm dans les versants Est à Sud déventés où se constituent les accumulations les plus importantes. **Cassures localement plus épaisses** (50 à 100 cm) et **déclenchement plus rare de mille-feuilles avec possible** risque d'avalanche de **taille 4** en partant d'une **accumulation encore en place au-dessus de 2200 m. Supposition de grains anguleux en sous-couche rendant les plaques encore plus instables en certains secteurs au-dessus de 2400 m.**

Qualité de la neige

Enneigement : nouvelles chutes de neige redonnant un aspect plus hivernal au massif, saupoudrage à partir de 1000 m. Crêtes, cols et sommets pelés en expositions Ouest, en neige dure à très dure partout ailleurs.
Limites skiables : à partir de 1300 m suivant les versants, car sans sous-couche en dessous.
État de la neige : couche de neige fraîche généralement de 15 à 25 cm vendredi matin, frittée à cartonnée dans les pentes ouest à nord. répartition hétérogène et frittée à cartonnée en gagnant en altitude.

Aperçu météo pour le vendredi 20 février

	nuit	matin	après-midi	soir

Quelques flocons en matinée évoluant en goutellettes vers 1500 m, éclaircies en après-midi, nombreux nuages. Ciel dégagé au cours de la nuit suivante.

Pluie-Neige	1 100 m			
Iso 0 °C	1 400 m	1 500 m	2 200 m	2 400 m
Vent 2000 m	50 km/h	25 km/h	15 km/h	10 km/h
Vent 3000 m	80 km/h	80 km/h	55 km/h	50 km/h

Épaisseur de neige hors-piste

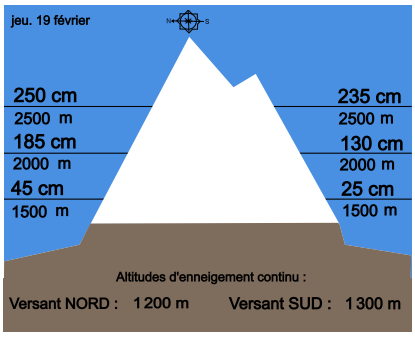

Précipitations à 1800 m

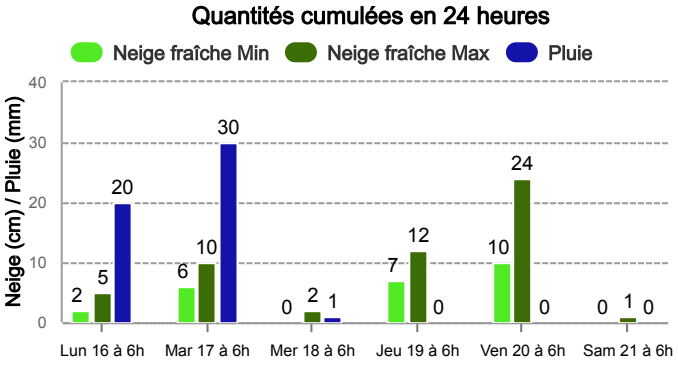

Tendance du samedi 21 février

3

Indice de risque marqué

Avalanches de neige humide sous le soleil, plaques restant fragiles en haut du massif en nord.

Pour consulter la vigilance en cours, veuillez vous rendre sur le site https://vigilance.meteofrance.fr/fr

Météo-France - 73 avenue de Paris, 94165 Saint-Mandé cedex - Contact : contact@meteo.fr

Rédigé par Météo-France avec la contribution des observateurs du réseau nivo-météorologiques. Partenariat : ANMSM (Maires de Stations de Montagne), DSF (Domaines Skiables de France), ADSP (Directeurs de Pistes et de la Sécurité des Stations de Sports d'Hiver) et autres acteurs de la montagne.

Bulletin neige & avalanches par téléphone au **0 892 68 10 20** Service 0,35 € / min + prix appel

RÉPUBLIQUE FRANÇAISE
Liberté Égalité Fraternité

METEO FRANCE
À VOS CÔTÉS, DANS UN CLIMAT QUI CHANGE

Bulletin d'estimation du risque d'avalanche

(valable en dehors des pistes balisées et ouvertes)

MASSIF : Luchonnais

Rédigé le jeudi 19 février 2026 à 16h

Conditions nivo-météo des 7 derniers jours

	ven. 13/02				sam. 14/02				dim. 15/02				lun. 16/02				mar. 17/02				mer. 18/02				jeu. 19/02			
	03h	09h	15h	21h	03h	09h	15h	21h	03h	09h	15h	21h	03h	09h	15h	21h	03h	09h	15h	21h	03h	09h	15h	21h	03h	09h	15h	21h
Météo																												
Vent (km/h)	85	75	100	115	85	60	65	40	35	40	80	90	90	85	75	80	60	55	60	65	55	80	95	85	90	110	95	80
à 3000m																												
Vent (km/h)	60	50	45	75	55	55	55	40	40	15	35	50	55	35	60	60	55	45	10	15	25	60	75	45	70	70	70	60
à 2000m																												

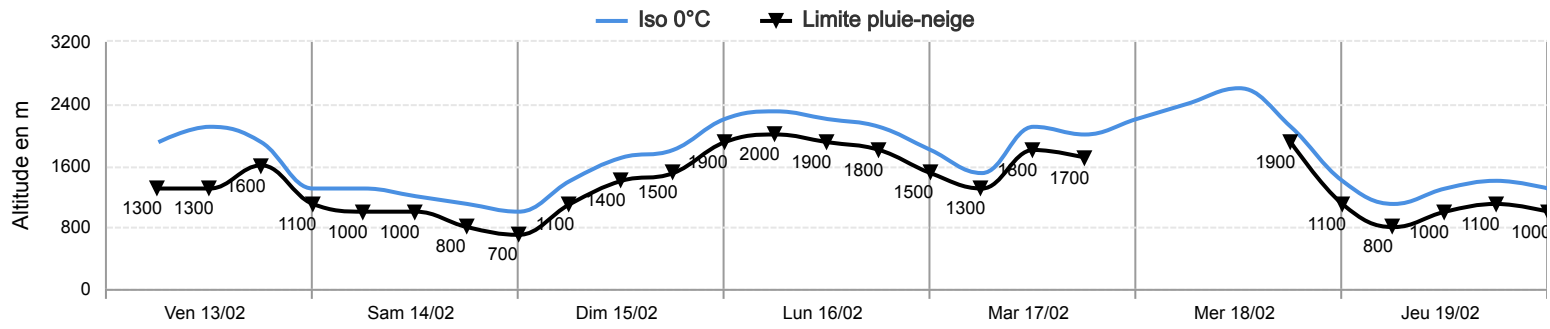

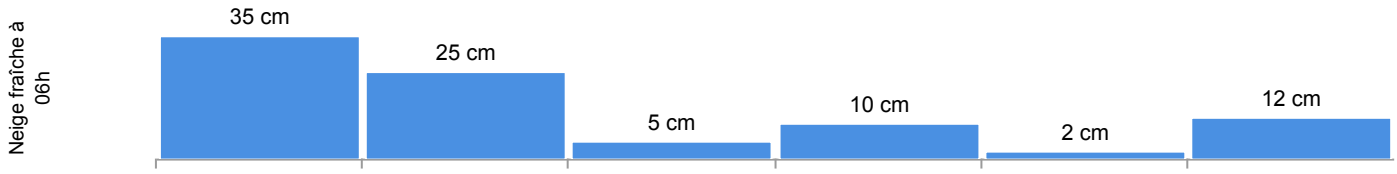

Risque d'avalanche							
	2	3	4	4	4	3	3
	ven. 13/02	sam. 14/02	dim. 15/02	lun. 16/02	mar. 17/02	mer. 18/02	jeu. 19/02

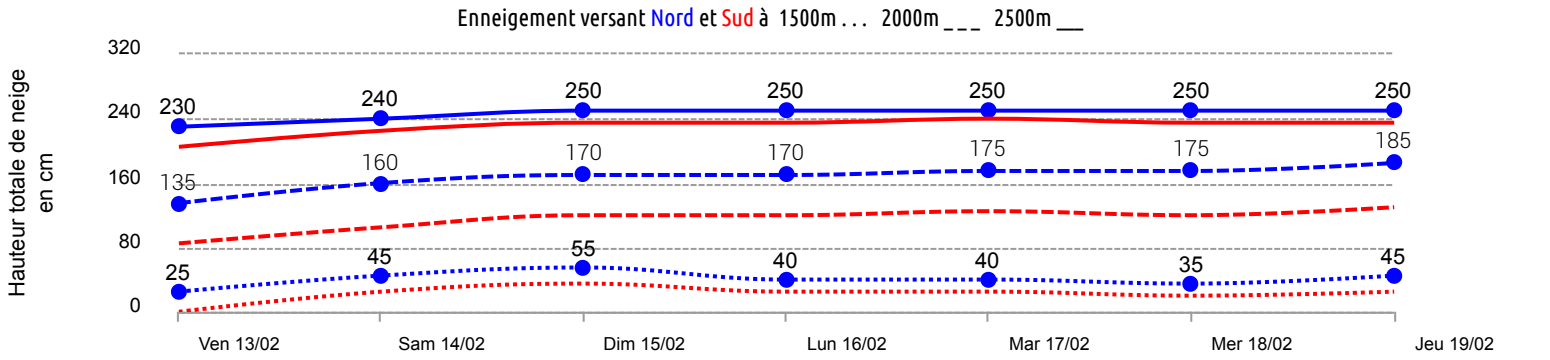

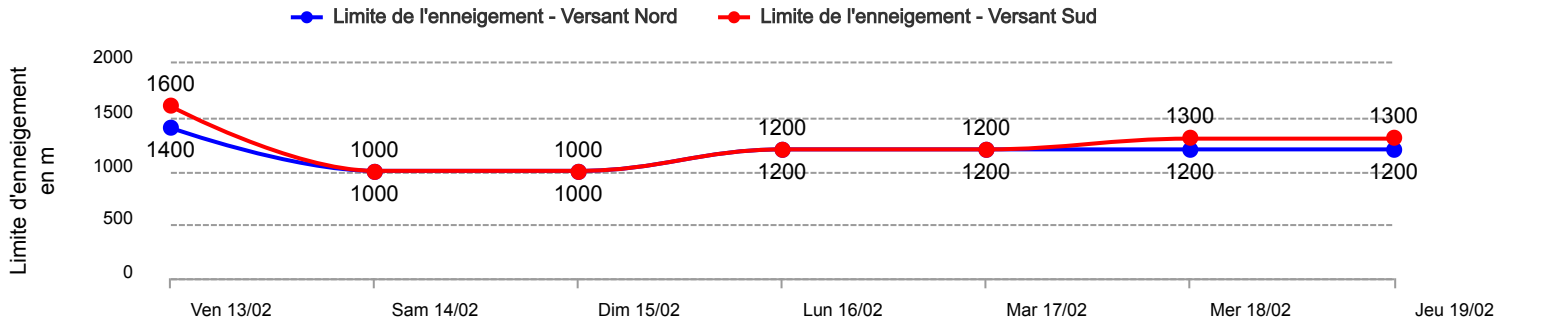

Pour consulter la vigilance en cours, veuillez vous rendre sur le site https://vigilance.meteofrance.fr/fr

Météo-France - 73 avenue de Paris, 94165 Saint-Mandé cedex - Contact : contact@meteo.fr

Rédigé par Météo-France avec la contribution des observateurs du réseau nivo-météorologiques. Partenariat : ANMSM (Maires de Stations de Montagne), DSF (Domaines Skiables de France), ADSP (Directeurs de Pistes et de la Sécurité des Stations de Sports d'Hiver) et autres acteurs de la montagne.

Bulletin neige & avalanches par téléphone au
0 892 68 10 20 Service 0,35 € / min + prix appel