Bulletin d'estimation du risque d'avalanche
(valable en dehors des pistes balisées et ouvertes)

MASSIF : Mercantour

Rédigé le jeudi 19 février 2026 à 16h

Estimation des risques pour le : VENDREDI 20 FÉVRIER

NOMBREUSES INSTABILITÉS DANS LA NEIGE FRAÎCHE VENTÉE

3

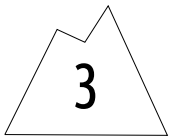

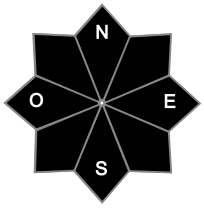

Indice de risque marqué.

Départs spontanés : quelques départs par transport par le vent de nord, ou par humidification au soleil.

Déclenchements provoqués : nombreuses instabilités dans la neige récente ventée.

Indices de risque : 5 très fort - 4 fort - 3 marqué - 2 limité - 1 faible -- En noir : les pentes les plus dangereuses

Stabilité du manteau neigeux

Situation avalancheuse typique : neige ventée neige fraîche

Déclenchements provoqués :
Nombreuses instabilités en place ou en formation dans la neige récente ventée, possibles en toutes orientations, en particulier au dessus de 2000 m, même loin des crêtes. Les plaques formées en surface du manteau neigeux sont d'aspect durci par le vent à l'approche des crêtes où elles sont réparties de manière plus hétérogène, sinon encore poudreuses et difficiles à détecter dans les secteurs plus abrités. Elles peuvent être faciles à déclencher au passage d'un seul skieur, engendrant des avalanches de taille généralement petite à moyenne (taille 1 à 2), une rare grande est possible dans les zones de forte accumulation, plutôt en secteur est à sud.

Départs spontanés : quelques départs linaires en neige ventée, par transport de neige récente sous l'effet du vent de nord. Avalanches petites à moyennes, localement une grande taille est possible dans les zones de forte accumulation. Quelques petites avalanches sont également possibles par humidification du manteau neigeux superficiel : départs ponctuels en pentes raides ensoleillées, souvent près des rochers.

Qualité de la neige

Enneigement très excédentaire pour un mois de février. Il faut remonter à 2015 pour trouver un enneigement encore plus abondant à cette période de l'année.
Données observées : 160 cm à la nivôse de Millefonts à 2430 m.

Enneigement skiable dès 1300 m en ubacs en terrains favorables et 1600 m en adrets

État de la neige en surface : autour de 10/20 cm de neige récente, durcie par le vent en secteurs exposés, ou encore poudreuse dans les zones abritées. Elle repose sur une couche parfois épaisse de neige récente souvent déjà travaillée par le vent en altitude, restée légère et poudreuse en ubacs abrités du vent, notamment en forêts de moyenne altitude. En matinée, poursuite du transport et de la densification de la neige récente par le vent de nord.

Aperçu météo pour le vendredi 20 février

nuit	matin	après-midi	soir

Temps bien ensoleillé, parfois voilé. Vent de nord encore sensible jusqu'au matin en altitude, faiblissant progressivement en journée.

Pluie-Neige				
Iso 0 °C	1 900 m	2 400 m	2 600 m	2 500 m
Vent 2000 m	45 km/h	40 km/h	15 km/h	15 km/h
Vent 3000 m	75 km/h	60 km/h	50 km/h	30 km/h

Épaisseur de neige hors-piste

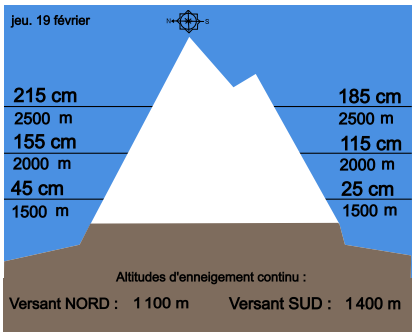

Précipitations à 1800 m

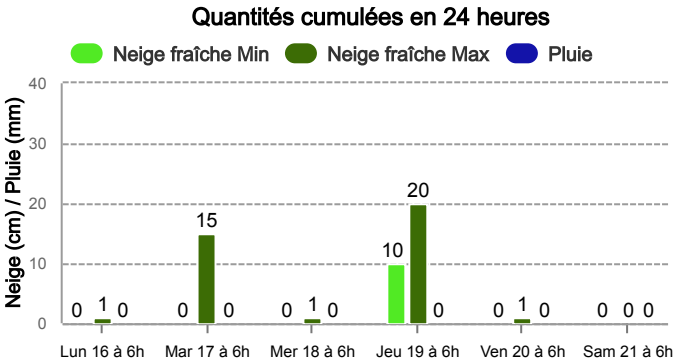

Tendance du samedi 21 février

3

Indice de risque marqué

Risque restant marqué, avec encore des plaques en place en surface du manteau neigeux, et une augmentation de l'activité naturelle en neige humide avec un temps ensoleillé et des températures en hausse.

Pour consulter la vigilance en cours, veuillez vous rendre sur le site https://vigilance.meteofrance.fr/fr

Météo-France - 73 avenue de Paris, 94165 Saint-Mandé cedex - Contact : contact@meteo.fr

Rédigé par Météo-France avec la contribution des observateurs du réseau nivo-météorologiques. Partenariat : ANMSM (Maires de Stations de Montagne), DSF (Domaines Skiables de France), ADSP (Directeurs de Pistes et de la Sécurité des Stations de Sports d'Hiver) et autres acteurs de la montagne.

Bulletin neige & avalanches par téléphone au
0 892 68 10 20 Service 0,35 € / min + prix appel

RÉPUBLIQUE FRANÇAISE
Liberté Égalité Fraternité

METEO FRANCE
À VOS CÔTÉS, DANS UN CLIMAT QUI CHANGE

Bulletin d'estimation du risque d'avalanche

(valable en dehors des pistes balisées et ouvertes)

MASSIF : Mercantour

Rédigé le jeudi 19 février 2026 à 16h

Conditions nivo-météo des 7 derniers jours

	ven. 13/02				sam. 14/02				dim. 15/02				lun. 16/02				mar. 17/02				mer. 18/02				jeu. 19/02			
	03h	09h	15h	21h	03h	09h	15h	21h	03h	09h	15h	21h	03h	09h	15h	21h	03h	09h	15h	21h	03h	09h	15h	21h	03h	09h	15h	21h
Météo																												
Vent (km/h)	55	30	40	50	80	90	75	65	45	30	40	50	55	75	100	80	75	70	50	40	35	25	35	75	55	55	80	80
à 3000m																												
Vent (km/h)	30	20	25	20	50	75	65	50	30	10	20	30	30	40	65	40	60	50	20	20	15	15	20	40	30	35	35	45
à 2000m																												

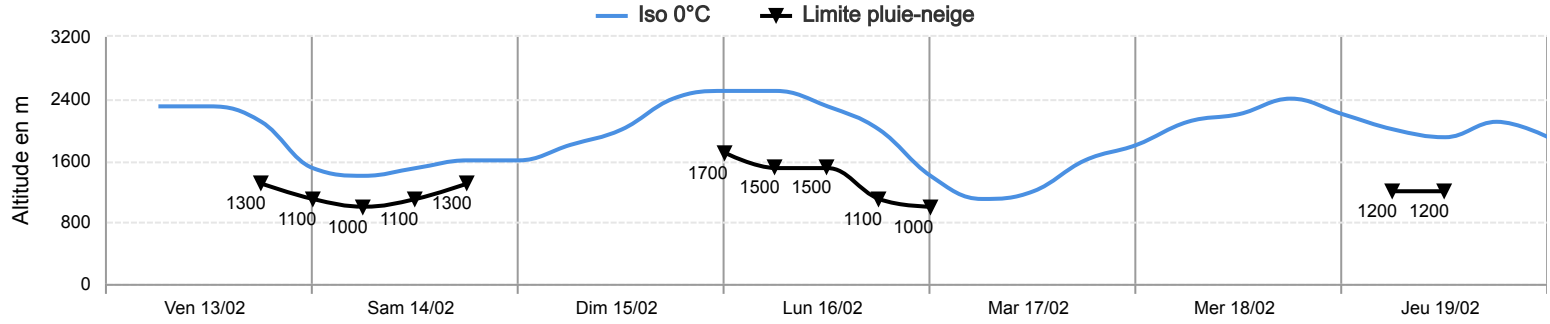

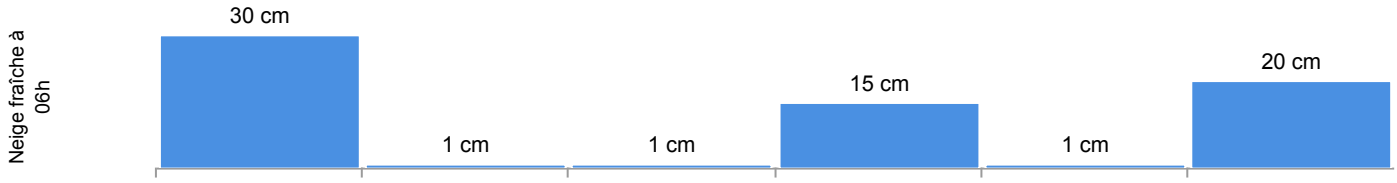

Risque d'avalanche	ven. 13/02	sam. 14/02	dim. 15/02	lun. 16/02	mar. 17/02	mer. 18/02	jeu. 19/02
	2	3	3	3	3	3	3

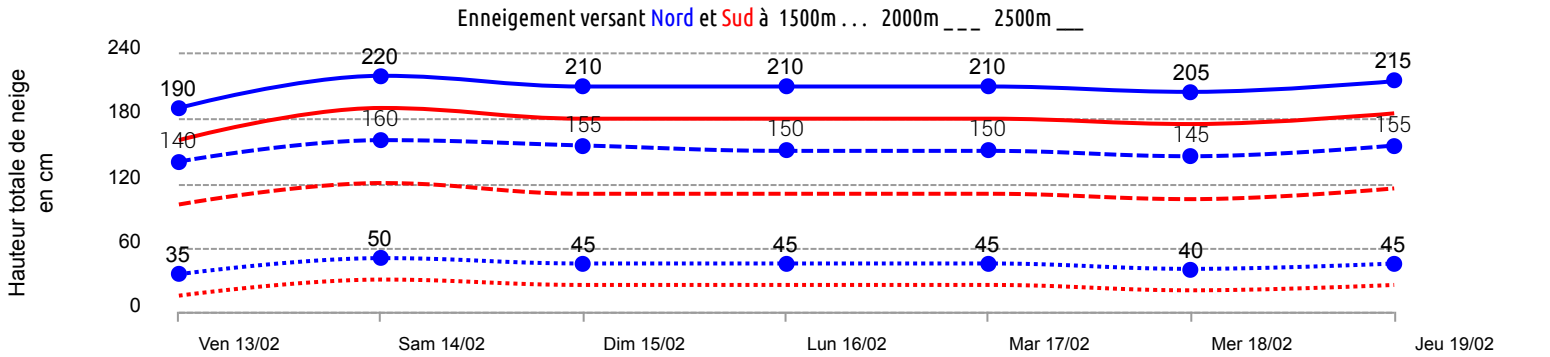

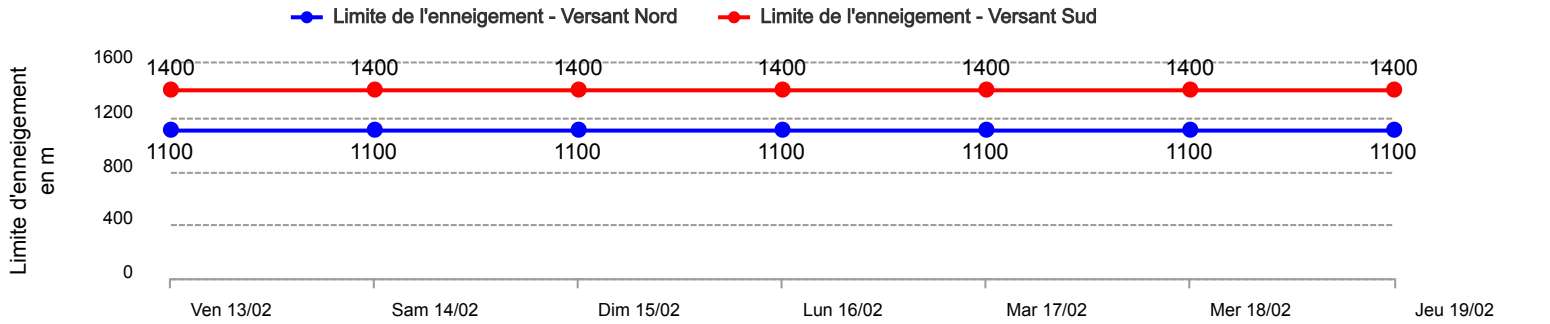

Pour consulter la vigilance en cours, veuillez vous rendre sur le site https://vigilance.meteofrance.fr/fr

Météo-France - 73 avenue de Paris, 94165 Saint-Mandé cedex - Contact : contact@meteo.fr

Rédigé par Météo-France avec la contribution des observateurs du réseau nivo-météorologiques. Partenariat : ANMSM (Maires de Stations de Montagne), DSF (Domaines Skiables de France), ADSP (Directeurs de Pistes et de la Sécurité des Stations de Sports d'Hiver) et autres acteurs de la montagne.

Bulletin neige & avalanches par téléphone au
0 892 68 10 20 Service 0,35 € / min + prix appel