Bulletin d'estimation du risque d'avalanche
(valable en dehors des pistes balisées et ouvertes)

MASSIF : Vercors

Rédigé le jeudi 19 février 2026 à 16h

Estimation des risques pour le : VENDREDI 20 FÉVRIER

FORTES CHUTES DE NEIGE VENTEES CETTE NUIT JUSQUE VENDREDI MATIN

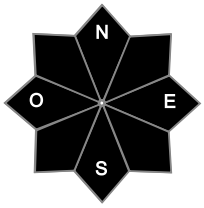

Altitude et couloirs

Indice de risque fort.

Départs spontanés : nombreuses avalanches, pouvant être de grande taille sous les chutes de neige. Ruptures de corniches..

Déclenchements provoqués : formations de nombreuses plaques avec la nouvelle neige et le vent, faciles à rompre des sommets aux forêts, parfois dans les clairières...

Indices de risque : 5 très fort - 4 fort - 3 marqué - 2 limité - 1 faible -- En noir : les pentes les plus dangereuses

Stabilité du manteau neigeux

Situation avalancheuse typique : neige fraîche neige ventée

Départs spontanés : nombreuses avalanches dans la nuit jusqu'à vendredi matin sur le massif pendant les chutes de neige ventées (cumul d'ici vendredi matin de 30 à 50 cm à partir de 1600/1700 m, localement plus sur les sommets). Ces avalanches pourraient être de grande taille et atteindre certains couloirs forestiers, jusqu'à assez basse altitude, prudence... A la fin des chutes de neige en matinée de vendredi, l'activité naturelle devrait progressivement décroitre mais de grosses corniches pourraient céder naturellement sous le vent de nord (actif jusque vendredi soir).

Déclenchements provoqués : de nouvelles plaques se forment sous les chutes de neige ventées jusque vendredi matin, puis sous le vent de nord ensuite. Plaques instables pouvant partir au passage d'un skieur/randonneur, avec une épaisseur de cassure pouvant être de 50 cm voire plus d'un 1m d'épaisseur, sur des largeurs non négligeables. Risque surtout des hauts sommets jusqu'en limite de forêt, mais elles peuvent descendre plus bas dans les couloirs en forêt. Rupture accidentelle non exclue en clairière de modeste altitude, suffisamment pentue.

Qualité de la neige

Qualification de l'enneigement : l'enneigement devient bon pour la saison dès 1200m, puis abondant au dessus de 1500 m environ, notamment dans les combes d'altitude... Crêtes parfois dégarnies/ grosses congères et corniches sommitales...

Limites skiables : vers 1100/1300 m... sur les pistes forestières/clairières...

Qualité de la neige vendredi : au matin, entre 30 et 50 cm de neige fraîche ventée au-dessus de 1600/1700 m environ mais souvent très irrégulière vers les crêtes et sommets du massif, et humide sous 1300/1400 m environ. D'anciennes grosses congères/corniches sont visibles, tandis que de nouvelles se forment d'ici vendredi soir sous le vent de nord.

Aperçu météo pour le vendredi 20 février

nuit	matin	après-midi	soir

Chutes de neige toute la nuit, faiblissantes au fil de la matinée de vendredi. Le vent de nord, lui, reste sensible toute la journée.

Pluie-Neige	1 100 m	900 m	1 100 m	
Iso 0 °C	1 400 m	1 400 m	1 500 m	1 600 m
Vent 1500 m	→ 40 km/h	↓ 45 km/h	↓ 40 km/h	↓ 45 km/h
Vent 2000 m	↓ 70 km/h	↓ 60 km/h	↓ 60 km/h	↓ 70 km/h

Épaisseur de neige hors-piste

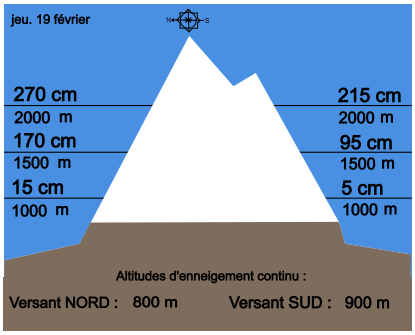

Précipitations à 1800 m

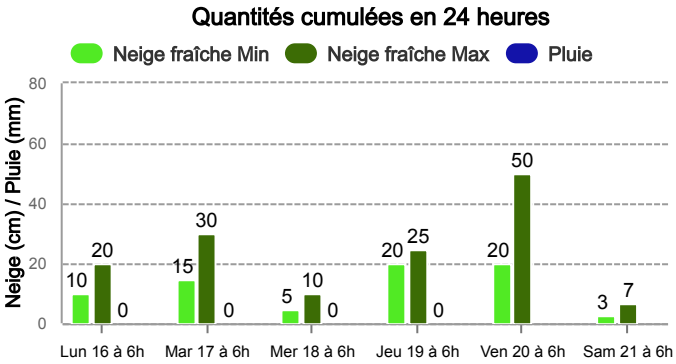

Tendance du samedi 21 février

Indice de risque fort

Le manteau reste instable vers les sommets ce samedi sur le massif malgré une météo qui s'améliore progressivement (anticyclone en formation). De plus un redoux s'amorce : iso 0°C à 2500 m samedi après-midi...

Pour consulter la vigilance en cours, veuillez vous rendre sur le site https://vigilance.meteofrance.fr/fr

Météo-France - 73 avenue de Paris, 94165 Saint-Mandé cedex - Contact : contact@meteo.fr

Rédigé par Météo-France avec la contribution des observateurs du réseau nivo-météorologiques. Partenariat : ANMSM (Maires de Stations de Montagne), DSF (Domaines Skiables de France), ADSP (Directeurs de Pistes et de la Sécurité des Stations de Sports d'Hiver) et autres acteurs de la montagne.

Bulletin neige & avalanches par téléphone au **0 892 68 10 20** Service 0,35 € / min + prix appel

RÉPUBLIQUE FRANÇAISE
Liberté Égalité Fraternité

METEO FRANCE
À VOS CÔTÉS, DANS UN CLIMAT QUI CHANGE

Bulletin d'estimation du risque d'avalanche

(valable en dehors des pistes balisées et ouvertes)

MASSIF : Vercors

Rédigé le jeudi 19 février 2026 à 16h

Conditions nivo-météo des 7 derniers jours

	ven. 13/02				sam. 14/02				dim. 15/02				lun. 16/02				mar. 17/02				mer. 18/02				jeu. 19/02			
	03h	09h	15h	21h	03h	09h	15h	21h	03h	09h	15h	21h	03h	09h	15h	21h	03h	09h	15h	21h	03h	09h	15h	21h	03h	09h	15h	21h
Météo																												
Vent (km/h)	50	20	35	25	20	25	50	55	50	40	40	50	55	65	75	80	75	65	45	15	45	20	40	90	60	30	50	70
à 2000m																												
Vent (km/h)	15	10	10	25	15	15	50	20	40	30	15	25	30	45	55	60	60	45	30	15	25	15	30	70	45	25	25	40
à 1500m																												

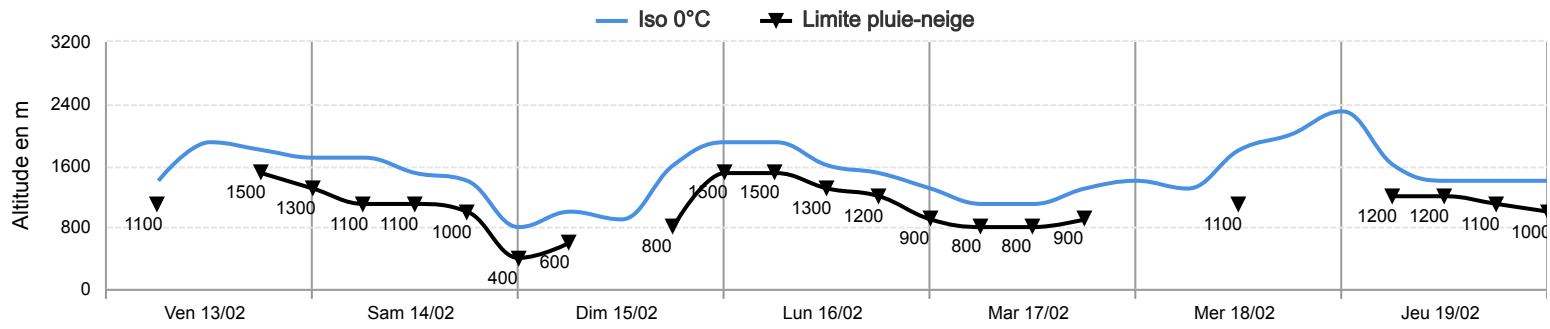

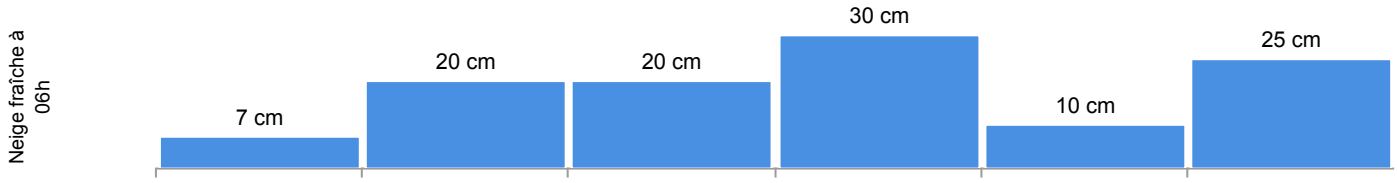

Risque d'avalanche	ven. 13/02	sam. 14/02	dim. 15/02	lun. 16/02	mar. 17/02	mer. 18/02	jeu. 19/02
	3	3	3	3	3	3	4

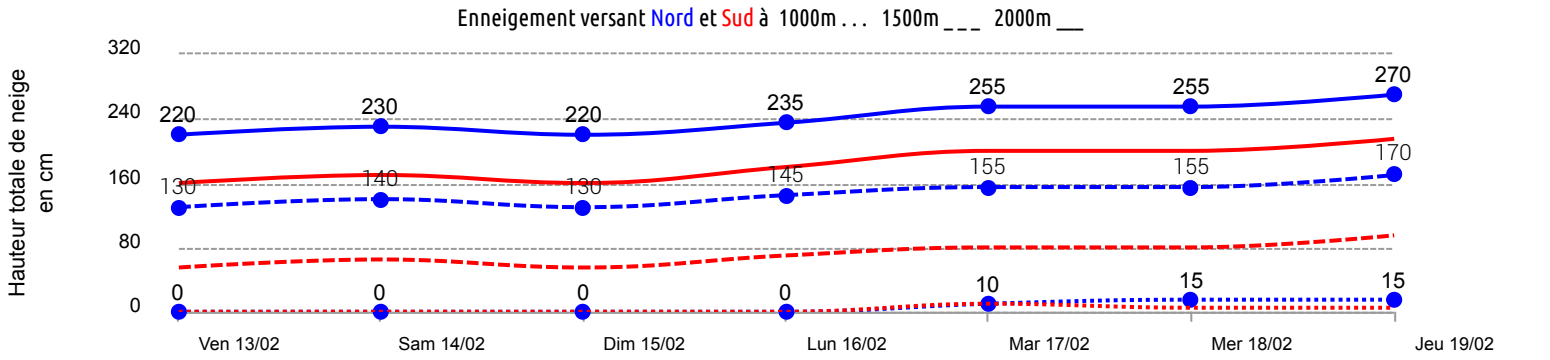

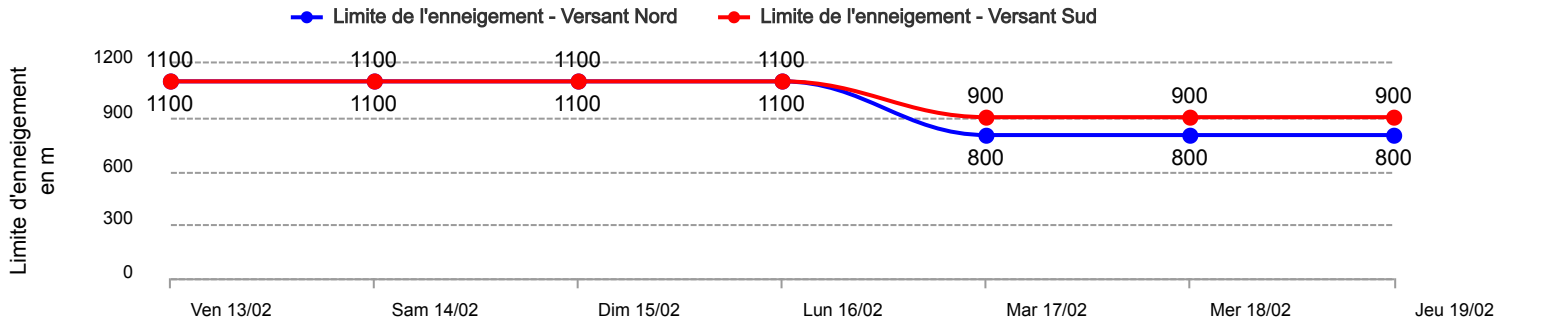

Pour consulter la vigilance en cours, veuillez vous rendre sur le site https://vigilance.meteofrance.fr/fr

Météo-France - 73 avenue de Paris, 94165 Saint-Mandé cedex - Contact : contact@meteo.fr

Rédigé par Météo-France avec la contribution des observateurs du réseau nivo-météorologiques. Partenariat : ANMSM (Maires de Stations de Montagne), DSF (Domaines Skiables de France), ADSP (Directeurs de Pistes et de la Sécurité des Stations de Sports d'Hiver) et autres acteurs de la montagne.

Bulletin neige & avalanches par téléphone au
0 892 68 10 20 Service 0,35 € / min + prix appel